Generation Run ID 4

Table of contents

Overview 1

Layout 1

Detailed results 1

Overview

Generation Run ID 4: Report pro Chart mit 10 Alt-Text-Varianten. Die Varianten sind pro Chart nach SBERT (desc) sortiert; Charts sind nach bestem SBERT gerankt.

Layout

Pro Chart:

- Zeile 1: chart_id
- Zeile 2: Chart
- Zeile 3–12: Top-10 Alt-Texte (links), sortiert nach SBERT Similarity score (generated vs golden standard alt text) + Scores (rechts). Scores rechts enthalten SBERT sowie LLM-as-judge für 6 Kriterien.

Detailed results

0819c8effbf081938ef522a369204c9b

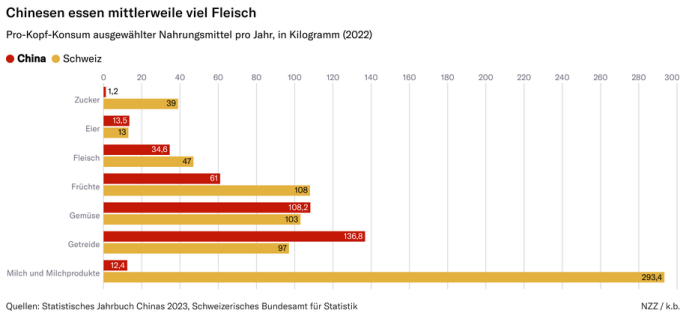

Golden standard
Short description (metadata): Waagrechtes Balkendiagramm. Titel: Chinesen essen mittlerweile viel Fleisch. Untertitel: Pro-Kopf-Konsum ausgewählter Nahrungsmittel pro Jahr, in Kilogramm (2022). Waagrechte Achse: 0 bis 300 Kilogramm. Senkrechte Achse: Zucker, Eier, Fleisch, Früchte, Gemüse, Getreide und Milch und Milchprodukte. Zwei Balken pro Nahrungsmittel: China (rot), Schweiz (gelb). **Short description (overview):** Die Schweiz konsumiert mehr Zucker, Früchte, Fleisch und besonders Milchprodukte. China konsumiert etwas mehr Eier und Gemüse sowie deutlich mehr Getreide. **Long description:** Pro-Kopf-Konsum in Kilogramm pro Kategorie. Zucker: China 1,2 , Schweiz 39. Eier: China 13,5 , Schweiz 13 . Fleisch: China 34,6 , Schweiz 47 . Früchte: China 61 , Schweiz 108 . Gemüse: China 108,2 , Schweiz 103. Getreide: China 136.8 , Schweiz 97.

1. Alt text **Short description (metadata):** Waagerechtes Balkendiagramm. Titel: Chinesen essen mittlerweile viel Fleisch. Untertitel: Pro-Kopf-Konsum ausgewählter Nahrungsmittel pro Jahr, in Kilogramm (2022). Waagrechte Achse: 0 bis 300 Kilogramm. Senkrechte Achse: Zucker, Eier, Fleisch, Früchte, Gemüse, Getreide, Milch und Milchprodukte. Pro Nahrungsmittel zwei Balken: China (Rot), Schweiz (Gelb). **Short description (overview):** Der Pro-Kopf-Konsum von Milch und Milchprodukten ist in der Schweiz mit Abstand am höchsten, während China mehr Getreide, Gemüse, Eier und Fleisch konsumiert. **Long description:** Der Pro-Kopf-Konsum von Milch und Milchprodukten beträgt in der Schweiz 293,4 Kilogramm, verglichen mit 12,4 Kilogramm in China. China konsumiert mehr Getreide (136,8 kg) als die Schweiz (97 kg), und auch mehr Gemüse (108,2 kg gegenüber 103 kg). Der Fleischkonsum ist in China mit 34,6 Kilogramm niedriger als in der Schweiz mit 47 Kilogramm. Bei den Eiern liegt China mit 13,5 Kilogramm leicht über der Schweiz mit 13 Kilogramm. Beim Zuckerkonsum dominiert die Schweiz mit 39 Kilogramm den Vergleich zu 1,2 Kilogramm in China.	**SBERT:** 0.95 **LLM as Judge:** *(n=1)* ▪ Clarity: 2 ▪ Completeness: 3 ▪ Conciseness: 1 ▪ PC: 2 ▪ Neutrality: 4 ▪ Correctness: 2
2. Alt text **Short description (metadata):** Waagerechtes Balkendiagramm. Titel: Chinesen essen mittlerweile viel Fleisch. Untertitel: Pro-Kopf-Konsum ausgewählter Nahrungsmittel pro Jahr, in Kilogramm (2022). Waagrechte Achse: 0 bis 300 Kilogramm. Senkrechte Achse: Zucker, Eier, Fleisch, Früchte, Gemüse, Getreide, Milch und Milchprodukte. Zwei Balken pro Kategorie: China (Rot), Schweiz (Gelb). **Short description (overview):** Der Pro-Kopf-Konsum in der Schweiz liegt bei den meisten der ausgewählten Nahrungsmittel höher als in China, wobei der Unterschied bei Milch und Milchprodukten am grössten ist. China konsumiert jedoch mehr Gemüse und Getreide. **Long description:** Der Konsum in Kilogramm pro Kopf und Jahr in China liegt bei Zucker bei 1,2, bei Eiern bei 13,5, bei Fleisch bei 34,6, bei Früchten bei 61, bei Gemüse bei 108,2, bei Getreide bei 136,8 und bei Milch und Milchprodukten bei 12,4. Für die Schweiz betragen die entsprechenden Mengen: 39 für Zucker, 13 für Eier, 47 für Fleisch, 108 für Früchte, 103 für Gemüse, 97 für Getreide und 293,4 für Milch und Milchprodukte.	**SBERT:** 0.94 **LLM as Judge:** *(n=1)* ▪ Clarity: 5 ▪ Completeness: 5 ▪ Conciseness: 1 ▪ PC: 5 ▪ Neutrality: 5 ▪ Correctness: 3

3. Alt text **Short description (metadata):** Waagerechtes Balkendiagramm. Titel: Chinesen essen mittlerweile viel Fleisch. Untertitel: Pro-Kopf-Konsum ausgewählter Nahrungsmittel pro Jahr, in Kilogramm (2022). Waagrechte Achse: 0 bis 300 Kilogramm. Senkrechte Achse: Zucker, Eier, Fleisch, Früchte, Gemüse, Getreide, Milch und Milchprodukte. Pro Kategorie ein Balken in zwei Farben: China (Rot), Schweiz (Gelb). **Short description (overview):** Der Pro-Kopf-Konsum der Schweiz übertrifft jenen Chinas bei Zucker, Fleisch, Früchten und Milchprodukten deutlich, während China mehr Gemüse und Getreide konsumiert. **Long description:** Der Konsum von Milch und Milchprodukten ist in der Schweiz mit 293,4 Kilogramm pro Kopf am höchsten und übertrifft China um ein Vielfaches (12,4 Kilogramm). Bei Zucker konsumiert die Schweiz 39 Kilogramm, China nur 1,2 Kilogramm. Die Schweiz isst auch mehr Fleisch (47 Kilogramm) und Früchte (108 Kilogramm) als China (34,6 bzw. 61 Kilogramm). China konsumiert mit 136,8 Kilogramm am meisten Getreide, gefolgt von der Schweiz mit 97 Kilogramm, und bei Gemüse mit 108,2 Kilogramm mehr als die Schweiz mit 103 Kilogramm. Der Eierkonsum ist in beiden Ländern fast gleich (China: 13,5 Kilogramm, Schweiz: 13 Kilogramm).	**SBERT:** 0.94 **LLM as Judge:** *(n=1)* ▪ Clarity: 5 ▪ Completeness: 5 ▪ Conciseness: 1 ▪ PC: 3 ▪ Neutrality: 5 ▪ Correctness: 5
4. Alt text **Short description (metadata):** Waagerechtes Balkendiagramm. Titel: Chinesen essen mittlerweile viel Fleisch. Untertitel: Pro-Kopf-Konsum ausgewählter Nahrungsmittel pro Jahr, in Kilogramm (2022). Waagrechte Achse: 0 bis 300 Kilogramm. Senkrechte Achse: Zucker, Eier, Fleisch, Früchte, Gemüse, Getreide, Milch und Milchprodukte. Zwei Balken pro Kategorie: China (rot), Schweiz (gelb). **Short description (overview):** Der Pro-Kopf-Konsum von Getreide und Gemüse ist in China am höchsten, während der Konsum von Zucker, Fleisch, Früchten, und Milchprodukten in der Schweiz deutlich höher ist. **Long description:** Der Konsum an Milch und Milchprodukten ist in der Schweiz mit 293,4 Kilogramm pro Kopf und Jahr mit Abstand am höchsten (China: 12,4 Kilogramm). Der Konsum von Früchten (108 Kilogramm) und Fleisch (47 Kilogramm) ist in der Schweiz ebenfalls höher als in China (Früchte: 61 Kilogramm, Fleisch: 34,6 Kilogramm). In China ist der Getreidekonsum mit 136,8 Kilogramm deutlich höher als in der Schweiz mit 97 Kilogramm. Beim Gemüsekonsum liegen beide Länder mit 108,2 Kilogramm (China) und 103 Kilogramm (Schweiz) nah beieinander.	**SBERT:** 0.93 **LLM as Judge:** *(n=1)* ▪ Clarity: 4 ▪ Completeness: 2 ▪ Conciseness: 2 ▪ PC: 4 ▪ Neutrality: 5 ▪ Correctness: 5

5. Alt text **Short description (metadata):** Waagerechtes Balkendiagramm. Titel: Chinesen essen mittlerweile viel Fleisch. Untertitel: Pro-Kopf-Konsum ausgewählter Nahrungsmittel pro Jahr, in Kilogramm (2022). Waagrechte Achse: 0 bis 300 Kilogramm. Senkrechte Achse: Zucker, Eier, Fleisch, Früchte, Gemüse, Getreide, Milch und Milchprodukte. Pro Kategorie ein Balken in zwei Farben: China (Rot), Schweiz (Gelb). **Short description (overview):** Im Jahr 2022 liegt der Pro-Kopf-Konsum von Milch und Milchprodukten in der Schweiz mit 293,4 Kilogramm pro Jahr deutlich über dem Chinas mit 12,4 Kilogramm. Bei anderen Lebensmitteln wie Fleisch, Zucker und Früchten konsumieren Schweizer ebenfalls mehr, während bei Gemüse, Getreide und Eiern die Konsumwerte in China höher oder vergleichbar sind. **Long description:** Der Konsum von Fleisch liegt in der Schweiz bei 47,0 Kilogramm, in China bei 34,6 Kilogramm. Bei Früchten konsumieren Schweizer mit 108,0 Kilogramm jährlich ebenfalls mehr als Chinesen mit 61,0 Kilogramm. Chinesen verbrauchen hingegen mehr Gemüse (108,2 kg im Vergleich zu 103,0 kg in der Schweiz) und Getreide (136,8 kg im Vergleich zu 97,0 kg in der Schweiz). Der Eierkonsum pro Kopf ist in beiden Ländern mit 13,5 kg in China und 13,0 kg in der Schweiz nahezu identisch. Schweizer konsumieren sehr viel mehr Zucker (39,0 kg vs. 1,2 kg) sowie Milch und Milchprodukte (293,4 kg vs. 12,4 kg).	**SBERT:** 0.93 **LLM as Judge:** *(n=1)* ▪ Clarity: 4 ▪ Completeness: 5 ▪ Conciseness: 1 ▪ PC: 5 ▪ Neutrality: 5 ▪ Correctness: 5
6. Alt text **Short description (metadata):** Waagerechtes Balkendiagramm. Titel: Chinesen essen mittlerweile viel Fleisch. Untertitel: Pro-Kopf-Konsum ausgewählter Nahrungsmittel pro Jahr, in Kilogramm (2022). Waagrechte Achse: 0 bis 300 Kilogramm. Senkrechte Achse: Zucker, Eier, Fleisch, Früchte, Gemüse, Getreide, Milch und Milchprodukte. Zwei Balken pro Kategorie: China (Rot), Schweiz (Gelb). **Short description (overview):** Der Pro-Kopf-Konsum von Milch und Milchprodukten in der Schweiz ist mit 293,4 Kilogramm pro Jahr deutlich am höchsten, während China mehr Gemüse, Getreide und Eier konsumiert. **Long description:** Der Konsum an Milch und Milchprodukten in der Schweiz beträgt 293,4 Kilogramm gegenüber 12,4 in China. Beim Getreide konsumiert China 136,8 Kilogramm, die Schweiz 97,0 Kilogramm. Bei Fleisch verbraucht die Schweiz 47,0 Kilogramm, China 34,6. China konsumiert zudem mehr Gemüse (108,2 Kilogramm versus 103,0) und Eier (13,5 Kilogramm versus 13,0). Der Zuckerkonsum ist in der Schweiz mit 39,0 Kilogramm viel höher als in China mit 1,2 Kilogramm.	**SBERT:** 0.93 **LLM as Judge:** *(n=1)* ▪ Clarity: 4 ▪ Completeness: 4 ▪ Conciseness: 1 ▪ PC: 2 ▪ Neutrality: 5 ▪ Correctness: 5

7. Alt text **Short description (metadata):** Waagerechtes Balkendiagramm. Titel: Chinesen essen mittlerweile viel Fleisch. Untertitel: Pro-Kopf-Konsum ausgewählter Nahrungsmittel pro Jahr, in Kilogramm (2022). Waagrechte Achse: 0 bis 300 Kilogramm. Senkrechte Achse: Zucker, Eier, Fleisch, Früchte, Gemüse, Getreide, Milch und Milchprodukte. Zwei Balken pro Kategorie: China (Rot), Schweiz (Gelb). **Short description (overview):** Der Pro-Kopf-Konsum von Milch und Milchprodukten sowie Früchten ist in der Schweiz deutlich höher als in China, während China mehr Getreide und Gemüse konsumiert als die Schweiz. **Long description:** Der Pro-Kopf-Konsum in Kilogramm ist beim Zucker in der Schweiz mit 39 Kilogramm erheblich höher als in China mit 1,2 Kilogramm. Beim Fleisch konsumiert die Schweiz mit 47 Kilogramm mehr als China mit 34,6 Kilogramm. Bei Früchten (108 zu 61 Kilogramm) und Milch und Milchprodukten (293,4 zu 12,4 Kilogramm) führt die Schweiz. China konsumiert mehr Gemüse (108,2 zu 103 Kilogramm) und Getreide (136,8 zu 97 Kilogramm) als die Schweiz.	**SBERT:** 0.93 **LLM as Judge:** *(n=1)* ▪ Clarity: 4 ▪ Completeness: 2 ▪ Conciseness: 1 ▪ PC: 3 ▪ Neutrality: 3 ▪ Correctness: 5
8. Alt text **Short description (metadata):** Waagerechtes Balkendiagramm. Titel: Chinesen essen mittlerweile viel Fleisch. Untertitel: Pro-Kopf-Konsum ausgewählter Nahrungsmittel pro Jahr, in Kilogramm (2022). Waagrechte Achse: 0 bis 300 Kilogramm. Senkrechte Achse: Zucker, Eier, Fleisch, Früchte, Gemüse, Getreide, Milch und Milchprodukte. Pro Nährstoffgruppe zwei Balken: China (Rot), Schweiz (Gelb). **Short description (overview):** Der Pro-Kopf-Konsum von Milch und Milchprodukten sowie von Zucker ist in der Schweiz deutlich höher als in China. China konsumiert mehr Getreide, Gemüse und Früchte, während der Fleischkonsum in der Schweiz höher ist. **Long description:** Der größte Unterschied besteht beim Konsum von Milch und Milchprodukten, der in der Schweiz mit 293,4 Kilogramm pro Kopf fast 24-mal so hoch ist wie in China (12,4 Kilogramm). Auch beim Zucker liegt die Schweiz mit 39 Kilogramm weit vor China (1,2 Kilogramm). Beim Fleisch verbraucht die Schweiz 47 Kilogramm und China 34,6 Kilogramm. Im Gegensatz dazu konsumiert China mit 136,8 Kilogramm am meisten Getreide, mehr als die Schweiz mit 97 Kilogramm. Bei Gemüse liegt China mit 108,2 Kilogramm nur knapp vor der Schweiz (103 Kilogramm). Beim Obstkonsum liegt die Schweiz bei 108 Kilogramm und China bei 61 Kilogramm. Der Eierkonsum ist mit 13,5 Kilogramm in China und 13 Kilogramm in der Schweiz fast gleich.	**SBERT:** 0.92 **LLM as Judge:** *(n=1)* ▪ Clarity: 3 ▪ Completeness: 5 ▪ Conciseness: 1 ▪ PC: 3 ▪ Neutrality: 5 ▪ Correctness: 3

9. Alt text **Short description (metadata):** Waagerechtes Balkendiagramm. Titel: Chinesen essen mittlerweile viel Fleisch. Untertitel: Pro-Kopf-Konsum ausgewählter Nahrungsmittel pro Jahr, in Kilogramm (2022). Waagrechte Achse: 0 bis 300 Kilogramm. Senkrechte Achse: Zucker, Eier, Fleisch, Früchte, Gemüse, Getreide, Milch und Milchprodukte. Pro Kategorie ein Balken in zwei Farben: China (Rot), Schweiz (Gelb). **Short description (overview):** Der Pro-Kopf-Konsum von Milch und Milchprodukten sowie Früchten und Zucker ist in der Schweiz deutlich höher, während der Konsum von Gemüse, Getreide, Fleisch und Eiern zwischen den beiden Ländern näher beieinander liegt. **Long description:** Der Konsum in der Schweiz ist bei Milchprodukten (293,4 kg), Früchten (108 kg) und Zucker (39 kg) markant höher als in China (Milchprodukte: 12,4 kg; Früchte: 61 kg; Zucker: 1,2 kg). Der Getreidekonsum ist in China mit 136,8 kg höher als in der Schweiz (97 kg). Beim Fleischkonsum führt die Schweiz mit 47 kg gegenüber 34,6 kg in China. Der Gemüsekonsum in China ist mit 108,2 kg leicht höher als in der Schweiz (103 kg). Beim Eierkonsum liegen China bei 13,5 kg und die Schweiz bei 13 kg sehr nahe beieinander.	**SBERT:** 0.91 **LLM as Judge:** *(n=1)* ▪ Clarity: 5 ▪ Completeness: 5 ▪ Conciseness: 1 ▪ PC: 5 ▪ Neutrality: 5 ▪ Correctness: 5
10. Alt text **Short description (metadata):** Waagerechtes Balkendiagramm. Titel: Chinesen essen mittlerweile viel Fleisch. Untertitel: Pro-Kopf-Konsum ausgewählter Nahrungsmittel pro Jahr, in Kilogramm (2022). Waagrechte Achse: 0 bis 300 Kilogramm. Senkrechte Achse: Sieben Nahrungsmittelkategorien. Zwei Balken pro Kategorie: China (Rot), Schweiz (Gelb). **Short description (overview):** Der Pro-Kopf-Konsum von Milch und Milchprodukten in der Schweiz übersteigt den chinesischen Konsum bei weitem, während China bei Getreide und Gemüse führend ist. **Long description:** Der Konsum von Milch und Milchprodukten in der Schweiz ist mit 293,4 Kilogramm pro Jahr am höchsten, verglichen mit 12,4 Kilogramm in China. China konsumiert mit 136,8 Kilogramm am meisten Getreide, die Schweiz 97 Kilogramm. Beim Gemüsekonsum liegt China mit 108,2 Kilogramm vor der Schweiz mit 103 Kilogramm. Die Schweiz konsumiert mehr Fleisch (47 Kilogramm) und Früchte (108 Kilogramm) als China (34,6 bzw. 61 Kilogramm).	**SBERT:** 0.91 **LLM as Judge:** *(n=1)* ▪ Clarity: 5 ▪ Completeness: 3 ▪ Conciseness: 1 ▪ PC: 3 ▪ Neutrality: 5 ▪ Correctness: 5

016b459adf53c4e44c03cc7e7078bb83

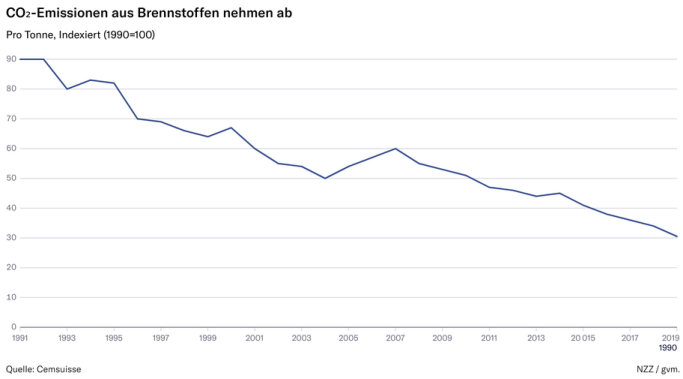

Golden standard
Short description (metadata): Liniendiagramm. Titel: CO -Emissionen aus Brennstoffen nehmen ab. Untertitel: Pro Tonne, indexiert (1990 = 100). Waagrechte Achse: Zeitraum 1991 bis 2019. Senkrechte Achse: Index von 0 bis 90. Daten: Jährliche Werte. **Short description (overview):** Die Emissionen sinken über den Zeitraum kontinuierlich mit leichten Schwankungen. **Long description:** Vom Referenzwert 1990 = 100 bis 2004 sinkt der Index auf 50. Zwischen 2004 und 2007 steigt der Index leicht an auf rund 60. Ab 2007 sinkt der Index bis 2019 auf den Tiefstwert von 30.

1. Alt text **Short description (metadata):** Liniendiagramm. Titel: CO -Emissionen aus Brennstoffen nehmen ab. Untertitel: Pro Tonne, Indexiert (1990=100). Waagerechte Achse: Zeitraum von 1990 bis 2019. Senkrechte Achse: 0 bis 90 Indexpunkte. Daten: Jährliche Werte. **Short description (overview):** Die CO -Emissionen pro Tonne, indexiert auf 1990=100, sinken über den gesamten Zeitraum von 1990 bis 2019 deutlich, weisen aber leichte Schwankungen auf. **Long description:** Die Emissionen starten 1990 bei 100 Indexpunkten und sinken bis 1993 auf 80, steigen dann bis 1995 kurz auf 82, bevor sie bis 2004 auf ein Tief von 50 sinken. Es folgt ein Anstieg bis 2007 auf 60 und ein weiterer deutlicher Rückgang auf 30,5 Indexpunkte im Jahr 2019.	**SBERT:** 0.94 **LLM as Judge:** *(n=1)* ▪ Clarity: 5 ▪ Completeness: 4 ▪ Conciseness: 2 ▪ PC: 5 ▪ Neutrality: 5 ▪ Correctness: 5
2. Alt text **Short description (metadata):** Liniendiagramm. Titel: CO -Emissionen aus Brennstoffen nehmen ab. Untertitel: Pro Tonne, Indexiert (1990=100). Waagerechte Achse: Zeitraum 1990 bis 2019. Senkrechte Achse: 0 bis 90 Indexpunkte. Daten: Jährliche Werte. **Short description (overview):** Die CO -Emissionen pro Tonne, indexiert auf 1990, sinken im gesamten Zeitraum von 1990 bis 2019 deutlich und weisen nur kleinere Schwankungen auf. **Long description:** Die Emissionen starten 1990 bei 100 und sinken mit einigen Schwankungen bis 2004 auf den Wert 50, bevor sie bis 2007 auf 60 steigen. Danach sinken sie kontinuierlich bis zum Endwert 30.5 im Jahr 2019.	**SBERT:** 0.94 **LLM as Judge:** *(n=1)* ▪ Clarity: 4 ▪ Completeness: 4 ▪ Conciseness: 1 ▪ PC: 5 ▪ Neutrality: 3 ▪ Correctness: 4
3. Alt text **Short description (metadata):** Liniendiagramm. Titel: CO -Emissionen aus Brennstoffen nehmen ab. Untertitel: Pro Tonne, Indexiert (1990=100). Waagerechte Achse: Zeitraum 1991 bis 2019. Senkrechte Achse: 0 bis 90 Indexpunkte. Daten: Jährliche Werte. **Short description (overview):** Die CO -Emissionen pro Tonne, indexiert auf 1990 gleich 100, zeigen über den gesamten Zeitraum von 1991 bis 2019 einen deutlichen und kontinuierlichen Rückgang, lediglich unterbrochen durch kleinere Schwankungen. **Long description:** Der Index startet 1991 bei 90 und sinkt zunächst leicht bis 1993 auf 80. Nach einer leichten Erholung sinkt der Index bis 1999 auf 64. Bis 2007 steigt der Index wieder auf 60, sinkt danach jedoch mit leicht wechselndem Tempo kontinuierlich auf seinen Tiefstwert von etwa 30,5 im Jahr 2019.	**SBERT:** 0.93 **LLM as Judge:** *(n=1)* ▪ Clarity: 4 ▪ Completeness: 4 ▪ Conciseness: 2 ▪ PC: 5 ▪ Neutrality: 5 ▪ Correctness: 4

4. Alt text **Short description (metadata):** Liniendiagramm. Titel: CO -Emissionen aus Brennstoffen nehmen ab. Untertitel: Pro Tonne, Indexiert (1990=100). Waagerechte Achse: Zeitraum 1991 bis 2019. Senkrechte Achse: 0 bis 90 Indexpunkte. Daten: Jährliche Werte. **Short description (overview):** Die CO -Emissionen pro Tonne, indexiert auf das Jahr 1990 (Index 100), zeigen über den betrachteten Zeitraum von 1991 bis 2019 einen deutlichen Abwärtstrend, mit einigen zwischenzeitlichen Schwankungen. **Long description:** Ausgehend vom Index 100 im Jahr 1990 sinken die Emissionen bis 1999 auf den Index 64, mit einem kurzzeitigen Anstieg auf 83 im Jahr 1994. Nach einem weiteren leichten Anstieg bis 2007 auf 60 sinken die Emissionen kontinuierlich und erreichen 2019 ihren Tiefpunkt bei 30,5.	**SBERT:** 0.92 **LLM as Judge:** *(n=1)* ▪ Clarity: 5 ▪ Completeness: 3 ▪ Conciseness: 2 ▪ PC: 5 ▪ Neutrality: 5 ▪ Correctness: 5
5. Alt text **Short description (metadata):** Liniendiagramm. Titel: CO -Emissionen aus Brennstoffen nehmen ab. Untertitel: Pro Tonne, Indexiert (1990=100). Waagerechte Achse: Zeitraum von 1990 bis 2019. Senkrechte Achse: Ausschnitt von 0 bis 90. Daten: Jährliche Werte. **Short description (overview):** Die CO -Emissionen pro Tonne, indexiert auf 1990, sinken im betrachteten Zeitraum von 1990 bis 2019 deutlich und weisen dabei mittlere Schwankungen auf. **Long description:** 1990 liegen die Emissionen bei 100. Bis 1993 sinken sie auf 80, steigen bis 1995 auf 82 und sinken danach deutlich bis 1999 auf 64. Bis 2007 steigen die Werte auf 60, wonach sie bis 2019 auf den Tiefstwert von zirka 30 sinken.	**SBERT:** 0.92 **LLM as Judge:** *(n=1)* ▪ Clarity: 4 ▪ Completeness: 4 ▪ Conciseness: 2 ▪ PC: 5 ▪ Neutrality: 5 ▪ Correctness: 4
6. Alt text **Short description (metadata):** Liniendiagramm. Titel: CO -Emissionen aus Brennstoffen nehmen ab. Untertitel: Pro Tonne, Indexiert (1990=100). Waagerechte Achse: Zeitraum von 1990 bis 2019. Senkrechte Achse: Ausschnitt von 0 bis 90. Daten: Jährliche Werte. **Short description (overview):** Die CO -Emissionen pro Tonne, indexiert auf 1990, sinken im Zeitraum von 1990 bis 2019 deutlich um fast 70 Prozent mit leichten Schwankungen. **Long description:** Die Emissionen starten 1990 bei 100 und sinken stark bis 1996 auf 70. Nach Schwankungen um 60 von 2000 bis 2007, mit einem Hoch bei 60 im Jahr 2007, sinken sie kontinuierlich von 2008 bis 2019 auf den Tiefstwert von 30,5, was einer Reduktion von fast 70 Prozent entspricht.	**SBERT:** 0.89 **LLM as Judge:** *(n=1)* ▪ Clarity: 5 ▪ Completeness: 4 ▪ Conciseness: 2 ▪ PC: 5 ▪ Neutrality: 3 ▪ Correctness: 3
7. Alt text **Short description (metadata):** Liniendiagramm. Titel: CO -Emissionen aus Brennstoffen nehmen ab. Untertitel: Pro Tonne, Indexiert (1990=100). Waagerechte Achse: Zeitraum von 1990 bis 2019. Senkrechte Achse: Ausschnitt 0 bis 90 Indexpunkte. Daten: Jährliche Werte. **Short description (overview):** Die CO -Emissionen pro Tonne, indexiert auf 1990, zeigen über den gesamten Zeitraum von 1990 bis 2019 einen deutlichen Abwärtstrend, unterbrochen durch kurzfristige Schwankungen. **Long description:** Beginnend bei 100 im Jahr 1990, sinken die Emissionen auf einen Tiefpunkt von 50 im Jahr 2004, steigen kurz auf 60 im Jahr 2007 und setzen ihren Rückgang bis 30.5 im Jahr 2019 fort. Die stärksten Rückgänge finden am Anfang und Ende des Zeitraums statt.	**SBERT:** 0.86 **LLM as Judge:** *(n=1)* ▪ Clarity: 5 ▪ Completeness: 4 ▪ Conciseness: 2 ▪ PC: 5 ▪ Neutrality: 5 ▪ Correctness: 3

8. Alt text **Short description (metadata):** Liniendiagramm. Titel: CO -Emissionen aus Brennstoffen nehmen ab. Untertitel: Pro Tonne, Indexiert (1990=100). Waagerechte Achse: Zeitraum von 1990 bis 2019. Senkrechte Achse: Ausschnitt 0 bis 90 Indexpunkte. Daten: Jährliche Werte. **Short description (overview):** Die CO -Emissionen pro Tonne, basierend auf dem Index 1990 gleich 100, sinken im gesamten Zeitraum von 1990 bis 2019 kontinuierlich, jedoch mit deutlichen Schwankungen insbesondere in der ersten Dekade. **Long description:** Der Index beginnt 1990 bei 100 und sinkt bis 2019 auf 30,5, was einer Reduktion um fast 70 Prozent entspricht. Die grössten Rückgänge finden zwischen 1995 und 1996 sowie zwischen 2007 und 2019 statt. Ein vorübergehender Anstieg wird zwischen 2003 und 2007 verzeichnet, danach setzt sich der Abwärtstrend fort.	**SBERT:** 0.86 **LLM as Judge:** *(n=1)* ▪ Clarity: 5 ▪ Completeness: 4 ▪ Conciseness: 2 ▪ PC: 5 ▪ Neutrality: 5 ▪ Correctness: 2
9. Alt text **Short description (metadata):** Liniendiagramm. Titel: CO -Emissionen aus Brennstoffen nehmen ab. Untertitel: Pro Tonne, Indexiert (1990=100). Waagerechte Achse: Zeitraum 1991 bis 2019. Senkrechte Achse: Ausschnitt 0 bis 90 Indexpunkte. Daten: Jährliche Werte. **Short description (overview):** Die CO -Emissionen pro Tonne, indexiert auf 1990 (Wert 100), sinken über den gesamten Zeitraum von 1991 bis 2019 mit zwischenzeitlichen leichten Anstiegen, wobei der Rückgang in den letzten Jahren stärker ausgeprägt ist. **Long description:** Der Index beginnt 1991 mit 90 und sinkt bis 1993 auf 80. Nach einem Anstieg auf 83 im Jahr 1994 und einer leichten Stabilisierung folgt bis 2004 ein deutlicher Rückgang auf 50. Bis 2007 steigt der Wert wieder auf 60, bevor er bis 2019 auf den Tiefstwert von 30,5 sinkt, mit nur geringfügigen Schwankungen.	**SBERT:** 0.86 **LLM as Judge:** *(n=1)* ▪ Clarity: 5 ▪ Completeness: 4 ▪ Conciseness: 2 ▪ PC: 5 ▪ Neutrality: 5 ▪ Correctness: 5
10. Alt text **Short description (metadata):** Liniendiagramm. Titel: CO -Emissionen aus Brennstoffen nehmen ab. Untertitel: Pro Tonne, Indexiert (1990=100). Waagerechte Achse: Zeitraum 1991 bis 2019. Senkrechte Achse: Ausschnitt 0 bis 90 Indexpunkte. Daten: Jährliche Werte. **Short description (overview):** Die CO -Emissionen pro Tonne sinken zwischen 1991 und 2019 deutlich, mit einigen kurzfristigen Anstiegen, aber einem klaren Abwärtstrend insgesamt. **Long description:** 1991 und 1992 liegen die Werte bei 90 Indexpunkten. Sie sinken auf 80 im Jahr 1993, steigen kurz auf 83 im Jahr 1994 und fallen danach schrittweise bis zum Tiefpunkt von 50 im Jahr 2004. Nach einem Wiederanstieg auf 60 im Jahr 2007 setzen die Emissionen den mehrheitlich kontinuierlichen Rückgang bis 2019 fort, wo der letzte Wert bei 30.5 liegt.	**SBERT:** 0.86 **LLM as Judge:** *(n=1)* ▪ Clarity: 5 ▪ Completeness: 4 ▪ Conciseness: 2 ▪ PC: 5 ▪ Neutrality: 4 ▪ Correctness: 5

014e6bf3927ddaf505c8053e37c2dd5a

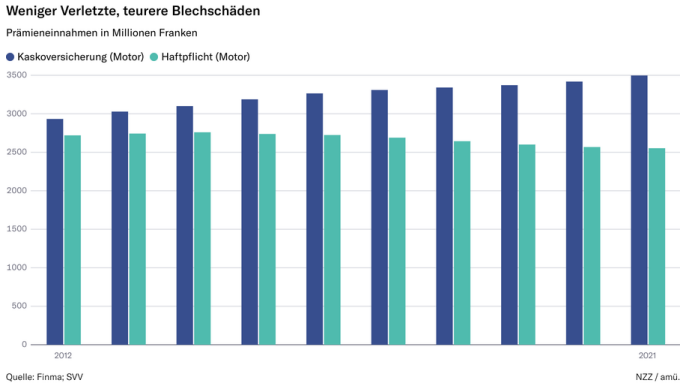

Golden standard

Short description (metadata): Senkrechtes Balkendiagramm. Titel: Weniger Verletzte, teurere Blechschäden. Untertitel: Prämieneinnahmen in Millionen Franken. Waagrechte Achse: 2012 bis 2021. Senkrechte Achse: 0 bis 3500 Millionen Franken. Zwei Balken pro Jahr: Kaskoversicherung (Motor, blau), Haftpflicht (Motor, türkis).

Short description (overview): Die Prämieneinnahmen aus Kaskoversicherungen steigen über die Jahre leicht, während die aus Haftpflichtversicherungen tendenziell leicht sinken.

Long description: Prämieneinnahmen aus Kaskoversicherungen steigen von knapp 3000 auf rund 3500 Millionen Franken. Einnahmen aus Haftpflichtversicherungen sinken von etwa 2700 auf rund 2500 Millionen Franken. Dadurch vergrössert sich die Differenz zwischen den beiden Versicherungsarten von 200 auf knapp 1000 Millionen Franken.

1. Alt text

Short description (metadata): Senkrechtes Balkendiagramm. Titel: Weniger Verletzte, teurere Blechschäden. Untertitel: Prämieneinnahmen in Millionen Franken. Waagrechte Achse: Zeitreihe von 2012 bis 2021. Senkrechte Achse: Null bis 3500 Millionen Franken. Zwei Balken pro Jahr: Kaskoversicherung (Motor) (dunkelblau), Haftpflicht (Motor) (türkis).

Short description (overview): Die Prämieneinnahmen aus der Kaskoversicherung (Motor) steigen kontinuierlich, während die Einnahmen aus der Haftpflichtversicherung (Motor) über den gesamten Zeitraum leicht sinken und im Jahr 2021 unter rund 2600 Millionen Franken liegen.

Long description: Die Einnahmen aus der Kaskoversicherung steigen von rund 2933 Millionen Franken im Jahr 2012 auf rund 3498 Millionen Franken im Jahr 2021. Im Unterschied dazu sinken die Einnahmen aus der Haftpflichtversicherung von rund 2720 Millionen Franken auf rund 2553 Millionen Franken im Jahr 2021. Im Jahr 2021 sind die Einnahmen aus der Kaskoversicherung um 945 Millionen Franken höher als die aus der Haftpflichtversicherung.

SBERT: 0.93

LLM as Judge: *(n=1)*

- Clarity: 5
- Completeness: 5
- Conciseness: 1
- PC: 5
- Neutrality: 5
- Correctness: 5

2. Alt text **Short description (metadata):** Senkrechtes Balkendiagramm. Titel: Weniger Verletzte, teurere Blechschäden. Untertitel: Prämieneinnahmen in Millionen Franken. Waagrechte Achse: Zeitreihe von 2012 bis 2021. Senkrechte Achse: 0 bis 3500 Millionen Franken. Zwei Balken pro Jahr: Kaskoversicherung (Motor) (dunkelblau), Haftpflicht (Motor) (türkis). **Short description (overview):** Die Prämieneinnahmen der Kaskoversicherung steigen im betrachteten Zeitraum kontinuierlich an, während die Einnahmen aus der Haftpflichtversicherung leicht sinken. **Long description:** Die Prämieneinnahmen aus der Kaskoversicherung steigen von rund 2933 Millionen Franken im Jahr 2012 auf etwa 3498 Millionen Franken im Jahr 2021. Im selben Zeitraum sinken die Prämieneinnahmen aus der Haftpflichtversicherung leicht von etwa 2720 Millionen Franken auf rund 2553 Millionen Franken. Die Prämieneinnahmen der Kaskoversicherung sind in jedem Jahr höher als die der Haftpflichtversicherung.	**SBERT:** 0.92 **LLM as Judge:** *(n=1)* ▪ Clarity: 5 ▪ Completeness: 5 ▪ Conciseness: 2 ▪ PC: 5 ▪ Neutrality: 5 ▪ Correctness: 5
3. Alt text **Short description (metadata):** Senkrechtes Balkendiagramm. Titel: Weniger Verletzte, teurere Blechschäden. Untertitel: Prämieneinnahmen in Millionen Franken. Waagrechte Achse: Zeitreihe von 2012 bis 2021 (in Jahresschritten). Senkrechte Achse: Null bis 3500 Millionen Franken. Zwei Balken pro Jahr: Kaskoversicherung (Motor) (dunkelblau), Haftpflicht (Motor) (türkis). **Short description (overview):** Die Prämieneinnahmen aus der Kaskoversicherung (Motor) steigen kontinuierlich, während die Einnahmen aus der Haftpflichtversicherung (Motor) leicht sinken, was zu einer stetig grösser werdenden Differenz zwischen den beiden Serien führt. **Long description:** Die Einnahmen aus der Kaskoversicherung (Motor) steigen von 2933 Millionen Franken im Jahr 2012 auf 3498 Millionen Franken im Jahr 2021. Im Gegensatz dazu sinken die Einnahmen aus der Haftpflichtversicherung (Motor) von 2720 Millionen Franken im Jahr 2012 auf 2553 Millionen Franken im Jahr 2021, mit Ausnahme eines leichten Anstiegs im Jahr 2013 und 2014. Im gesamten Zeitraum sind die Prämieneinnahmen aus der Kaskoversicherung höher als diejenigen aus der Haftpflichtversicherung.	**SBERT:** 0.91 **LLM as Judge:** *(n=1)* ▪ Clarity: 5 ▪ Completeness: 5 ▪ Conciseness: 1 ▪ PC: 5 ▪ Neutrality: 5 ▪ Correctness: 5
4. Alt text **Short description (metadata):** Senkrechtes Balkendiagramm. Titel: Weniger Verletzte, teurere Blechschäden. Untertitel: Prämieneinnahmen in Millionen Franken. Waagrechte Achse: Zeitreihe von 2012 bis 2021. Senkrechte Achse: 0 bis 3500 Millionen Franken. Zwei Balken pro Jahr: Kaskoversicherung (Motor) (dunkelblau), Haftpflicht (Motor) (türkis). **Short description (overview):** Die Prämieneinnahmen der Kaskoversicherung (Motor) sind von 2012 bis 2021 stetig gestiegen, während die Einnahmen der Haftpflichtversicherung (Motor) im gleichen Zeitraum gesunken sind. **Long description:** Die Einnahmen der Kaskoversicherung (Motor) steigen von 2933 Millionen Franken im Jahr 2012 auf 3498 Millionen Franken im Jahr 2021. Die Einnahmen der Haftpflichtversicherung (Motor) sinken von 2720 Millionen Franken im Jahr 2012 auf 2553 Millionen Franken im Jahr 2021. Die Kaskoversicherungsprämien übertreffen die Haftpflichtversicherungsprämien in jedem Jahr des Zeitraums.	**SBERT:** 0.91 **LLM as Judge:** *(n=1)* ▪ Clarity: 5 ▪ Completeness: 5 ▪ Conciseness: 1 ▪ PC: 5 ▪ Neutrality: 5 ▪ Correctness: 5

5. Alt text **Short description (metadata):** Senkrechtes Balkendiagramm. Titel: Weniger Verletzte, teurere Blechschäden. Untertitel: Prämieneinnahmen in Millionen Franken. Waagrechte Achse: Zeitreihe von 2012 bis 2021 (jährlich). Senkrechte Achse: 0 bis 3500 Millionen Franken. Zwei Balken pro Jahr: Kaskoversicherung (Motor) (dunkelblau), Haftpflicht (Motor) (hellgrün). **Short description (overview):** Die Prämieneinnahmen aus der Kaskoversicherung (Motor) stiegen im Beobachtungszeitraum kontinuierlich an, während die Einnahmen aus der Haftpflichtversicherung (Motor) sanken. Die Kaskoversicherung erwirtschaftete stets höhere Einnahmen als die Haftpflichtversicherung. **Long description:** Die Einnahmen der Kaskoversicherung stiegen von 2933 Millionen Franken im Jahr 2012 auf 3498 Millionen Franken im Jahr 2021. Demgegenüber sanken die Einnahmen der Haftpflichtversicherung von 2720 Millionen Franken im Jahr 2012 auf 2553 Millionen Franken im Jahr 2021.	**SBERT:** 0.91 **LLM as Judge:** *(n=1)* ▪ Clarity: 5 ▪ Completeness: 5 ▪ Conciseness: 1 ▪ PC: 5 ▪ Neutrality: 5 ▪ Correctness: 5
6. Alt text **Short description (metadata):** Senkrecht Balkendiagramm. Titel: Weniger Verletzte, teurere Blechschäden. Untertitel: Prämieneinnahmen in Millionen Franken. Waagrechte Achse: Zeitreihe von 2012 bis 2021 (Abstand 1 Jahr). Senkrechte Achse: 0 bis 3500 Millionen Franken. Zwei Balken pro Jahr: Kaskoversicherung (Motor) (dunkelblau), Haftpflicht (Motor) (türkis). **Short description (overview):** Die Prämieneinnahmen aus der Kaskoversicherung steigen im Zeitraum von 2012 bis 2021 konstant, während die Einnahmen aus der Haftpflichtversicherung leicht sinken. **Long description:** Die Einnahmen aus der Kaskoversicherung steigen von 2933 auf 3498 Millionen Franken. Die Einnahmen aus der Haftpflichtversicherung sinken von 2720 auf 2553 Millionen Franken. Die Einnahmen aus der Kaskoversicherung übersteigen in jedem dargestellten Jahr die aus der Haftpflichtversicherung, wobei die Differenz im Zeitverlauf zunimmt.	**SBERT:** 0.9 **LLM as Judge:** *(n=1)* ▪ Clarity: 5 ▪ Completeness: 5 ▪ Conciseness: 1 ▪ PC: 5 ▪ Neutrality: 5 ▪ Correctness: 5
7. Alt text **Short description (metadata):** Senkrechtes Balkendiagramm. Titel: Weniger Verletzte, teurere Blechschäden. Untertitel: Prämieneinnahmen in Millionen Franken. Waagrechte Achse: Zeitreihe von 2012 bis 2021. Senkrechte Achse: 0 bis 3500 Millionen Franken. Zwei Balken pro Jahr: Kaskoversicherung (Motor) (dunkelblau), Haftpflicht (Motor) (türkis). **Short description (overview):** Die Prämieneinnahmen aus der Kaskoversicherung (Motor) sind von 2012 bis 2021 stetig gestiegen, während die Einnahmen aus der Haftpflichtversicherung (Motor) im selben Zeitraum gesunken sind. **Long description:** Die Einnahmen der Kaskoversicherung (Motor) steigen von 2'933 Millionen Franken im Jahr 2012 auf 3'498 Millionen Franken im Jahr 2021. Die Einnahmen der Haftpflichtversicherung (Motor) sinken von 2'720 Millionen Franken im Jahr 2012 auf 2'553 Millionen Franken im Jahr 2021. Die Einnahmen der Kaskoversicherung liegen in jedem Jahr über denen der Haftpflichtversicherung.	**SBERT:** 0.9 **LLM as Judge:** *(n=1)* ▪ Clarity: 5 ▪ Completeness: 5 ▪ Conciseness: 1 ▪ PC: 5 ▪ Neutrality: 5 ▪ Correctness: 5

8. Alt text **Short description (metadata):** Senkrechtes Balkendiagramm. Titel: Weniger Verletzte, teurere Blechschäden. Untertitel: Prämieneinnahmen in Millionen Franken. Waagrechte Achse: Zeitreihe von 2012 bis 2021 (jährlich). Senkrechte Achse: 0 bis 3500 Millionen Franken. Zwei Balken pro Jahr: Kaskoversicherung (Motor) (dunkelblau), Haftpflicht (Motor) (türkis). **Short description (overview):** Die Prämieneinnahmen der Kaskoversicherung steigen zwischen 2012 und 2021 kontinuierlich an, während die Einnahmen der Haftpflichtversicherung im gleichen Zeitraum leicht sinken. **Long description:** Die Prämieneinnahmen der Kaskoversicherung steigen von 2933 auf 3498 Millionen Franken. Die Einnahmen der Haftpflichtversicherung sinken von 2720 auf 2553 Millionen Franken. Betrugen die Einnahmen der Kaskoversicherung 2012 noch 213 Millionen Franken mehr als die Haftpflicht, erhöht sich dieser Unterschied bis 2021 auf 945 Millionen Franken.	**SBERT:** 0.89 **LLM as Judge:** *(n=1)* ▪ Clarity: 5 ▪ Completeness: 5 ▪ Conciseness: 2 ▪ PC: 5 ▪ Neutrality: 5 ▪ Correctness: 5
9. Alt text **Short description (metadata):** Senkrechtes Balkendiagramm. Titel: Weniger Verletzte, teurere Blechschäden. Untertitel: Prämieneinnahmen in Millionen Franken. Waagrechte Achse: Zeitreihe von 2012 bis 2021. Senkrechte Achse: 0 bis 3500 Millionen Franken. Zwei Balken pro Jahr: Kaskoversicherung (Motor) (dunkelblau), Haftpflicht (Motor) (türkis). **Short description (overview):** Die Prämieneinnahmen aus der Kaskoversicherung steigen im betrachteten Zeitraum kontinuierlich an, während die Einnahmen aus der Haftpflichtversicherung leicht zurückgehen. **Long description:** Die Einnahmen der Kaskoversicherung steigen von 2933 Millionen Franken im Jahr 2012 auf 3498 Millionen Franken im Jahr 2021. Die Einnahmen der Haftpflichtversicherung sinken im selben Zeitraum von 2720 Millionen Franken auf 2553 Millionen Franken. In jedem Jahr liegen die Prämieneinnahmen der Kaskoversicherung über denen der Haftpflichtversicherung.	**SBERT:** 0.88 **LLM as Judge:** *(n=1)* ▪ Clarity: 5 ▪ Completeness: 5 ▪ Conciseness: 2 ▪ PC: 5 ▪ Neutrality: 5 ▪ Correctness: 5
10. Alt text **Short description (metadata):** Senkrechtes Balkendiagramm. Titel: Weniger Verletzte, teurere Blechschäden. Untertitel: Prämieneinnahmen in Millionen Franken. Waagrechte Achse: Zeitreihe von 2012 bis 2021. Senkrechte Achse: Null bis 3500 Millionen Franken. Zwei Balken pro Jahr: Kaskoversicherung (Motor) (dunkelblau), Haftpflicht (Motor) (türkis). **Short description (overview):** Im Zeitraum von 2012 bis 2021 steigen die Prämieneinnahmen der Kaskoversicherung kontinuierlich, während die Einnahmen der Haftpflichtversicherung leicht sinken. **Long description:** Die Einnahmen der Kaskoversicherung steigen von 2933 Millionen Franken im Jahr 2012 auf 3498 Millionen Franken im Jahr 2021. Demgegenüber sinken die Einnahmen der Haftpflichtversicherung von 2720 Millionen Franken im Jahr 2012 auf 2553 Millionen Franken im Jahr 2021. Die Einnahmen der Kaskoversicherung liegen in jedem Jahr über denen der Haftpflichtversicherung.	**SBERT:** 0.86 **LLM as Judge:** *(n=1)* ▪ Clarity: 5 ▪ Completeness: 5 ▪ Conciseness: 1 ▪ PC: 5 ▪ Neutrality: 5 ▪ Correctness: 5

01ba465f792500066ff5d6bee1dc9387

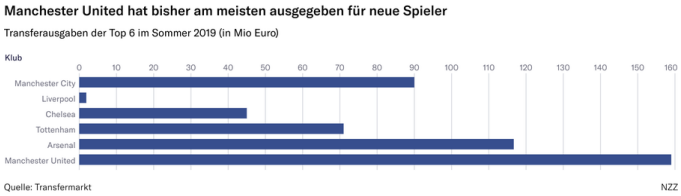

Golden standard

Short description (metadata): Waagrechtes Balkendiagramm. Titel: Manchester United hat bisher am meisten für neue Spieler ausgegeben. Untertitel: Transferausgaben der Top 6 im Sommer 2019 (in Mio Euro). Waagrechte Achse: 0 bis 160 Millionen Euro. Senkrechte Achse: Manchester City, Liverpool, Chelsea, Tottenham, Arsenal, Manchester United.

Short description (overview): Die Transferausgaben der Fussballklubs variieren zwischen knapp 2 und 160 Millionen Euro.

Long description: Manchester City: 90, Liverpool: 1.9 (tiefster Wert), Chelsea: 45, Tottenham: 71, Arsenal: rund 117, Manchester United: 159 (höchster Wert).

1. Alt text **Short description (metadata):** Waagrechtes Balkendiagramm. Titel: Manchester United hat bisher am meisten ausgegeben für neue Spieler. Untertitel: Transferausgaben der Top 6 im Sommer 2019 (in Mio Euro). Waagrechte Achse: 0 bis 160 Millionen Euro. Senkrechte Achse: Manchester City, Liverpool, Chelsea, Tottenham, Arsenal, Manchester United. **Short description (overview):** Manchester United hat mit Abstand die höchsten Transferausgaben unter den Top 6 Klubs, gefolgt von Arsenal und Tottenham. Liverpool hat die geringsten Ausgaben. **Long description:** Manchester United gibt 159 Millionen Euro aus. Arsenal folgt mit 116.7 Millionen Euro und Tottenham mit 71 Millionen Euro. Chelsea hat 45 Millionen Euro ausgegeben, Manchester City 90 Millionen Euro. Liverpool hat die geringsten Ausgaben von 1.9 Millionen Euro.	**SBERT:** 0.92 **LLM as Judge:** *(n=1)* ▪ Clarity: 4 ▪ Completeness: 5 ▪ Conciseness: 1 ▪ PC: 3 ▪ Neutrality: 5 ▪ Correctness: 2
2. Alt text **Short description (metadata):** Waagrechtes Balkendiagramm. Titel: Manchester United hat bisher am meisten ausgegeben für neue Spieler. Untertitel: Transferausgaben der Top 6 im Sommer 2019 (in Mio Euro). Waagrechte Achse: (Ausschnitt) 0 bis 160 Mio. Euro. Senkrechte Achse: Manchester City, Liverpool, Chelsea, Tottenham, Arsenal, Manchester United. **Short description (overview):** Manchester United hat mit Abstand die höchsten Transferausgaben, gefolgt von Arsenal. Liverpool hat die geringsten Ausgaben unter den Top 6. **Long description:** Manchester United gibt etwa 159 Millionen Euro aus. Arsenal folgt mit 116.7 Millionen. Manchester City liegt bei 90 Millionen, Tottenham bei 71 Millionen und Chelsea bei 45 Millionen. Liverpool hat die geringsten Ausgaben mit 1.9 Millionen Euro.	**SBERT:** 0.92 **LLM as Judge:** *(n=1)* ▪ Clarity: 5 ▪ Completeness: 5 ▪ Conciseness: 1 ▪ PC: 5 ▪ Neutrality: 5 ▪ Correctness: 5

3. Alt text **Short description (metadata):** Waagerechtes Balkendiagramm. Titel: Manchester United hat bisher am meisten ausgegeben für neue Spieler. Untertitel: Transferausgaben der Top 6 im Sommer 2019 (in Mio Euro). Waagrechte Achse: Ausgaben von 0 bis 160 Millionen Euro. Senkrechte Achse: Manchester City, Liverpool, Chelsea, Tottenham, Arsenal, Manchester United. **Short description (overview):** Manchester United hat mit Abstand die höchsten Transferausgaben aller Top 6 Clubs, gefolgt von Arsenal und Tottenham. Liverpool hat die geringsten Ausgaben. **Long description:** Manchester United hat 159 Millionen Euro ausgegeben, Arsenal 116.7 Millionen und Tottenham 71 Millionen. Manchester City hat 90 Millionen ausgegeben, Chelsea 45 Millionen und Liverpool 1.9 Millionen Euro.	**SBERT:** 0.92 **LLM as Judge:** *(n=1)* ▪ Clarity: 5 ▪ Completeness: 5 ▪ Conciseness: 1 ▪ PC: 5 ▪ Neutrality: 5 ▪ Correctness: 3
4. Alt text **Short description (metadata):** Waagerechtes Balkendiagramm. Titel: Manchester United hat bisher am meisten ausgegeben für neue Spieler. Untertitel: Transferausgaben der Top 6 im Sommer 2019 (in Mio Euro). Waagrechte Achse: Ausgaben von 0 bis 160 Millionen Euro. Senkrechte Achse: Manchester City, Liverpool, Chelsea, Tottenham, Arsenal, Manchester United. **Short description (overview):** Manchester United hat 2019 bisher am meisten für neue Spieler ausgegeben, gefolgt von Arsenal, Tottenham und Chelsea. **Long description:** Manchester United hat mit 159 Millionen Euro die höchsten Ausgaben. Darauf folgen Arsenal mit 116,7 Millionen Euro, Tottenham mit 71 Millionen Euro und Chelsea mit 45 Millionen Euro. Manchester City liegt bei 90 Millionen Euro, während Liverpool mit nur 1,9 Millionen Euro die geringsten Ausgaben unter den Top 6 verzeichnet.	**SBERT:** 0.91 **LLM as Judge:** *(n=1)* ▪ Clarity: 3 ▪ Completeness: 5 ▪ Conciseness: 1 ▪ PC: 2 ▪ Neutrality: 2 ▪ Correctness: 2
5. Alt text **Short description (metadata):** Waagerechtes Balkendiagramm. Titel: Manchester United hat bisher am meisten ausgegeben für neue Spieler. Untertitel: Transferausgaben der Top 6 im Sommer 2019 (in Mio Euro). Waagrechte Achse: Ausgaben von 0 bis 160 Mio Euro in Zehnerschritten. Senkrechte Achse: Manchester City, Liverpool, Chelsea, Tottenham, Arsenal, Manchester United. **Short description (overview):** Manchester United liegt mit Abstand an der Spitze der Ausgaben für neue Spieler unter den Top 6 Klubs des Sommers 2019. Nur vier der sechs Klubs haben signifikante Transferausgaben verzeichnet. **Long description:** Manchester United gibt 159 Millionen Euro aus, gefolgt von Arsenal mit 116,7 Millionen Euro. Manchester City liegt bei 90 Millionen Euro und Tottenham bei 71 Millionen Euro. Chelsea gibt 45 Millionen Euro aus und Liverpool 1,9 Millionen Euro.	**SBERT:** 0.91 **LLM as Judge:** *(n=1)* ▪ Clarity: 4 ▪ Completeness: 5 ▪ Conciseness: 2 ▪ PC: 4 ▪ Neutrality: 3 ▪ Correctness: 4

6. Alt text **Short description (metadata):** Waagerechtes Balkendiagramm. Titel: Manchester United hat bisher am meisten ausgegeben für neue Spieler. Untertitel: Transferausgaben der Top 6 im Sommer 2019 (in Mio Euro). Waagrechte Achse: Ausgaben von 0 bis 160 Millionen Euro. Senkrechte Achse: Manchester City, Liverpool, Chelsea, Tottenham, Arsenal, Manchester United. **Short description (overview):** Manchester United hat die mit Abstand höchsten Ausgaben getätigt, gefolgt von Arsenal und Tottenham; Liverpool liegt weit zurück. **Long description:** Manchester United hat 159 Millionen Euro ausgegeben. Arsenal folgt mit 116,7 Millionen Euro. Tottenham hat 71 Millionen Euro investiert. Chelsea gab 45 Millionen Euro aus. Manchester City liegt bei 90 Millionen Euro. Liverpool liegt mit 1,9 Millionen Euro an letzter Stelle.	**SBERT:** 0.91 **LLM as Judge:** *(n=1)* ▪ Clarity: 2 ▪ Completeness: 5 ▪ Conciseness: 2 ▪ PC: 5 ▪ Neutrality: 5 ▪ Correctness: 4
7. Alt text **Short description (metadata):** Waagerechtes Balkendiagramm. Titel: Manchester United hat bisher am meisten ausgegeben für neue Spieler. Untertitel: Transferausgaben der Top 6 im Sommer 2019 (in Mio Euro). Waagrechte Achse: Ausgaben von 0 bis 160 Millionen Euro. Senkrechte Achse: Manchester City, Liverpool, Chelsea, Tottenham, Arsenal, Manchester United. **Short description (overview):** Manchester United hat mit Abstand die höchsten Transferausgaben in dieser Gruppe, gefolgt von Arsenal. Liverpool hat die geringsten Ausgaben. **Long description:** Manchester United gibt 159 Millionen Euro aus, Arsenal 116.7 Millionen und Manchester City 90 Millionen. Tottenham gibt 71 Millionen Euro aus, Chelsea 45 Millionen und Liverpool 1.9 Millionen.	**SBERT:** 0.91 **LLM as Judge:** *(n=1)* ▪ Clarity: 5 ▪ Completeness: 5 ▪ Conciseness: 1 ▪ PC: 5 ▪ Neutrality: 5 ▪ Correctness: 5
8. Alt text **Short description (metadata):** Waagerechtes Balkendiagramm. Titel: Manchester United hat bisher am meisten ausgegeben für neue Spieler. Untertitel: Transferausgaben der Top 6 im Sommer 2019 (in Mio Euro). Waagrechte Achse: Ausgaben von 0 bis 160 Millionen Euro. Senkrechte Achse: Manchester City, Liverpool, Chelsea, Tottenham, Arsenal, Manchester United. **Short description (overview):** Manchester United hat mit Abstand die höchsten Transferausgaben in dieser Gruppe, gefolgt von Arsenal. Die Ausgaben der Klubs variieren stark, wobei Liverpool am wenigsten investierte. **Long description:** Manchester United gab 159 Millionen Euro aus, Arsenal 116,7 Millionen Euro. Tottenham lag bei 71 Millionen Euro, Chelsea bei 45 Millionen Euro, und Manchester City bei 90 Millionen Euro. Liverpool investierte lediglich 1,9 Millionen Euro.	**SBERT:** 0.91 **LLM as Judge:** *(n=1)* ▪ Clarity: 5 ▪ Completeness: 5 ▪ Conciseness: 1 ▪ PC: 5 ▪ Neutrality: 3 ▪ Correctness: 5

9. Alt text **Short description (metadata):** Waagerechtes Balkendiagramm. Titel: Manchester United hat bisher am meisten ausgegeben für neue Spieler. Untertitel: Transferausgaben der Top 6 im Sommer 2019 (in Mio Euro). Waagrechte Achse: Ausgaben von 0 bis 160 Millionen Euro. Senkrechte Achse: Manchester City, Liverpool, Chelsea, Tottenham, Arsenal, Manchester United. **Short description (overview):** Manchester United hat mit Abstand die höchsten Transferausgaben, gefolgt von Arsenal und Tottenham; Chelsea und Manchester City haben mittlere Ausgaben, während Liverpool sehr geringe Ausgaben verzeichnet. **Long description:** Manchester United hat 159 Millionen Euro ausgegeben, Arsenal 116,7 Millionen und Tottenham 71 Millionen. Die Ausgaben von Manchester City (90 Millionen) und Chelsea (45 Millionen) liegen im mittleren Bereich. Liverpool hat die niedrigsten Ausgaben mit 1,9 Millionen Euro.	**SBERT:** 0.89 **LLM as Judge:** *(n=1)* ▪ Clarity: 4 ▪ Completeness: 5 ▪ Conciseness: 1 ▪ PC: 5 ▪ Neutrality: 5 ▪ Correctness: 3
10. Alt text **Short description (metadata):** Waagerechtes Balkendiagramm. Titel: Manchester United hat bisher am meisten ausgegeben für neue Spieler. Untertitel: Transferausgaben der Top 6 im Sommer 2019 (in Mio Euro). Waagrechte Achse: Ausgaben in Millionen Euro von 0 bis 160. Senkrechte Achse: Manchester City, Liverpool, Chelsea, Tottenham, Arsenal, Manchester United. **Short description (overview):** Manchester United liegt mit Ausgaben von 159 Millionen Euro an der Spitze, gefolgt von Arsenal mit 116,7 Millionen Euro. Liverpool investiert mit 1,9 Millionen Euro am wenigsten. **Long description:** Manchester United gibt 159 Millionen Euro für neue Spieler aus. Arsenal folgt mit 116,7 Millionen Euro. Tottenham gibt 71 Millionen Euro aus und Manchester City 90 Millionen Euro. Chelsea investiert 45 Millionen Euro, während Liverpool die geringsten Ausgaben von 1,9 Millionen Euro verbucht.	**SBERT:** 0.87 **LLM as Judge:** *(n=1)* ▪ Clarity: 4 ▪ Completeness: 5 ▪ Conciseness: 1 ▪ PC: 5 ▪ Neutrality: 5 ▪ Correctness: 5

0099651643916eeda249aae35ad10f57

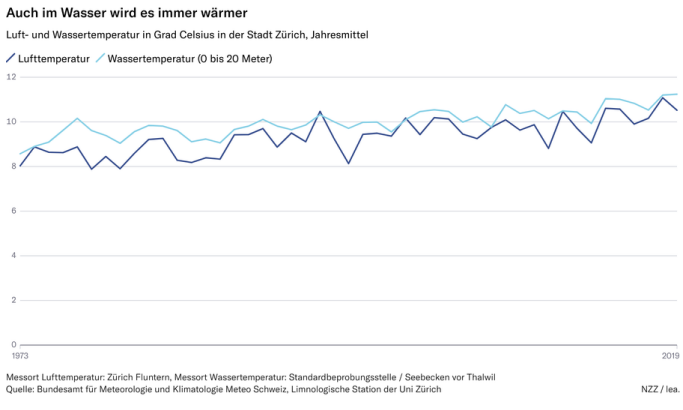

Golden standard
Short description (metadata): Liniendiagramm. Titel: Auch im Wasser wird es immer wärmer. Untertitel: Luft- und Wassertemperatur in Grad Celsius in der Stadt Zürich, Jahresmittel. Waagrechte Achse: Zeitraum 1973 bis 2019. Senkrechte Achse: 0 bis 12 Grad Celsius. Daten: Jährliche Werte. Zwei Linien: Lufttemperatur (dunkelblau), Wassertemperatur (bis 20 Meter, hellblau). Messort Lufttemperatur: Zürich Fluntern, Messort Wassertemperatur: Standardbeprobungsstelle / Seebecken vor Thalwil.
Short description (overview): Beide Temperaturreihen steigen im Verlauf mit Schwankungen von maximal 2 Grad Celsius. Die Wassertemperatur verläuft meistens leicht über der Lufttemperatur und schwankt weniger stark.
Long description: 1973 liegen beide Temperaturen knapp unter 9 Grad Celsius (Luft rund 8 Grad Celsius, Wasser etwa 8.6 Grad Celsius). Bis 2019 steigen sie auf rund 10.5 Grad Celsius (Luft) und 11.2 Grad Celsius (Wasser). Die Wassertemperatur ist durchschnittlich 0.65 Grad Celsius höher als die Lufttemperatur.

1. Alt text **Short description (metadata):** Liniendiagramm. Titel: Auch im Wasser wird es immer wärmer. Untertitel: Luft- und Wassertemperatur in Grad Celsius in der Stadt Zürich, Jahresmittel. Waagerechte Achse: Zeitraum 1973 bis 2019. Senkrechte Achse: Ausschnitt 0 bis 12 Grad Celsius. Daten: Jährliche Werte. Zwei Linien: Lufttemperatur (dunkelblau), Wassertemperatur (0 bis 20 Meter) (hellblau). **Short description (overview):** Während die Wassertemperatur meist höher liegt, zeigt sie generell weniger Schwankungen als die Lufttemperatur. Im Zeitverlauf steigen beide Temperaturen, wobei die Wassertemperatur tendenziell leicht stärker zunimmt. Phasenweise sinken die Lufttemperaturen unter die Wassertemperaturen ab. **Long description:** Beide Temperaturen zeigen über den Gesamtzeitraum einen generellen Aufwärtstrend. Die Wassertemperatur startet bei rund 8,6 Grad und steigt tendenziell auf etwa 11,2 Grad. Die Lufttemperatur liegt zu Beginn bei rund 8 Grad und steigt bis 2019 auf etwa 10,5 Grad. Die Lufttemperatur schwankt stärker und kreuzt mehrmals die Wassertemperatur, liegt aber meist darunter. In jüngster Zeit bewegt sich die Wassertemperatur auf einem deutlich höheren Niveau.	**SBERT:** 0.92 **LLM as Judge:** *(n=1)* ▪ Clarity: 5 ▪ Completeness: 5 ▪ Conciseness: 1 ▪ PC: 5 ▪ Neutrality: 5 ▪ Correctness: 5
2. Alt text **Short description (metadata):** Liniendiagramm. Titel: Auch im Wasser wird es immer wärmer. Untertitel: Luft- und Wassertemperatur in Grad Celsius in der Stadt Zürich, Jahresmittel. Waagerechte Achse: Zeitraum 1973 bis 2019. Senkrechte Achse: Ausschnitt 0 bis 12 Grad Celsius. Daten: Jährliche Werte. Zwei Linien: Lufttemperatur (Dunkelblau), Wassertemperatur (0 bis 20 Meter) (Hellblau). **Short description (overview):** Während des gesamten Zeitraums zeigt die Wassertemperatur fast durchgängig höhere Werte als die Lufttemperatur. Beide Temperaturen weisen einen steigenden Trend auf. Die Wassertemperatur verläuft ruhiger, während die Lufttemperatur stärkere jährliche Schwankungen zeigt. **Long description:** Die Lufttemperatur beginnt 1973 bei etwa acht Grad Celsius und zeigt starke jährliche Schwankungen, steigt aber bis 2019 auf über zehn Grad Celsius. Die Wassertemperatur beginnt etwas höher bei etwa achteinhalb Grad Celsius, verläuft mit geringeren Schwankungen und steigt bis 2019 auf über elf Grad Celsius. Die Linien kreuzen sich mehrmals, bleiben jedoch ab dem Jahr 2000 fast durchgehend in ihren Trendbereichen.	**SBERT:** 0.91 **LLM as Judge:** *(n=1)* ▪ Clarity: 5 ▪ Completeness: 4 ▪ Conciseness: 2 ▪ PC: 4 ▪ Neutrality: 5 ▪ Correctness: 2

3. Alt text **Short description (metadata):** Liniendiagramm. Titel: Auch im Wasser wird es immer wärmer. Untertitel: Luft- und Wassertemperatur in Grad Celsius in der Stadt Zürich, Jahresmittel. Waagerechte Achse: Zeitraum 1973 bis 2019. Senkrechte Achse: Ausschnitt 0 bis 12 Grad Celsius. Daten: Jährliche Werte. Zwei Linien: Lufttemperatur (Dunkelblau), Wassertemperatur (Null bis 20 Meter) (Hellblau). **Short description (overview):** Während des gesamten Zeitraums schwanken sowohl die Luft- als auch die Wassertemperatur stark, folgen aber einem stetigen Aufwärtstrend. Bis etwa 1993 liegt die Wassertemperatur fast durchgängig über der Lufttemperatur; danach wechseln sich die Rangfolgen ab, wobei die Wassertemperatur in der zweiten Hälfte oft über der Lufttemperatur liegt. **Long description:** Die Lufttemperatur beginnt 1973 bei rund acht Grad Celsius und steigt bis 2019 auf etwa Zehn Komma Fünf Grad Celsius. Die Wassertemperatur startet bei etwa Achteinhalb Grad Celsius und steigt bis 2019 auf über Elf Grad Celsius. Beide Linien zeigen deutliche jährliche Schwankungen, wobei die Lufttemperatur stärker schwankt als die Wassertemperatur. Ab 2014 liegen beide Temperaturen auf einem erhöhten Niveau mit ähnlichen Schwankungen.	**SBERT:** 0.91 **LLM as Judge:** *(n=1)* ▪ Clarity: 5 ▪ Completeness: 5 ▪ Conciseness: 1 ▪ PC: 5 ▪ Neutrality: 5 ▪ Correctness: 4
4. Alt text **Short description (metadata):** Diagrammtyp: Liniendiagramm. Titel: Auch im Wasser wird es immer wärmer. Untertitel: Luft- und Wassertemperatur in Grad Celsius in der Stadt Zürich, Jahresmittel. Waagerechte Achse: Zeitraum 1973 bis 2019. Senkrechte Achse: Ausschnitt 0 bis 12 Grad Celsius. Daten: Jährliche Werte. Zwei Linien: Lufttemperatur (Dunkelblau), Wassertemperatur null bis 20 Meter (Hellblau). **Short description (overview):** Die Wassertemperatur liegt im gesamten Zeitraum tendenziell über der Lufttemperatur und zeigt eine weniger schwankende Entwicklung. Beide Temperaturen weisen über die Jahre einen allgemeinen steigenden Trend auf, wobei die Lufttemperatur stärker schwankt und in der zweiten Hälfte des Zeitraums deutlich zulegt. **Long description:** Von 1973 bis etwa 1993 liegt die Wassertemperatur konstant höher als die Lufttemperatur. Die Lufttemperatur steigt von etwa acht Grad auf über neun Grad, während die Wassertemperatur von etwa achteinhalb auf über neuneinhalb Grad steigt. Nach 1993 kreuzen sich die Linien mehrmals. Die Lufttemperatur zeigt bis 2019 einen stärkeren Anstieg, der zu Werten über zehn Grad führt. Die Wassertemperatur steigt bis 2019 auf über elf Grad.	**SBERT:** 0.91 **LLM as Judge:** *(n=1)* ▪ Clarity: 5 ▪ Completeness: 5 ▪ Conciseness: 1 ▪ PC: 4 ▪ Neutrality: 5 ▪ Correctness: 2

5. Alt text **Short description (metadata):** Liniendiagramm. Titel: Auch im Wasser wird es immer wärmer. Untertitel: Luft- und Wassertemperatur in Grad Celsius in der Stadt Zürich, Jahresmittel. Waagerechte Achse: Zeitraum 1973 bis 2019. Senkrechte Achse: Ausschnitt 0 bis 12 Grad Celsius. Daten: Jährliche Werte. Zwei Linien: Lufttemperatur (Dunkelblau), Wassertemperatur (0 bis 20 Meter) (Hellblau). **Short description (overview):** Über den gesamten Zeitraum von 1973 bis 2019 zeigen beide gemessenen Temperaturen eine deutliche Tendenz zum Anstieg, wobei die Wassertemperatur fast durchgängig höher liegt als die Lufttemperatur. Die Schwankungen der Lufttemperatur sind ausgeprägter als die der Wassertemperatur. **Long description:** Die Lufttemperatur beginnt bei rund 8 Grad und steigt bis zum Ende des Zeitraums auf etwa 10,5 Grad. Die Wassertemperatur startet bei etwa 8,5 Grad und steigt auf gut 11 Grad. Bis etwa 1994 bleibt die Wassertemperatur stabil über der Lufttemperatur. Ab 1994 kreuzen sich die Linien mehrmals, wobei die Lufttemperatur viermal kurzzeitig über der Wassertemperatur liegt. Ab 2014 liegen beide Temperaturen auf einem erhöhten Niveau von über 10 Grad.	**SBERT:** 0.91 **LLM as Judge:** *(n=1)* ▪ Clarity: 4 ▪ Completeness: 4 ▪ Conciseness: 1 ▪ PC: 4 ▪ Neutrality: 5 ▪ Correctness: 2
6. Alt text **Short description (metadata):** Liniendiagramm. Titel: Auch im Wasser wird es immer wärmer. Untertitel: Luft- und Wassertemperatur in Grad Celsius in der Stadt Zürich, Jahresmittel. Waagerechte Achse: Zeitraum 1973 bis 2019. Senkrechte Achse: Ausschnitt 0 bis 12 Grad Celsius. Daten: Jährliche Werte. Zwei Linien: Lufttemperatur (Dunkelblau), Wassertemperatur (0 bis 20 Meter) (Hellblau). **Short description (overview):** Beide Temperaturen steigen über den gesamten Zeitraum signifikant, wobei die Wassertemperatur fast durchgängig höher liegt als die Lufttemperatur. Die Schwankungen der Lufttemperatur sind ausgeprägter als die der Wassertemperatur, und die Differenz zwischen den beiden Temperaturen verringert sich gegen Ende des Zeitraums. **Long description:** Die Lufttemperatur beginnt bei rund 8,0 Grad und steigt mit starken jährlichen Schwankungen auf rund 10,5 Grad. Die Wassertemperatur startet bei rund 8,6 Grad und verläuft stabiler, steigt aber ebenfalls kontinuierlich auf über 11 Grad an und liegt ab 2014 im Bereich des höchsten Niveaus. In den ersten 20 Jahren liegt die Wassertemperatur meist deutlich über der Lufttemperatur, während sich die beiden Werte gegen Ende des Zeitraums annähern oder teilweise kreuzen.	**SBERT:** 0.9 **LLM as Judge:** *(n=1)* ▪ Clarity: 5 ▪ Completeness: 4 ▪ Conciseness: 1 ▪ PC: 2 ▪ Neutrality: 3 ▪ Correctness: 3

7. Alt text **Short description (metadata):** Liniendiagramm. Titel: Auch im Wasser wird es immer wärmer. Untertitel: Luft- und Wassertemperatur in Grad Celsius in der Stadt Zürich, Jahresmittel. Waagerechte Achse: Zeitraum 1973 bis 2019. Senkrechte Achse: Ausschnitt 0 bis 12 Grad Celsius. Daten: Jährliche Werte. Zwei Linien: Lufttemperatur (Dunkelblau), Wassertemperatur (0 bis 20 Meter) (Hellblau). **Short description (overview):** Beide Temperaturen schwanken stark über den Beobachtungszeitraum. Die Wassertemperatur liegt tendenziell höher als die Lufttemperatur. Beide Linien zeigen insgesamt einen leicht steigenden Trend. Im letzten Jahrzehnt steigen beide Temperaturen auf neue Höchstwerte an. **Long description:** 1973 beginnen beide Linien bei Werten unter neun Grad Celsius. Die Wassertemperatur liegt bis 1994 durchgängig über der Lufttemperatur, mit einer maximalen Differenz um 1977. Zwischen 1994 und 2000 kreuzen sich die Linien mehrfach, beide bei Werten zwischen neun und elf Grad Celsius. Ab 2001 steigt die Wassertemperatur auf ein höheres Niveau, während die Lufttemperatur höhere Schwankungen zeigt. Im Jahr 2018 verzeichnen beide Linien ihre höchsten Werte (über elf Grad Celsius). Die Wassertemperatur endet 2019 leicht über dem Anfangswert der Lufttemperatur, welche leicht darunter liegt.	**SBERT:** 0.88 **LLM as Judge:** *(n=1)* ▪ Clarity: 4 ▪ Completeness: 5 ▪ Conciseness: 1 ▪ PC: 5 ▪ Neutrality: 5 ▪ Correctness: 2
8. Alt text **Short description (metadata):** Liniendiagramm. Titel: Auch im Wasser wird es immer wärmer. Untertitel: Luft- und Wassertemperatur in Grad Celsius in der Stadt Zürich, Jahresmittel. Waagerechte Achse: Zeitraum 1973 bis 2019. Senkrechte Achse: Ausschnitt 0 bis 12 Grad Celsius. Daten: Jährliche Werte. Zwei Linien: Lufttemperatur (Dunkelblau), Wassertemperatur (Null bis 20 Meter) (Hellblau). **Short description (overview):** Während des gesamten Zeitraums zeigt die Wassertemperatur tendenziell höhere und stabilere Jahresmittelwerte als die Lufttemperatur. Beide Temperaturen zeigen einen allgemeinen Anstieg, wobei die Schwankungen der Lufttemperatur ausgeprägter sind. Gegen Ende des Zeitraums nähern sich die Werte an. **Long description:** Die Lufttemperatur (dunkelblaue Linie) beginnt bei etwa 8 Grad Celsius und steigt bis 2019 auf etwa 10,5 Grad Celsius, mit deutlichen jährlichen Schwankungen. Die Wassertemperatur (hellblaue Linie) beginnt bei etwa 8,5 Grad Celsius und steigt bis 2019 auf über 11 Grad Celsius. Während die Wassertemperatur in der ersten Hälfte des Zeitraums meist höher liegt, kreuzen sich die Linien mehrfach ab den frühen 1990er-Jahren. Bis 2019 erreichen beide Linien höhere Niveaus als zu Beginn der Messreihe.	**SBERT:** 0.86 **LLM as Judge:** *(n=1)* ▪ Clarity: 5 ▪ Completeness: 5 ▪ Conciseness: 1 ▪ PC: 5 ▪ Neutrality: 5 ▪ Correctness: 4

9. Alt text **Short description (metadata):** Liniendiagramm. Titel: Auch im Wasser wird es immer wärmer. Untertitel: Luft- und Wassertemperatur in Grad Celsius in der Stadt Zürich, Jahresmittel. Waagerechte Achse: Zeitraum 1973 bis 2019. Senkrechte Achse: Ausschnitt 0 bis 12 Grad Celsius. Daten: Jährliche Werte. Zwei Linien: Lufttemperatur (Dunkelblau), Wassertemperatur (0 bis 20 Meter) (Hellblau). **Short description (overview):** Während des gesamten Zeitraums zeigen beide Temperaturen einen generell steigenden Trend. Die Wassertemperatur beginnt meist höher und verläuft im Durchschnitt wärmer als die Lufttemperatur, was sich im Trendverlauf nur in wenigen aufeinanderfolgenden Jahren überkreuzt. **Long description:** Die Lufttemperatur beginnt bei etwa acht Grad Celsius und steigt bis 2019 auf etwa zehn Grad Celsius, mit deutlichen jährlichen Schwankungen. Die Wassertemperatur beginnt bei etwa achteinhalb Grad Celsius und steigt bis 2019 auf über elf Grad Celsius. Nach 1993 kreuzen sich die Linien mehrfach, wobei die Wassertemperatur tendenziell leicht stärker ansteigt und am Ende den höchsten Wert erreicht hat.	**SBERT:** 0.86 **LLM as Judge:** *(n=1)* ▪ Clarity: 5 ▪ Completeness: 4 ▪ Conciseness: 1 ▪ PC: — ▪ Neutrality: 3 ▪ Correctness: 5
10. Alt text **Short description (metadata):** Liniendiagramm. Titel: Auch im Wasser wird es immer wärmer. Untertitel: Luft- und Wassertemperatur in Grad Celsius in der Stadt Zürich, Jahresmittel. Waagerechte Achse: Zeitraum 1973 bis 2019. Senkrechte Achse: Ausschnitt 0 bis 12 Grad Celsius. Daten: Jährliche Werte. Zwei Linien: Lufttemperatur (Dunkelblau), Wassertemperatur (0 bis 20 Meter) (Hellblau). **Short description (overview):** Während des gesamten Zeitraums schwanken die jährlichen Durchschnittstemperaturen beider Linien. Die Wassertemperatur liegt tendenziell höher als die Lufttemperatur, zeigt jedoch eine geringere Volatilität. Beide Linien steigen im gesamten Zeitraum an und weisen in den späteren Jahren höhere Werte auf. **Long description:** Die Lufttemperatur beginnt 1973 bei etwa acht Grad Celsius und schwankt bis 2000 zwischen rund sieben Komma neun Grad Celsius und neun Komma sieben Grad Celsius. Ab 2000 steigt die Lufttemperatur auf ein höheres Niveau und bleibt meist über neun Komma zwei Grad Celsius, mit einem Höchstwert von elf Komma null acht Grad Celsius im Jahr 2018. Die Wassertemperatur beginnt bei etwa acht Komma sechs Grad Celsius und liegt durchgehend höher als die Lufttemperatur, mit Ausnahmen zwischen 1994 und 2000. Sie liegt größtenteils zwischen neun Grad Celsius und zehn Komma fünf Grad Celsius, überschreitet ab 2014 elf Grad Celsius und erreicht 2019 ihren Höchstwert von elf Komma vierundzwanzig Grad Celsius.	**SBERT:** 0.85 **LLM as Judge:** *(n=1)* ▪ Clarity: 4 ▪ Completeness: 5 ▪ Conciseness: 1 ▪ PC: 5 ▪ Neutrality: 5 ▪ Correctness: 3

014e6bf3927ddaf505c8053e37226a1e

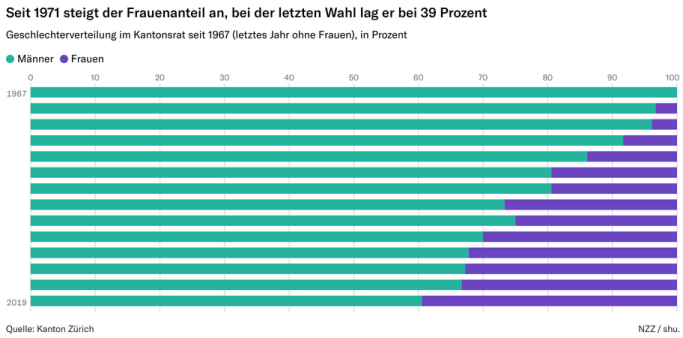

Golden standard

Short description (metadata): Waagrechtes Balkendiagramm. Titel: Seit 1971 steigt der Frauenanteil an, bei der letzten Wahl lag er bei 39 Prozent. Untertitel: Geschlechterverteilung im Kantonsrat seit 1967 (letztes Jahr ohne Frauen), in Prozent. Waagrechte Achse: 0 bis 100 Prozent. Senkrechte Achse: 1967 bis 2019 in Vierjahreschritten. Pro Jahr ein Balken, unterteilt in zwei Anteile: Männer (grün), Frauen (violett).

Short description (overview): Seit 1971 steigt der Frauenanteil im Zürcher Kantonsrat stetig von 0 auf knapp 40 Prozent an.

Long description: 1967 besteht der Zürcher Kantonsrat ausschliesslich aus Männern. Bis 1980 liegt der Frauenanteil bei knapp 10 Prozent, bis 1999 steigt er auf rund 25 Prozent. Ab 2007 beträgt er etwa ein Drittel und steigt bis 2019 knapp 40 Prozent.

1. Alt text **Short description (metadata):** Waagrecht gestapeltes Balkendiagramm. Titel: Seit 1971 steigt der Frauenanteil an, bei der letzten Wahl lag er bei 39 Prozent. Untertitel: Geschlechterverteilung im Kantonsrat seit 1967 (letztes Jahr ohne Frauen), in Prozent. Waagrechte Achse: 0 bis 100 Prozent. Senkrechte Achse: 1967 bis 2019 (mit Lücken). Segmente pro Balken: Männer (Hellgrün), Frauen (Violett). **Short description (overview):** Der Anteil der Frauen steigt im Zeitverlauf kontinuierlich an, während der Anteil der Männer sinkt. **Long description:** Der Frauenanteil im Kantonsrat stieg von Null Prozent im Jahr 1967 auf fast 40 Prozent im Jahr 2019. Der größte Anstieg erfolgte zwischen 1983 mit 13,89 Prozent und 1987 mit 19,44 Prozent. Der Männeranteil sank von 100 Prozent im Jahr 1967 auf rund 60,56 Prozent im Jahr 2019.	**SBERT:** 0.91 **LLM as Judge:** *(n=1)* ▪ Clarity: 4 ▪ Completeness: 4 ▪ Conciseness: 2 ▪ PC: 5 ▪ Neutrality: 5 ▪ Correctness: 2
2. Alt text **Short description (metadata):** Waagrecht gestapeltes Balkendiagramm. Titel: Seit 1971 steigt der Frauenanteil an, bei der letzten Wahl lag er bei 39 Prozent. Untertitel: Geschlechterverteilung im Kantonsrat seit 1967 (letztes Jahr ohne Frauen), in Prozent. Waagrechte Achse: Null bis einhundert Prozent. Senkrechte Achse: Jahre (1967, 1971, 1975, 1979, 1983, 1987, 1991, 1995, 1999, 2003, 2007, 2011, 2015, 2019). Segmente pro Balken: Männer (Türkis), Frauen (Violett). **Short description (overview):** Der Frauenanteil im Kantonsrat steigt kontinuierlich von einem Prozent-Anteil von null im Jahr 1967 auf fast vierzig Prozent im Jahr 2019. **Long description:** Der Anteil der Frauen steigt von null Prozent im Jahr 1967 auf rund drei Prozent im Jahr 1971 und erreicht 1987 knapp zwanzig Prozent. Im Jahr 2003 überschreitet er dreissig Prozent und erreicht 2019 seinen Höchststand bei rund neununddreissig Prozent. Die Männer stellen aber auch zu diesem Zeitpunkt mit rund einundsechzig Prozent noch die Mehrheit.	**SBERT:** 0.9 **LLM as Judge:** *(n=1)* ▪ Clarity: 5 ▪ Completeness: 4 ▪ Conciseness: 1 ▪ PC: 5 ▪ Neutrality: 5 ▪ Correctness: 4

3. Alt text **Short description (metadata):** Waagrecht gestapeltes Balkendiagramm. Titel: Seit 1971 steigt der Frauenanteil an, bei der letzten Wahl lag er bei 39 Prozent. Untertitel: Geschlechterverteilung im Kantonsrat seit 1967 (letztes Jahr ohne Frauen), in Prozent. Waagrechte Achse: 0 bis 100 Prozent. Senkrechte Achse: 1967, 1971, 1975, 1979, 1983, 1987, 1991, 1995, 1999, 2003, 2007, 2011, 2015, 2019. Segmente pro Balken: Männer (Türkis), Frauen (Violett). **Short description (overview):** Der Anteil der Frauen im Kantonsrat steigt von null Prozent im Jahr 1967 auf fast 40 Prozent im Jahr 2019 an, während der Männeranteil sinkt. **Long description:** Der Frauenanteil stieg kontinuierlich von null Prozent im Jahr 1967 auf 39,44 Prozent im Jahr 2019 an. Im Gegensatz dazu sank der Männeranteil von 100 Prozent im Jahr 1967 auf rund 60,56 Prozent im Jahr 2019. Die stärksten Zuwächse verzeichnete der Frauenanteil zwischen 1979 (8,33 Prozent) und 1983 (13,89 Prozent) sowie zwischen 2015 (33,33 Prozent) und 2019 (39,44 Prozent).	**SBERT:** 0.9 **LLM as Judge:** *(n=1)* ▪ Clarity: 5 ▪ Completeness: 5 ▪ Conciseness: 1 ▪ PC: 5 ▪ Neutrality: 5 ▪ Correctness: 3
4. Alt text **Short description (metadata):** Waagrecht gestapeltes Balkendiagramm. Titel: Seit 1971 steigt der Frauenanteil an, bei der letzten Wahl lag er bei 39 Prozent. Untertitel: Geschlechterverteilung im Kantonsrat seit 1967 (letztes Jahr ohne Frauen), in Prozent. Waagrechte Achse: 0 bis 100 Prozent. Senkrechte Achse: Jahre von 1967 bis 2019. Segmente pro Balken: Männer (Türkis), Frauen (Violett). **Short description (overview):** Der Frauenanteil im Kantonsrat ist seit 1971 kontinuierlich gestiegen, während der Männeranteil entsprechend gesunken ist. **Long description:** Im Jahr 1967 lag der Frauenanteil bei null Prozent, Männer bei 100 Prozent. Bis 1987 stieg der Frauenanteil auf etwa 19 Prozent. Nach einem leichten Rückgang stieg er weiter auf rund 33 Prozent im Jahr 2015. 2019 erreichten Frauen einen Anteil von knapp 40 Prozent, während der Männeranteil auf etwa 60 Prozent sank.	**SBERT:** 0.9 **LLM as Judge:** *(n=1)* ▪ Clarity: 4 ▪ Completeness: 4 ▪ Conciseness: 2 ▪ PC: 5 ▪ Neutrality: 5 ▪ Correctness: 3
5. Alt text **Short description (metadata):** Waagrecht gestapeltes Balkendiagramm. Titel: Seit 1971 steigt der Frauenanteil an, bei der letzten Wahl lag er bei 39 Prozent. Untertitel: Geschlechterverteilung im Kantonsrat seit 1967 (letztes Jahr ohne Frauen), in Prozent. Waagrechte Achse: 0 bis 100 Prozent. Senkrechte Achse: 1967, 1971, 1975, 1979, 1983, 1987, 1991, 1995, 1999, 2003, 2007, 2011, 2015, 2019. Segmente pro Balken: Männer (Türkis), Frauen (Violett). **Short description (overview):** Der Frauenanteil im Kantonsrat steigt seit 1971 kontinuierlich an, während der Männeranteil entsprechend sinkt. **Long description:** Der Frauenanteil erhöht sich von null Prozent im Jahr 1967 auf 39,44 Prozent im Jahr 2019. Am stärksten steigt der Anteil zwischen 1975 mit 3,89 Prozent auf 1995 mit 26,67 Prozent. Der Männeranteil sinkt im gleichen Zeitraum von 100 Prozent auf 60,56 Prozent.	**SBERT:** 0.9 **LLM as Judge:** *(n=1)* ▪ Clarity: 4 ▪ Completeness: 4 ▪ Conciseness: 2 ▪ PC: 5 ▪ Neutrality: 5 ▪ Correctness: 2

6. Alt text **Short description (metadata):** Waagrecht gestapeltes Balkendiagramm. Titel: Seit 1971 steigt der Frauenanteil an, bei der letzten Wahl lag er bei 39 Prozent. Untertitel: Geschlechterverteilung im Kantonsrat seit 1967 (letztes Jahr ohne Frauen), in Prozent. Waagrechte Achse: 0 bis 100 Prozent. Senkrechte Achse: Jahre von 1967 bis 2019. Segmente pro Balken: Männer (Hellgrün), Frauen (Violett). **Short description (overview):** Während der Frauenanteil 1967 bei null Prozent lag, stieg er bis 2019 kontinuierlich auf 39,44 Prozent an, was der aktuellen Wahl entspricht. **Long description:** Der Männeranteil sank von 100 Prozent im Jahr 1967 auf 60,56 Prozent im Jahr 2019. Der Frauenanteil stieg im selben Zeitraum stetig von null Prozent auf 39,44 Prozent. Ein deutlicher Anstieg auf über 25 Prozent ist ab 1995 zu beobachten, als Frauen 26,67 Prozent der Sitze innehatten.	**SBERT:** 0.89 **LLM as Judge:** *(n=1)* ▪ Clarity: 5 ▪ Completeness: 4 ▪ Conciseness: 2 ▪ PC: 5 ▪ Neutrality: 5 ▪ Correctness: 3
7. Alt text **Short description (metadata):** Waagrecht gestapeltes Balkendiagramm. Titel: Seit 1971 steigt der Frauenanteil an, bei der letzten Wahl lag er bei 39 Prozent. Untertitel: Geschlechterverteilung im Kantonsrat seit 1967 (letztes Jahr ohne Frauen), in Prozent. Waagrechte Achse: Null bis einhundert Prozent. Senkrechte Achse: Jahre von 1967 bis 2019. Segmente pro Balken: Männer (Hellgrün), Frauen (Violett). **Short description (overview):** Der Frauenanteil im Kantonsrat ist von 1971 bis 2019 stetig gestiegen, während der Männeranteil entsprechend gesunken ist. **Long description:** Der Frauenanteil stieg von null Prozent im Jahr 1967 auf 39,44 Prozent im Jahr 2019. Im Gegensatz dazu sank der Männeranteil im selben Zeitraum von einhundert Prozent auf 60,56 Prozent. Ab dem Jahr 1995 überstieg der Frauenanteil die Marke von 25 Prozent.	**SBERT:** 0.89 **LLM as Judge:** *(n=1)* ▪ Clarity: 5 ▪ Completeness: 4 ▪ Conciseness: 2 ▪ PC: 5 ▪ Neutrality: 5 ▪ Correctness: 3
8. Alt text **Short description (metadata):** Waagrecht gestapeltes Balkendiagramm. Titel: Seit 1971 steigt der Frauenanteil an, bei der letzten Wahl lag er bei 39 Prozent. Untertitel: Geschlechterverteilung im Kantonsrat seit 1967 (letztes Jahr ohne Frauen), in Prozent. Waagrechte Achse: 0 bis 100 Prozent. Senkrechte Achse: Jahre von 1967 bis 2019. Segmente pro Balken: Männer (Türkis), Frauen (Violett). **Short description (overview):** Der Anteil der Frauen im Kantonsrat steigt seit 1971 kontinuierlich an, während der Anteil der Männer sinkt. **Long description:** Im Jahr 1967 lag der Frauenanteil bei null Prozent, während er bis 2019 auf rund neununddreissig Prozent gestiegen ist. Der Männeranteil sank im gleichen Zeitraum von einhundert Prozent auf rund einundsechzig Prozent. Der stärkste Anstieg des Frauenanteils fand zwischen 1983 (rund vierzehn Prozent) und 1987 (rund neunzehn Prozent) statt.	**SBERT:** 0.89 **LLM as Judge:** *(n=1)* ▪ Clarity: 4 ▪ Completeness: 4 ▪ Conciseness: 2 ▪ PC: 5 ▪ Neutrality: 5 ▪ Correctness: 3

9. Alt text **Short description (metadata):** Waagrecht gestapeltes Balkendiagramm. Titel: Seit 1971 steigt der Frauenanteil an, bei der letzten Wahl lag er bei 39 Prozent. Untertitel: Geschlechterverteilung im Kantonsrat seit 1967 (letztes Jahr ohne Frauen), in Prozent. Waagrechte Achse: 0 bis 100 Prozent. Senkrechte Achse: Jahre von 1967 bis 2019. Segmente pro Balken: Männer (Türkis), Frauen (Violett). **Short description (overview):** Der Frauenanteil im Kantonsrat steigt kontinuierlich von null Prozent im Jahr 1967 auf 39 Prozent im Jahr 2019. **Long description:** Während 1967 der Männeranteil bei 100 Prozent lag, sank dieser bis 2019 auf etwa 61 Prozent. Gleichzeitig stieg der Frauenanteil von null Prozent im Jahr 1967 auf fast 33 Prozent im Jahr 2007. Bis 2019 stieg er weiter auf etwa 39 Prozent.	**SBERT:** 0.88 **LLM as Judge:** *(n=1)* ▪ Clarity: 4 ▪ Completeness: 3 ▪ Conciseness: 2 ▪ PC: 5 ▪ Neutrality: 5 ▪ Correctness: 5
10. Alt text **Short description (metadata):** Waagrecht gestapeltes Balkendiagramm. Titel: Seit 1971 steigt der Frauenanteil an, bei der letzten Wahl lag er bei 39 Prozent. Untertitel: Geschlechterverteilung im Kantonsrat seit 1967 (letztes Jahr ohne Frauen), in Prozent. Waagrechte Achse: Null bis einhundert Prozent. Senkrechte Achse: Jahre von 1967 bis 2019. Segmente pro Balken: Männer (Türkis), Frauen (Violett). **Short description (overview):** Der Anteil der Frauen im Kantonsrat steigt kontinuierlich von null Prozent im Jahr 1967 auf fast vierzig Prozent im Jahr 2019. **Long description:** Der Frauenanteil, der 1967 bei null Prozent lag, steigt bis 2019 auf neununddreißig Komma vierundvierzig Prozent an. Erhöhungen sind besonders zwischen 1975 und 1987, sowie zwischen 1991 und 1995 und nach 1999 zu verzeichnen.	**SBERT:** 0.81 **LLM as Judge:** *(n=1)* ▪ Clarity: 3 ▪ Completeness: 3 ▪ Conciseness: 1 ▪ PC: 5 ▪ Neutrality: 5 ▪ Correctness: 4

008af45f10ff96b79bbc850c1ee5766d

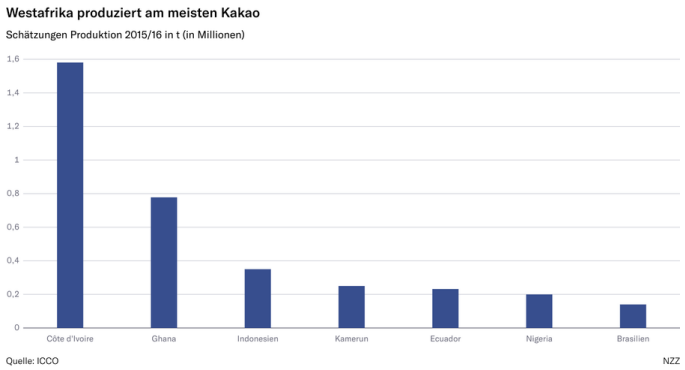

Golden standard

Short description (metadata): Senkrechtes Balkendiagramm. Titel: Westafrika produziert am meisten Kakao. Untertitel: Schätzungen Produktion 2015/16 in t (in Millionen). Waagrechte Achse: Côte d'Ivoire, Ghana, Indonesien, Kamerun, Ecuador, Nigeria und Brasilien. Senkrechte Achse: 0 bis 1.6 Millionen Tonnen Kakao.

Short description (overview): Côte d'Ivoire produziert mindestens doppelt so viel Kakao wie alle anderen Länder einzeln.

Long description: Côte d'Ivoire produziert knapp 1.6 Millionen Tonnen Kakao, Ghana knapp 0.8 und Indonesien 0.35. Kamerun, Ecuador, Nigeria und Brasilien produzieren je zwischen 0.15 und 0.25 Millionen Tonnen Kakao.

1. Alt text **Short description (metadata):** Senkrechtes Balkendiagramm. Titel: Westafrika produziert am meisten Kakao. Untertitel: Schätzungen Produktion 2015/16 in t (in Millionen). Waagrechte Achse: Côte d'Ivoire, Ghana, Indonesien, Kamerun, Ecuador, Nigeria, Brasilien. Senkrechte Achse: null bis 1,6 Millionen t. **Short description (overview):** Côte d'Ivoire produziert weitaus am meisten Kakao, gefolgt von Ghana. Alle anderen Länder liegen deutlich unter einer Million Tonnen. **Long description:** Côte d'Ivoire produziert 1,581 Millionen Tonnen Kakao, Ghana 0,778 Millionen Tonnen. Indonesien folgt mit 0,35 Millionen Tonnen. Kamerun, Ecuador und Nigeria produzieren zwischen 0,2 und 0,25 Millionen Tonnen, während Brasilien mit 0,14 Millionen Tonnen am wenigsten produziert.	**SBERT:** 0.91 **LLM as Judge:** *(n=1)* ▪ Clarity: 5 ▪ Completeness: 4 ▪ Conciseness: 1 ▪ PC: 5 ▪ Neutrality: 5 ▪ Correctness: 5
2. Alt text **Short description (metadata):** Senkrechtes Balkendiagramm. Titel: Westafrika produziert am meisten Kakao. Untertitel: Schätzungen Produktion 2015/16 in t. Waagrechte Achse: Côte d'Ivoire, Ghana, Indonesien, Kamerun, Ecuador, Nigeria, Brasilien. Senkrechte Achse: Null bis 1,6 Millionen Tonnen. **Short description (overview):** Côte d'Ivoire und Ghana dominieren die Kakaoproduktion mit dem höchsten Ausstoss. Die anderen Länder produzieren deutlich weniger Kakao. **Long description:** Côte d'Ivoire produziert am meisten Kakao mit 1,581 Millionen Tonnen, gefolgt von Ghana mit 0,778 Millionen Tonnen. Indonesien, Kamerun und Ecuador liegen im mittleren Bereich mit 0,35 Millionen, 0,25 Millionen und 0,232 Millionen Tonnen. Nigeria und Brasilien bilden das Schlusslicht mit 0,2 Millionen beziehungsweise 0,14 Millionen Tonnen.	**SBERT:** 0.89 **LLM as Judge:** *(n=1)* ▪ Clarity: 5 ▪ Completeness: 5 ▪ Conciseness: 2 ▪ PC: 5 ▪ Neutrality: 5 ▪ Correctness: 5
3. Alt text **Short description (metadata):** Senkrechtes Balkendiagramm. Titel: Westafrika produziert am meisten Kakao. Untertitel: Schätzungen Produktion 2015/16 in t. Waagrechte Achse: Côte d'Ivoire, Ghana, Indonesien, Kamerun, Ecuador, Nigeria, Brasilien. Senkrechte Achse: Null bis 1,6 Millionen Tonnen. **Short description (overview):** Côte d'Ivoire hat die mit Abstand grösste Kakaoproduktion, gefolgt von Ghana. Alle anderen Länder produzieren deutlich weniger, wobei Indonesien den drittgrössten Wert aufweist. **Long description:** Côte d'Ivoire produziert mit etwa 1,58 Millionen Tonnen am meisten Kakao, gefolgt von Ghana mit etwa 0,78 Millionen Tonnen. Indonesien hat mit 0,35 Millionen Tonnen die drittgrösste Produktion, während Kamerun und Ecuador annähernd 0,25 und 0,23 Millionen Tonnen produzieren. Nigeria und Brasilien produzieren mit 0,2 beziehungsweise 0,14 Millionen Tonnen am wenigsten.	**SBERT:** 0.89 **LLM as Judge:** *(n=1)* ▪ Clarity: 5 ▪ Completeness: 5 ▪ Conciseness: 1 ▪ PC: 5 ▪ Neutrality: 5 ▪ Correctness: 5

4. Alt text **Short description (metadata):** Senkrechtes Balkendiagramm. Titel: Westafrika produziert am meisten Kakao. Untertitel: Schätzungen Produktion 2015/16 in t. Waagrechte Achse: Côte d'Ivoire, Ghana, Indonesien, Kamerun, Ecuador, Nigeria, Brasilien. Senkrechte Achse: Null bis 1,6 Millionen Tonnen. **Short description (overview):** Die Côte d'Ivoire und Ghana dominieren die Kakaoproduktion deutlich, was die Aussage des Titels "Westafrika produziert am meisten Kakao" widerspiegelt, da beide Länder in Westafrika liegen. **Long description:** Die Côte d'Ivoire produziert am meisten Kakao (etwa 1,58 Millionen Tonnen), gefolgt von Ghana (etwa 0,78 Millionen Tonnen). Indonesien liegt mit 0,35 Millionen Tonnen auf Platz drei. Kamerun, Ecuador und Nigeria produzieren jeweils zwischen 0,20 und 0,25 Millionen Tonnen. Brasilien bildet das Schlusslicht mit etwa 0,14 Millionen Tonnen.	**SBERT:** 0.88 **LLM as Judge:** *(n=1)* ▪ Clarity: 5 ▪ Completeness: 5 ▪ Conciseness: 1 ▪ PC: 5 ▪ Neutrality: 3 ▪ Correctness: 3
5. Alt text **Short description (metadata):** Senkrechtes Balkendiagramm. Titel: Westafrika produziert am meisten Kakao. Untertitel: Schätzungen Produktion 2015/16 in t (in Millionen). Waagrechte Achse: Côte d'Ivoire, Ghana, Indonesien, Kamerun, Ecuador, Nigeria, Brasilien. Senkrechte Achse: null bis 1,6 Millionen Tonnen. **Short description (overview):** Côte d'Ivoire hat die mit Abstand höchste Kakaoproduktion, gefolgt von Ghana. Die restlichen Länder produzieren deutlich weniger Kakao. **Long description:** Côte d'Ivoire produziert am meisten mit 1,581 Millionen Tonnen. Ghana folgt mit 0,778 Millionen Tonnen. Indonesien (0,35 Millionen Tonnen) und Kamerun (0,25 Millionen Tonnen) bilden eine Mittelgruppe. Darauf folgen Ecuador (0,232 Millionen Tonnen), Nigeria (0,200 Millionen Tonnen) und Brasilien (0,140 Millionen Tonnen), deren Produktion am niedrigsten ist.	**SBERT:** 0.88 **LLM as Judge:** *(n=1)* ▪ Clarity: 5 ▪ Completeness: 5 ▪ Conciseness: 2 ▪ PC: 5 ▪ Neutrality: 5 ▪ Correctness: 5
6. Alt text **Short description (metadata):** Senkrechtes Balkendiagramm. Titel: Westafrika produziert am meisten Kakao. Untertitel: Schätzungen Produktion 2015/16 in t. Waagrechte Achse: Côte d'Ivoire, Ghana, Indonesien, Kamerun, Ecuador, Nigeria, Brasilien. Senkrechte Achse: Null bis 1,6 Millionen Tonnen. **Short description (overview):** Côte d'Ivoire hat die mit Abstand grösste Kakaoproduktion, gefolgt von Ghana. Alle anderen Länder produzieren deutlich weniger. **Long description:** Côte d'Ivoire produziert mit 1,581 Millionen Tonnen am meisten Kakao. Ghana folgt mit einem Wert von 0,778 Millionen Tonnen. Indonesien erzielt 0,35 Millionen Tonnen. Kamerun und Ecuador liegen mit rund 0,25 und 0,232 Millionen Tonnen im Mittelfeld. Nigeria und Brasilien produzieren mit 0,2 beziehungsweise 0,14 Millionen Tonnen am wenigsten.	**SBERT:** 0.88 **LLM as Judge:** *(n=1)* ▪ Clarity: 5 ▪ Completeness: 5 ▪ Conciseness: 2 ▪ PC: 5 ▪ Neutrality: 3 ▪ Correctness: 5

7. Alt text **Short description (metadata):** Senkrechtes Balkendiagramm. Titel: Westafrika produziert am meisten Kakao. Untertitel: Schätzungen Produktion 2015/16 in t. Waagrechte Achse: Côte d'Ivoire, Ghana, Indonesien, Kamerun, Ecuador, Nigeria, Brasilien. Senkrechte Achse: Null bis 1,6 Millionen Tonnen. **Short description (overview):** Côte d'Ivoire ist mit Abstand der grösste Kakaoproduzent, gefolgt von Ghana. Die gesamte Kakaoproduktion in Westafrika übersteigt die der anderen Länder deutlich. **Long description:** Die Côte d'Ivoire produziert 1,58 Millionen Tonnen Kakao. Ghana liegt bei 778.000 Tonnen. Indonesien kommt auf 350.000 Tonnen. Kamerun produziert 250.000 Tonnen und Ecuador 232.000 Tonnen. Nigeria und Brasilien produzieren 200.000, respektive 140.000 Tonnen.	**SBERT:** 0.87 **LLM as Judge:** *(n=1)* ▪ Clarity: 5 ▪ Completeness: 5 ▪ Conciseness: 1 ▪ PC: 5 ▪ Neutrality: 5 ▪ Correctness: 5
8. Alt text **Short description (metadata):** Senkrechtes Balkendiagramm. Titel: Westafrika produziert am meisten Kakao. Untertitel: Schätzungen Produktion 2015/16 in t. Waagrechte Achse: Côte d'Ivoire, Ghana, Indonesien, Kamerun, Ecuador, Nigeria, Brasilien. Senkrechte Achse: 0 bis 1,6 Millionen Tonnen. **Short description (overview):** Die Elfenbeinküste und Ghana produzieren mit Abstand am meisten Kakao, was die Aussage des Titels - dass Westafrika am meisten Kakao produziert - untermauert. **Long description:** Die Elfenbeinküste produziert 1,58 Millionen Tonnen Kakao, gefolgt von Ghana mit 0,78 Millionen Tonnen. Indonesien liegt mit 0,35 Millionen Tonnen deutlich dahinter. Kamerun (0,25), Ecuador (0,23), Nigeria (0,20) und Brasilien (0,14) folgen mit weiter sinkenden Produktionsmengen.	**SBERT:** 0.87 **LLM as Judge:** *(n=1)* ▪ Clarity: 5 ▪ Completeness: 5 ▪ Conciseness: 2 ▪ PC: 5 ▪ Neutrality: 5 ▪ Correctness: 4
9. Alt text **Short description (metadata):** Senkrechtes Balkendiagramm. Titel: Westafrika produziert am meisten Kakao. Untertitel: Schätzungen Produktion 2015/16 in t. Waagrechte Achse: Côte d'Ivoire, Ghana, Indonesien, Kamerun, Ecuador, Nigeria, Brasilien. Senkrechte Achse: Null bis 1,6 Millionen Tonnen. **Short description (overview):** Côte d'Ivoire und Ghana stechen als die grössten Kakaoproduzenten hervor, mit Côte d'Ivoire an der Spitze. Die anderen aufgeführten Länder produzieren deutlich weniger Kakao. **Long description:** Côte d'Ivoire produziert mit etwa 1,58 Millionen Tonnen am meisten. Auf Platz zwei folgt Ghana mit circa 778000 Tonnen. Indonesien erzielt 350000 Tonnen. Kamerun, Ecuador und Nigeria liegen zwischen 250000 und 200000 Tonnen. Brasilien liegt mit 140000 Tonnen am Ende.	**SBERT:** 0.87 **LLM as Judge:** *(n=1)* ▪ Clarity: 5 ▪ Completeness: 3 ▪ Conciseness: 2 ▪ PC: 5 ▪ Neutrality: 4 ▪ Correctness: 5

10. Alt text	SBERT: 0.84
Short description (metadata): Senkrechtes Balkendiagramm. Titel: Westafrika produziert am meisten Kakao. Untertitel: Schätzungen Produktion 2015/16 in t (in Millionen). Waagrechte Achse: Côte d'Ivoire, Ghana, Indonesien, Kamerun, Ecuador, Nigeria, Brasilien. Senkrechte Achse: Auf einer Skala von null bis 1,6 Millionen Tonnen. **Short description (overview):** Côte d'Ivoire und Ghana dominieren die Kakaoproduktion deutlich, wobei Côte d'Ivoire der größte Produzent ist. Die restlichen Länder liegen weit darunter. **Long description:** Côte d'Ivoire produziert mit 1,581 Millionen Tonnen am meisten Kakao, gefolgt von Ghana mit 778.000 Tonnen. Indonesien produziert 350.000 Tonnen. Kamerun und Ecuador liegen mit 250.000 beziehungsweise 232.000 Tonnen im mittleren Bereich. Nigeria verzeichnet 200.000 Tonnen und Brasilien 140.000 Tonnen.	**LLM as Judge:** *(n=1)* ▪ Clarity: 5 ▪ Completeness: 5 ▪ Conciseness: 2 ▪ PC: 5 ▪ Neutrality: 3 ▪ Correctness: 5

01da15f0f6a6396873566efb70b639df

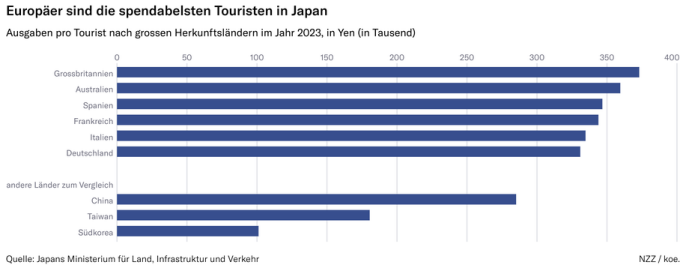

Golden standard

Short description (metadata): Waagrechtes Balkendiagramm. Titel: Europäer sind die spendabelsten Touristen in Japan. Untertitel: Ausgaben pro Tourist nach grossen Herkunftsländern im Jahr 2023, in Yen (in Tausend). Waagrechte Achse: 0 bis 400 Tausend Yen. Senkrechte Achse: Grossbritannien, Australien, Spanien, Frankreich, Italien, Deutschland, China, Taiwan und Südkorea.

Short description (overview): Europäische Touristen und die aus Australien geben im Durchschnitt deutlich mehr aus als Touristen aus Vergleichsländer aus Asien.

Long description: In Grossbritannien, Australien, Spanien, Frankreich, Italien und Deutschland geben Touristen zwischen rund 330 und 370 Tausend Yen aus. Andere Länder im Vergleich: China: 285, Taiwan: 181, Südkorea: 101.

1. Alt text **Short description (metadata):** Waagerechtes Balkendiagramm. Titel: Europäer sind die spendabelsten Touristen in Japan. Untertitel: Ausgaben pro Tourist nach grossen Herkunftsländern im Jahr 2023, in Yen (in Tausend). Waagrechte Achse: 0 bis 400 Tausend Yen. Senkrechte Achse: Grossbritannien, Australien, Spanien, Frankreich, Italien, Deutschland, China, Taiwan, Südkorea. **Short description (overview):** Touristen aus europäischen Ländern und Australien geben pro Person am meisten Geld in Japan aus. Grossbritannien liegt an der Spitze. Touristen aus Südkorea geben am wenigsten aus. **Long description:** Grossbritannien, Australien, Spanien, Frankreich, Italien und Deutschland geben zwischen 330 und 373 Tausend Yen aus, wobei Grossbritannien mit 373 Tausend Yen am meisten ausgibt. China folgt mit 285 Tausend Yen. Taiwan liegt bei 180 Tausend Yen und Südkorea gibt mit 101 Tausend Yen am wenigsten aus.	**SBERT:** 0.91 **LLM as Judge:** *(n=1)* ▪ Clarity: 5 ▪ Completeness: 5 ▪ Conciseness: 1 ▪ PC: 5 ▪ Neutrality: 4 ▪ Correctness: 5
2. Alt text **Short description (metadata):** Waagerechtes Balkendiagramm. Titel: Europäer sind die spendabelsten Touristen in Japan. Untertitel: Ausgaben pro Tourist nach grossen Herkunftsländern im Jahr 2023, in Yen (in Tausend). Waagrechte Achse: 0 bis 400. Senkrechte Achse: Grossbritannien, Australien, Spanien, Frankreich, Italien, Deutschland, China, Taiwan, Südkorea. Sowie die Kategorie andere Länder zum Vergleich. **Short description (overview):** Touristen aus europäischen Ländern und Australien haben die höchsten Ausgaben in Japan. Am spendabelsten sind Touristen aus Grossbritannien, gefolgt von Australien und Spanien. Südkorea weist die geringsten Ausgaben aus. **Long description:** Touristen aus Grossbritannien geben 373 Tausend Yen aus, gefolgt von Australien mit 359 Tausend Yen, Spanien mit 347 Tausend Yen, Frankreich mit 344 Tausend Yen, Italien mit 335 Tausend Yen und Deutschland mit 331 Tausend Yen. China liegt bei 285 Tausend Yen, Taiwan bei 181 Tausend Yen und Südkorea bei 101 Tausend Yen.	**SBERT:** 0.9 **LLM as Judge:** *(n=1)* ▪ Clarity: 5 ▪ Completeness: 5 ▪ Conciseness: 2 ▪ PC: 5 ▪ Neutrality: 3 ▪ Correctness: 5
3. Alt text **Short description (metadata):** Waagerechtes Balkendiagramm. Titel: Europäer sind die spendabelsten Touristen in Japan. Untertitel: Ausgaben pro Tourist nach grossen Herkunftsländern im Jahr 2023, in Yen (in Tausend). Waagerechte Achse: 0 bis 400 Tausend Yen. Senkrechte Achse: Grossbritannien, Australien, Spanien, Frankreich, Italien, Deutschland, China, Taiwan, Südkorea. **Short description (overview):** Touristen aus europäischen Ländern (Grossbritannien, Spanien, Frankreich, Italien, Deutschland) geben im Durchschnitt am meisten Geld aus, gefolgt von Australien. Touristen aus asiatischen Ländern (China, Taiwan, Südkorea) geben deutlich weniger aus. **Long description:** Grossbritannien hat mit 373 Tausend Yen (pro Tourist) die höchsten Ausgaben, gefolgt von Australien mit 359 Tausend Yen und Spanien mit 347 Tausend Yen. Frankreich (344 Tausend) und Italien (335 Tausend) liegen im Mittelfeld der europäischen Länder. Deutschland schließt die europäischen Länder mit 331 Tausend Yen ab. China verzeichnet 285 Tausend Yen, Taiwan 181 Tausend Yen und Südkorea 101 Tausend Yen.	**SBERT:** 0.89 **LLM as Judge:** *(n=1)* ▪ Clarity: 5 ▪ Completeness: 5 ▪ Conciseness: 1 ▪ PC: 5 ▪ Neutrality: 3 ▪ Correctness: 2

4. Alt text **Short description (metadata):** Waagerechtes Balkendiagramm. Titel: Europäer sind die spendabelsten Touristen in Japan. Untertitel: Ausgaben pro Tourist nach grossen Herkunftsländern im Jahr 2023, in Yen (in Tausend). Waagrechte Achse: 0 bis 400 Tausend Yen. Senkrechte Achse: Grossbritannien, Australien, Spanien, Frankreich, Italien, Deutschland, China, Taiwan, Südkorea. **Short description (overview):** Touristen aus europäischen Ländern und Australien haben die höchsten Ausgaben pro Tourist, wobei Grossbritannien die Rangliste anführt. Im Vergleich dazu sind die Ausgaben von Touristen aus asiatischen Ländern (China, Taiwan, Südkorea) geringer. **Long description:** Grossbritannien liegt mit 373025 Yen an der Spitze, gefolgt von Australien mit 359500 Yen. Spanien, Frankreich, Italien und Deutschland folgen mit Werten zwischen 346703 und 330929 Yen. China verzeichnet 285115 Yen, Taiwan 180510 Yen und Südkorea bildet das Schlusslicht mit 101110 Yen.	**SBERT:** 0.89 **LLM as Judge:** *(n=1)* ▪ Clarity: 5 ▪ Completeness: 5 ▪ Conciseness: 2 ▪ PC: 5 ▪ Neutrality: 3 ▪ Correctness: 5
5. Alt text **Short description (metadata):** Waagerechtes Balkendiagramm. Titel: Europäer sind die spendabelsten Touristen in Japan. Untertitel: Ausgaben pro Tourist nach grossen Herkunftsländern im Jahr 2023, in Yen (in Tausend). Waagrechte Achse: 0 bis 400 Tausend Yen. Senkrechte Achse: Grossbritannien, Australien, Spanien, Frankreich, Italien, Deutschland, China, Taiwan, Südkorea. **Short description (overview):** Touristen aus europäischen Ländern (Grossbritannien, Spanien, Frankreich, Italien, Deutschland) und Australien geben pro Person am meisten Geld aus, während asiatische Länder (China, Taiwan, Südkorea) deutlich niedrigere Ausgaben aufweisen. **Long description:** Grossbritannien führt mit 373 Tausend Yen, gefolgt von Australien (360 Tausend) und Spanien (347 Tausend). Frankreich (344 Tausend), Italien (335 Tausend) und Deutschland (331 Tausend) liegen im oberen Bereich. China liegt bei 285 Tausend Yen. Taiwan (181 Tausend) und Südkorea (101 Tausend) bilden das Schlusslicht mit den niedrigsten Ausgaben.	**SBERT:** 0.89 **LLM as Judge:** *(n=1)* ▪ Clarity: 5 ▪ Completeness: 5 ▪ Conciseness: 1 ▪ PC: 5 ▪ Neutrality: 3 ▪ Correctness: 5
6. Alt text **Short description (metadata):** Waagerechtes Balkendiagramm. Titel: Europäer sind die spendabelsten Touristen in Japan. Untertitel: Ausgaben pro Tourist nach grossen Herkunftsländern im Jahr 2023, in Yen (in Tausend). Waagrechte Achse: 0 bis 400. Senkrechte Achse: Grossbritannien, Australien, Spanien, Frankreich, Italien, Deutschland, China, Taiwan, Südkorea. **Short description (overview):** Touristen aus europäischen Ländern und Australien geben pro Person am meisten Geld aus, während chinesische, taiwanesische und südkoreanische Touristen deutlich weniger ausgeben. **Long description:** Grossbritannien hat mit 373025 Tausend Yen die höchsten Ausgaben pro Tourist, gefolgt von Australien mit 359500 Tausend Yen und Spanien mit 346703 Tausend Yen. Frankreich (343891 Tausend Yen), Italien (334700 Tausend Yen) und Deutschland (330929 Tausend Yen) bilden eine Gruppe mit nur leicht tieferen Werten. China liegt mit 285115 Tausend Yen deutlich tiefer. Taiwan und Südkorea weisen mit 180510 Tausend Yen bzw. 101110 Tausend Yen die niedrigsten Ausgaben auf.	**SBERT:** 0.87 **LLM as Judge:** *(n=1)* ▪ Clarity: 5 ▪ Completeness: 5 ▪ Conciseness: 1 ▪ PC: 5 ▪ Neutrality: 3 ▪ Correctness: 5

7. Alt text **Short description (metadata):** Waagerechtes Balkendiagramm. Titel: Europäer sind die spendabelsten Touristen in Japan. Untertitel: Ausgaben pro Tourist nach grossen Herkunftsländern im Jahr 2023, in Yen (in Tausend). Waagrechte Achse: 0 bis 400 Tausend Yen. Senkrechte Achse: Grossbritannien, Australien, Spanien, Frankreich, Italien, Deutschland sowie China, Taiwan, Südkorea. **Short description (overview):** Touristen aus Grossbritannien sind mit weitem Abstand am spendabelsten, vor Reisenden aus Australien, Spanien und Frankreich. Deutsche, Italiener und Franzosen liegen nah beieinander. Im Vergleich dazu geben Touristen aus Südkorea deutlich weniger aus. Die Europäer zeigen die höchsten Ausgaben. **Long description:** Die Ausgaben von Touristen aus Grossbritannien erreichen mit etwa 373 Tausend Yen den Höchstwert. Reisende aus Australien, Spanien, Frankreich, Italien und Deutschland geben zwischen 331 Tausend und 360 Tausend Yen aus und bilden eine Gruppe mit hohen Ausgaben. Touristen aus China geben etwa 285 Tausend Yen aus, gefolgt von Taiwan mit 181 Tausend Yen und Südkorea mit circa 101 Tausend Yen.	**SBERT:** 0.87 **LLM as Judge:** *(n=1)* ▪ Clarity: 4 ▪ Completeness: 5 ▪ Conciseness: 1 ▪ PC: 5 ▪ Neutrality: 4 ▪ Correctness: 5
8. Alt text **Short description (metadata):** Waagrechtes Balkendiagramm. Titel: Europäer sind die spendabelsten Touristen in Japan. Untertitel: Ausgaben pro Tourist nach grossen Herkunftsländern im Jahr 2023, in Yen. Waagrechte Achse: Ausschnitt 0 bis 400 (in Tausenden Yen). Senkrechte Achse: Grossbritannien, Australien, Spanien, Frankreich, Italien, Deutschland, China, Taiwan, Südkorea. **Short description (overview):** Touristen aus europäischen Ländern (Grossbritannien, Spanien, Frankreich, Italien, Deutschland) und Australien sind die spendabelsten in Japan, mit Ausgaben über 330.000 Yen pro Person. Touristen aus Südkorea geben am wenigsten aus, mit nur rund 101.000 Yen. **Long description:** Grossbritannien führt mit etwa 373.000 Yen. Australien folgt mit etwa 360.000 Yen und Spanien mit 347.000 Yen. Frankreich, Italien und Deutschland liegen alle dicht beieinander zwischen 331.000 und 344.000 Yen. Touristen aus China geben etwa 285.000 Yen aus. Taiwan liegt bei 181.000 Yen und Südkorea bildet das Schlusslicht mit rund 101.000 Yen.	**SBERT:** 0.86 **LLM as Judge:** *(n=1)* ▪ Clarity: 5 ▪ Completeness: 4 ▪ Conciseness: 2 ▪ PC: 5 ▪ Neutrality: 3 ▪ Correctness: 5
9. Alt text **Short description (metadata):** waagerechtes Balkendiagramm. Titel: Europäer sind die spendabelsten Touristen in Japan. Untertitel: Ausgaben pro Tourist nach grossen Herkunftsländern im Jahr 2023, in Yen. Waagrechte Achse: (Ausschnitt) 0 bis 400 Tausend Yen. Senkrechte Achse: Grossbritannien, Australien, Spanien, Frankreich, Italien, Deutschland, China, Taiwan, Südkorea. **Short description (overview):** Die Ausgaben pro Tourist in Japan sind bei chinesischen Touristen rund doppelt so hoch wie bei koreanischen Touristen und bei europäischen Touristen rund dreimal so hoch. Touristen aus Grossbritannien geben am meisten aus, knapp gefolgt von australischen Touristen. **Long description:** Grossbritannien liegt mit 373025 Yen vorne, gefolgt von Australien mit 359500 Yen und Spanien mit 346703 Yen. Dann folgen Frankreich mit 343891 Yen, Italien mit 334700 Yen und Deutschland mit 330929 Yen. China liegt mit 285115 Yen deutlich tiefer. Taiwan gibt 180510 Yen aus, gefolgt von Südkorea mit 101110 Yen.	**SBERT:** 0.85 **LLM as Judge:** *(n=1)* ▪ Clarity: 4 ▪ Completeness: 5 ▪ Conciseness: 2 ▪ PC: 5 ▪ Neutrality: 5 ▪ Correctness: 2

10. Alt text	SBERT: 0.84
Short description (metadata): und der **Short description (overview):** sind entsprechend angepasst. **Kurzbeschreibung:** Waagerechtes Balkendiagramm. Titel: Europäer sind die spendabelsten Touristen in Japan. Untertitel: Ausgaben pro Tourist nach grossen Herkunftsländern im Jahr 2023, in Yen (in Tausend). Waagrechte Achse: Ausgaben pro Tourist von null bis 400 Tausend Yen. Senkrechte Achse: Grossbritannien, Australien, Spanien, Frankreich, Italien, Deutschland, China, Taiwan, Südkorea sowie die Kategorie "andere Länder zum Vergleich" (zehn Kategorien). **Überblick:** Die Ausgaben pro Tourist sind bei Touristen aus Grossbritannien am höchsten, gefolgt von Australien und Spanien. Die europäischen Länder dominieren die Spitzenplätze der Ausgaben pro Tourist im Vergleich zu den anderen aufgeführten Herkunftsländern. **Long description:** Grossbritannien führt mit 373.025 Yen, gefolgt von Australien mit 359.500 Yen und Spanien mit 346.703 Yen. Frankreich gibt 343.891 Yen pro Tourist aus, Italien 334.700 Yen und Deutschland 330.929 Yen. China liegt bei 285.115 Yen, Taiwan bei 180.510 Yen und Südkorea bei 101.110 Yen.	**LLM as Judge:** *(n=1)* ▪ Clarity: 2 ▪ Completeness: 2 ▪ Conciseness: 1 ▪ PC: 5 ▪ Neutrality: 3 ▪ Correctness: 3

01c8403779c54eaa3618b44952a05470

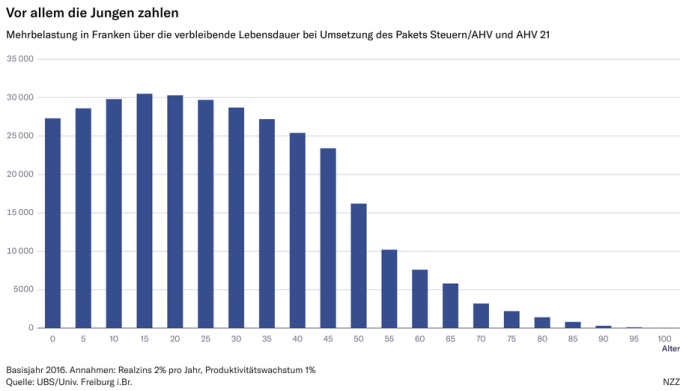

Golden standard

Short description (metadata): Senkrechtes Balkendiagramm. Titel: Vor allem die Jungen zahlen. Untertitel: Mehrbelastung in Franken über die verbleibende Lebensdauer bei Umsetzung des Pakets Steuern/AHV und AHV 21. Basisjahr 2016. Annahme: Realzins von 2 % pro Jahr, Produktivitätswachstum 1 %. Waagrechte Achse: Alter 0 bis 100 Jahre in 5-Jahres-Schritten. Senkrechte Achse: 0 bis 35'000 Franken.

Short description (overview): Die Mehrbelastung ist bei jungen Menschen am höchsten und sinkt mit zunehmendem Alter deutlich.

Long description: Die Mehrbelastung beginnt bei rund 27'000 Franken mit 0 Jahren, steigt bis 15 Jahre auf ihren Höchststand von gut 30'000 Franken und sinkt dann wieder. Bis 40 Jahre sind es noch über 25'000 Franken. Ab 45 Jahren sinkt sie deutlich, beträgt mit 50 Jahren rund 17'000 Franken und mit 55 Jahren etwa 10'000 Franken. Mit 70 unterschreitet sie die 5'000-Franken-Marke und sinkt dann auf den Tiefstwert von 10 Franken mit 100 Jahren.

1. Alt text **Short description (metadata):** Senkrechtes Balkendiagramm. Titel: Vor allem die Jungen zahlen. Untertitel: Mehrbelastung in Franken über die verbleibende Lebensdauer bei Umsetzung des Pakets Steuern/AHV und AHV 21. Waagrechte Achse: Alter von 0 bis 100 Jahren in Fünfjahresschritten. Senkrechte Achse: 0 bis 35 000 Franken. **Short description (overview):** Die Mehrbelastung ist in den jungen Altersgruppen am höchsten, erreicht den Spitzenwert bei 15 Jahren und sinkt danach stetig ab. **Long description:** Die Mehrbelastung beginnt bei 27 300 Franken für Neugeborene, steigt bis zu einem Maximum von 30 500 Franken bei 15 Jahren und sinkt danach kontinuierlich bis auf 16 200 Franken bei 50 Jahren. Der Wert sinkt weiter auf 100 Franken bei 95 Jahren und beträgt nur noch 10 Franken bei 100 Jahren.	**SBERT:** 0.91 **LLM as Judge:** *(n=1)* ▪ Clarity: 5 ▪ Completeness: 4 ▪ Conciseness: 2 ▪ PC: 5 ▪ Neutrality: 5 ▪ Correctness: 5
2. Alt text **Short description (metadata):** Senkrechtes Balkendiagramm. Titel: Vor allem die Jungen zahlen. Untertitel: Mehrbelastung in Franken über die verbleibende Lebensdauer bei Umsetzung des Pakets Steuern/AHV und AHV 21. Waagrechte Achse: Alter von 0 bis 100 in Fünfjahresabständen. Senkrechte Achse: 0 bis 35 000 Franken. **Short description (overview):** Die Mehrbelastung ist in jungen Jahren am höchsten, mit einem Maximum bei 15 Jahren, und sinkt danach kontinuierlich mit zunehmendem Alter. **Long description:** Die Mehrbelastung beginnt bei 27 300 Franken für Neugeborene, steigt auf das Maximum von 30 500 Franken bei 15-Jährigen und sinkt danach stetig. Ab dem Alter von 50 Jahren fällt die Belastung stark von 23 400 Franken auf 16 200 Franken und weiter auf 5800 Franken bei 65-Jährigen. Bei 100-Jährigen beträgt die Mehrbelastung 10 Franken.	**SBERT:** 0.89 **LLM as Judge:** *(n=1)* ▪ Clarity: 4 ▪ Completeness: 3 ▪ Conciseness: 1 ▪ PC: 5 ▪ Neutrality: 5 ▪ Correctness: 3
3. Alt text **Short description (metadata):** Senkrechtes Balkendiagramm. Titel: Vor allem die Jungen zahlen. Untertitel: Mehrbelastung in Franken über die verbleibende Lebensdauer bei Umsetzung des Pakets Steuern/AHV und AHV 21. Waagrechte Achse: 0 bis 100 Jahre in Fünfjahresabständen, beschriftet als "Alter". Senkrechte Achse: 0 bis 35 000 Franken. **Short description (overview):** Die Mehrbelastung ist bei Personen zwischen 0 und 35 Jahren am höchsten und sinkt danach stetig mit zunehmendem Alter. **Long description:** Die Mehrbelastung beginnt bei 27 300 Franken für Neugeborene und steigt bis zum Alter von 15 Jahren auf das Maximum von 30 500 Franken. Danach sinkt sie langsam bis 35 Jahre (27 200 Franken) und fällt dann stark ab. Im Alter von 50 Jahren beträgt sie 16 200 Franken, im Alter von 65 Jahren 5800 Franken und im Alter von 100 Jahren nur noch 10 Franken.	**SBERT:** 0.89 **LLM as Judge:** *(n=1)* ▪ Clarity: 5 ▪ Completeness: 4 ▪ Conciseness: 2 ▪ PC: 5 ▪ Neutrality: 4 ▪ Correctness: 4

4. Alt text **Short description (metadata):** Senkrechtes Balkendiagramm. Titel: Vor allem die Jungen zahlen. Untertitel: Mehrbelastung in Franken über die verbleibende Lebensdauer bei Umsetzung des Pakets Steuern/AHV und AHV 21. Waagrechte Achse: 0 bis 100 Jahre in Fünfjahresabständen. Senkrechte Achse: 0 bis 35 000 Franken. **Short description (overview):** Die Mehrbelastung ist für Personen bis etwa 30 Jahre am höchsten und nimmt mit steigendem Alter stetig, aber ungleichmässig ab. **Long description:** Bei 0 bis 5 Jahren liegt die Mehrbelastung bei 27 300 bis 28 600 Franken. Sie steigt bis zum Alter von 15 Jahren auf das Maximum von 30 500 Franken und sinkt danach bis etwa 40 Jahre auf 25 400 Franken. Danach sinkt die Belastung stark und kontinuierlich von 16 200 Franken bei 50 Jahren auf 10 Franken bei 100 Jahren.	**SBERT:** 0.88 **LLM as Judge:** *(n=1)* ▪ Clarity: 4 ▪ Completeness: 3 ▪ Conciseness: 2 ▪ PC: 5 ▪ Neutrality: 5 ▪ Correctness: 3
5. Alt text **Short description (metadata):** Senkrechtes Balkendiagramm. Titel: Vor allem die Jungen zahlen. Untertitel: Mehrbelastung in Franken über die verbleibende Lebensdauer bei Umsetzung des Pakets Steuern/AHV und AHV 21. Waagrechte Achse: Alter von 0 bis 100 in 5-Jahres-Schritten. Senkrechte Achse: 0 bis 35 000 Franken. **Short description (overview):** Die Mehrbelastung ist bei den jüngeren Altersgruppen am höchsten und nimmt mit steigendem Alter stark ab. **Long description:** Die Mehrbelastung beginnt bei 27 300 Franken für Neugeborene, steigt auf den Höchstwert von 30 500 Franken bei 15-Jährigen und sinkt danach kontinuierlich. Bis zum Alter von 45 Jahren liegt die Belastung über 23 000 Franken. Ab 50 Jahren sinkt sie deutlich von 16 200 Franken auf 5800 Franken bei 65-Jährigen und erreicht ihren Tiefstwert bei 10 Franken für 100-Jährige.	**SBERT:** 0.88 **LLM as Judge:** *(n=1)* ▪ Clarity: 5 ▪ Completeness: 5 ▪ Conciseness: 2 ▪ PC: 5 ▪ Neutrality: 5 ▪ Correctness: 5
6. Alt text **Short description (metadata):** Senkrechtes Balkendiagramm. Titel: Vor allem die Jungen zahlen. Untertitel: Mehrbelastung in Franken über die verbleibende Lebensdauer bei Umsetzung des Pakets Steuern/AHV und AHV 21. Waagrechte Achse: 0 bis 100 Jahre in Fünfjahresabständen. Senkrechte Achse: 0 bis 35 000 Franken. **Short description (overview):** Die Mehrbelastung ist für jüngere Menschen am höchsten und sinkt mit zunehmendem Alter stark ab. Die höchste Belastung liegt bei 15 Jahren. **Long description:** Die Mehrbelastung beginnt bei 0 Jahren mit 27 300 Franken und steigt bis auf den Spitzenwert von 30 500 Franken bei 15 Jahren. Bis zu 35 Jahren sinkt die Belastung nur leicht auf 27 200 Franken. Danach sinkt die Belastung schneller und erreicht bei 50 Jahren 16 200 Franken. Ab 65 Jahren sinkt die Mehrbelastung unter 6000 Franken erheblich, bis sie bei 80 Jahren nur noch 1400 Franken beträgt und bei 100 Jahren mit 10 Franken am tiefsten ist.	**SBERT:** 0.88 **LLM as Judge:** *(n=1)* ▪ Clarity: 5 ▪ Completeness: 4 ▪ Conciseness: 2 ▪ PC: 5 ▪ Neutrality: 3 ▪ Correctness: 5

7. Alt text **Short description (metadata):** Senkrechtes Balkendiagramm. Titel: Vor allem die Jungen zahlen. Untertitel: Mehrbelastung in Franken über die verbleibende Lebensdauer bei Umsetzung des Pakets Steuern/AHV und AHV 21. Waagrechte Achse: Alter von 0 bis 100 in Fünfjahresschritten. Senkrechte Achse: 0 bis 35 000 Franken. **Short description (overview):** Die Mehrbelastung ist bei den Jüngsten am höchsten, erreicht einen Höchstwert bei Alter 15 und sinkt anschliessend kontinuierlich mit zunehmendem Alter. **Long description:** Die Mehrbelastung beginnt bei 27 300 Franken für Neugeborene, steigt auf den Höchstwert von 30 500 Franken bei Alter 15 und sinkt kontinuierlich. Bei Alter 50 beträgt die Mehrbelastung 16 200 Franken und bei Alter 65 noch 5800 Franken. Ab Alter 85 sinkt die Belastung unter 1000 Franken.	**SBERT:** 0.87 **LLM as Judge:** *(n=1)* ▪ Clarity: 5 ▪ Completeness: 4 ▪ Conciseness: 2 ▪ PC: 5 ▪ Neutrality: 5 ▪ Correctness: 4
8. Alt text **Short description (metadata):** Senkrechtes Balkendiagramm. Titel: Vor allem die Jungen zahlen. Untertitel: Mehrbelastung in Franken über die verbleibende Lebensdauer bei Umsetzung des Pakets Steuern/AHV und AHV 21. Waagrechte Achse: Alter von 0 bis 100 Jahren in Fünfjahresabschnitten. Senkrechte Achse: 0 bis 35 000 Franken. **Short description (overview):** Die Mehrbelastung ist für jüngere Menschen am höchsten und sinkt mit zunehmendem Alter stark ab. **Long description:** Die Mehrbelastung beginnt bei 27 300 Franken für Neugeborene, steigt bis zu einem Alter von 15 Jahren auf den Höchstwert von 30 500 Franken und sinkt danach kontinuierlich bis auf 23 400 Franken im Alter von 45 Jahren. Zwischen 45 und 65 Jahren fällt der Wert stark auf 5 800 Franken und geht bis zum Alter von 100 Jahren auf 10 Franken zurück.	**SBERT:** 0.87 **LLM as Judge:** *(n=1)* ▪ Clarity: 5 ▪ Completeness: 4 ▪ Conciseness: 2 ▪ PC: 5 ▪ Neutrality: 5 ▪ Correctness: 5
9. Alt text **Short description (metadata):** Senkrechtes Balkendiagramm. Titel: Vor allem die Jungen zahlen. Untertitel: Mehrbelastung in Franken über die verbleibende Lebensdauer bei Umsetzung des Pakets Steuern/AHV und AHV 21. Waagrechte Achse: Alter von 0 bis 100 in Fünfjahresabständen. Senkrechte Achse: 0 bis 35 000 Franken. **Short description (overview):** Die Mehrbelastung ist bei einer Altersspanne von 5 bis 35 Jahren am höchsten und sinkt danach kontinuierlich bis zum Alter von 100 Jahren. Die Mehrbelastung von 0-jährigen liegt unter der ältester Junger Erwachsener und Älterer. **Long description:** Die Mehrbelastung beginnt bei 0-jährigen mit 27 300 Franken. Sie steigt bis zum Alter von 15 Jahren auf maximal 30 500 Franken und sinkt dann bis zum Alter von 45 Jahren auf 23 400 Franken. Zwischen 50 und 65 Jahren fällt der Wert von 16 200 auf 5800 Franken. Ab 70 Jahren sinkt die Belastung weiter und beträgt bei 100-jährigen noch 10 Franken.	**SBERT:** 0.86 **LLM as Judge:** *(n=1)* ▪ Clarity: 3 ▪ Completeness: 4 ▪ Conciseness: 2 ▪ PC: 4 ▪ Neutrality: 5 ▪ Correctness: 5

10. Alt text	SBERT: 0.85
Short description (metadata): Senkrechtes Balkendiagramm. Titel: Vor allem die Jungen zahlen. Untertitel: Mehrbelastung in Franken über die verbleibende Lebensdauer bei Umsetzung des Pakets Steuern/AHV und AHV 21. Waagrechte Achse: 21 Alterskategorien von 0 bis 100 Jahren in Fünfjahresabständen. Senkrechte Achse: 0 bis 35 000 Franken. **Short description (overview):** Die Mehrbelastung ist für Personen bis etwa 30 Jahre am höchsten und sinkt danach stark, besonders ab 50 Jahren. Dies bestätigt die Aussage des Titels, dass vor allem die Jungen zahlen. **Long description:** Personen im Alter von 0 Jahren betragen eine Mehrbelastung von 27 300 Franken, die in den nächsten Jahren stetig steigt und bei 15 Jahren den Höhepunkt von 30 500 Franken erreicht. Danach sinkt die Belastung langsam bis 45 Jahre (23 400 Franken) und fällt dann stark ab 50 Jahre (16 200 Franken) bis auf 10 Franken für 100-Jährige.	**LLM as Judge:** *(n=1)* ▪ Clarity: 5 ▪ Completeness: 4 ▪ Conciseness: 1 ▪ PC: 5 ▪ Neutrality: 4 ▪ Correctness: 5

0819c8effbf081938ef522a3693b1b52

Golden standard

Short description (metadata): Waagrechtes Balkendiagramm. Titel: Die Ukraine erhält nur wenige Waffen aus den westlichen Beständen. Untertitel: Bei Kriegsbeginn 2022 vorhandenes und funktionstüchtiges Kriegsgerät in westlichen Arsenalen. Waagrechte Achse: 0 bis 11'000 Waffen. Senkrechte Achse: Kampf- und Schützenpanzer, 155- und 152-Haubitzen, Mehrfachraketenwerfer. Drei Balken pro Waffen-Kategorie: Nato ohne EU-Staaten (dunkelblau), EU-Staaten (hellblau), Zusagen an die Ukraine (orange).

Short description (overview): Der Anteil der zugesagten Waffen an die Ukraine umfassen einen kleinen Teil (zwischen 7 und 12 Prozent) des einsatzbereiten Kriegsgeräts in westlichen Arsenalen.

Long description: Kampf- und Schützenpanzer sind knapp 11'000 (Nato ohne EU-Staaten) und etwa 4700 (EU-Staaten) verfügbar. Insgesamt sind der Ukraine knapp 790 zugesagt. Haubitzen sind rund 4100(Nato) und knapp 2700 (EU) verfügbar. Zugesagt an die Ukraine gut 650. Mehrfachraketenwerfer besitzen beide Gruppen je rund 820, zugesagt an die Ukraine sind 100.

1. Alt text **Short description (metadata):** Senkrechtes Balkendiagramm. Titel: Die Ukraine erhält nur wenige Waffen aus den westlichen Beständen. Untertitel: Bei Kriegsbeginn 2022 vorhandenes und funktionstüchtiges Kriegsgerät in westlichen Arsenalen. Waagrechte Achse: 0 bis 11000 Stück. Senkrechte Achse: Kampf- und Schützenpanzer, 155- und 152-Haubitzen, Mehrfachraketenwerfer. Drei Balken pro Waffentyp: Nato ohne EU-Staaten (dunkelblau), EU-Staaten (hellblau), Zusagen an die Ukraine (orange). **Short description (overview):** Die Anzahl der zugesagten Waffen an die Ukraine ist im Vergleich zu den Beständen der Nato und EU-Staaten gering. Die größten Bestände in Nato-Staaten (ohne EU) sind Kampf- und Schützenpanzer sowie 155- und 152-Haubitzen. **Long description:** Die Bestände an Kampf- und Schützenpanzern belaufen sich in Nato-Staaten ohne EU auf 10931 und in EU-Staaten auf 4696, wobei 788 zugesagt wurden. Bei 155- und 152-Haubitzen sind 4130 in Nato-Staaten (ohne EU) und 2696 in EU-Staaten vorhanden; 657 wurden zugesagt. Die Bestände an Mehrfachraketenwerfern sind mit 828 in Nato-Staaten (ohne EU) und 824 in EU-Staaten deutlich kleiner, die Zusagen an die Ukraine betragen 100.	**SBERT:** 0.9 **LLM as Judge:** *(n=1)* ▪ Clarity: 5 ▪ Completeness: 5 ▪ Conciseness: 1 ▪ PC: 5 ▪ Neutrality: 2 ▪ Correctness: 5
2. Alt text **Short description (metadata):** Senkrechtes Balkendiagramm. Titel: Die Ukraine erhält nur wenige Waffen aus den westlichen Beständen. Untertitel: Bei Kriegsbeginn 2022 vorhandenes und funktionstüchtiges Kriegsgerät in westlichen Arsenalen. Waagrechte Achse: 0 bis 11000 Stück. Senkrechte Achse: Kampf- und Schützenpanzer, 155- und 152-Haubitzen, Mehrfachraketenwerfer. Drei Balken pro Gerätetyp: Nato (ohne EU-Staaten) (dunkelblau), EU-Staaten (hellblau), Zusagen an die Ukraine (orange). **Short description (overview):** Die Anzahl der zugesagten Waffensysteme an die Ukraine liegt in allen drei Kategorien deutlich unter dem Bestand in den NATO- und EU-Staaten zu Kriegsbeginn 2022. Die Bestände an Kampf- und Schützenpanzern sind in der NATO (ohne EU) am höchsten, gefolgt von Haubitzen und Mehrfachraketenwerfern. **Long description:** Die Bestände an Kampf- und Schützenpanzern reichen von 4696 in EU-Staaten bis zu 10931 in NATO (ohne EU) und die Zusagen betragen 788. Die Bestände an 155- und 152-Haubitzen liegen zwischen 2696 (EU) und 4130 (NATO ohne EU), mit 657 Zugesagten. Bei Mehrfachraketenwerfern sind die Bestände mit 824 (EU) und 828 (NATO ohne EU) vergleichbar; die Zusagen betragen 100.	**SBERT:** 0.89 **LLM as Judge:** *(n=1)* ▪ Clarity: 5 ▪ Completeness: 5 ▪ Conciseness: 1 ▪ PC: 5 ▪ Neutrality: 3 ▪ Correctness: 5

3. Alt text **Short description (metadata):** Senkrechtes Balkendiagramm. Titel: Die Ukraine erhält nur wenige Waffen aus den westlichen Beständen. Untertitel: Bei Kriegsbeginn 2022 vorhandenes und funktionstüchtiges Kriegsgerät in westlichen Arsenalen. Waagrechte Achse: Tausender Schritte von Null bis 11 Tausend Einheiten. Senkrechte Achse: Kampf- und Schützenpanzer, 155- und 152-Haubitzen, Mehrfachraketenwerfer. Drei Balken pro Kategorie: Nato (ohne EU-Staaten) (Dunkelblau), EU-Staaten (Hellblau), Zusagen an die Ukraine (Orange). **Short description (overview):** Die Bestände an Kriegsgerät in westlichen Arsenalen (Nato ohne EU-Staaten plus EU-Staaten) sind in allen drei Kategorien deutlich höher als die Zusagen an die Ukraine. Die Bestände an Kampf- und Schützenpanzern sind am grössten (über 15 Tausend), gefolgt von 155- und 152-Haubitzen (über 6800) und Mehrfachraketenwerfern (über 1650). **Long description:** Nato (ohne EU-Staaten) besitzt mit 10931 Kampf- und Schützenpanzern am meisten in dieser Kategorie, während EU-Staaten 4696 besitzen. Beide zusammen sind fast zwanzigmal so viel wie die 788 Zusagen an die Ukraine. Bei 155- und 152-Haubitzen besitzen Nato und EU-Staaten 4130 respektive 2696 Einheiten, was zusammen mehr als zehnmal so viel ist wie die 657 Zusagen. Im Vergleich zu den Beständen (828 für Nato, 824 für EU-Staaten) sind die 100 Zusagen für Mehrfachraketenwerfer am geringsten.	**SBERT:** 0.87 **LLM as Judge:** *(n=1)* ▪ Clarity: 5 ▪ Completeness: 5 ▪ Conciseness: 1 ▪ PC: 5 ▪ Neutrality: 2 ▪ Correctness: 3
4. Alt text **Short description (metadata):** Senkrechtes Balkendiagramm. Titel: Die Ukraine erhält nur wenige Waffen aus den westlichen Beständen. Untertitel: Bei Kriegsbeginn 2022 vorhandenes und funktionstüchtiges Kriegsgerät in westlichen Arsenalen. Waagrechte Achse: 0 bis 11000 Stück. Senkrechte Achse: Kampf- und Schützenpanzer, 155- und 152-Haubitzen, Mehrfachraketenwerfer. Pro Kategorie drei Balken: Nato (ohne EU-Staaten) (dunkelblau), EU-Staaten (hellblau), Zusagen an die Ukraine (orange). **Short description (overview):** Die Bestände an Kriegsgerät in den Nato-Ländern (ohne EU) und in den EU-Staaten sind jeweils deutlich höher als die zugesagten Lieferungen an die Ukraine für alle drei Gerätekategorien. **Long description:** Die Bestände an Kampf- und Schützenpanzern sind mit 10931 (Nato, ohne EU) und 4696 (EU-Staaten) am höchsten, zugesagt wurden 788. Die Bestände an 155- und 152-Haubitzen liegen bei 4130 (Nato, ohne EU) und 2696 (EU-Staaten), bei 657 zugesagten Einheiten. Mehrfachraketenwerfer sind mit 828 (Nato, ohne EU) und 824 (EU-Staaten) im geringsten Bestand, davon sind 100 für die Ukraine zugesagt.	**SBERT:** 0.87 **LLM as Judge:** *(n=1)* ▪ Clarity: 5 ▪ Completeness: 5 ▪ Conciseness: 1 ▪ PC: 5 ▪ Neutrality: 2 ▪ Correctness: 5

5. Alt text **Short description (metadata):** Senkrechtes Balkendiagramm. Titel: Die Ukraine erhält nur wenige Waffen aus den westlichen Beständen. Untertitel: Bei Kriegsbeginn 2022 vorhandenes und funktionstüchtiges Kriegsgerät in westlichen Arsenalen. Waagrechte Achse: 0 bis 11000 Stück. Senkrechte Achse: Kampf- und Schützenpanzer, 155- und 152-Haubitzen, Mehrfachraketenwerfer. Drei Balken pro Waffentyp: Nato (ohne EU-Staaten) (dunkelblau), EU-Staaten (hellblau), Zusagen an die Ukraine (orange). **Short description (overview):** Die Bestände an funktionsfähigem Kriegsgerät in den westlichen Arsenalen übersteigen die Zusagen an die Ukraine in allen drei Kategorien bei weitem, wobei "Kampf- und Schützenpanzer" und "155- und 152-Haubitzen" die größten Bestände aufweisen. Die Zusagen an die Ukraine sind im Vergleich zu den Beständen der Nato und der EU-Staaten sehr gering. **Long description:** Die vorhandenen Kampf- und Schützenpanzer betragen 10931 in Nato-Staaten (ohne EU) und 4696 in EU-Staaten, wogegen nur 788 Zusagen an die Ukraine gemacht wurden. Bei 155- und 152-Haubitzen sind 4130 in Nato-Staaten und 2696 in EU-Staaten vorhanden, mit 657 Zusagen. Bei Mehrfachraketenwerfern sind die Bestände mit 828 (Nato) und 824 (EU) geringer, die Zusagen belaufen sich auf 100.	**SBERT:** 0.86 **LLM as Judge:** *(n=1)* ▪ Clarity: 5 ▪ Completeness: 5 ▪ Conciseness: 1 ▪ PC: 5 ▪ Neutrality: 3 ▪ Correctness: 4
6. Alt text **Short description (metadata):** Senkrechtes Balkendiagramm. Titel: Die Ukraine erhält nur wenige Waffen aus den westlichen Beständen. Untertitel: Bei Kriegsbeginn 2022 vorhandenes und funktionstüchtiges Kriegsgerät in westlichen Arsenalen. Waagrechte Achse: 0 bis 11000. Senkrechte Achse: Kampf- und Schützenpanzer, 155- und 152-Haubitzen, Mehrfachraketenwerfer. Drei Balken pro Kategorie: Nato (ohne EU-Staaten) (dunkelblau), EU-Staaten (hellblau), Zusagen an die Ukraine (orange). **Short description (overview):** Die Bestände an Kriegsgerät in westlichen Arsenalen sind in allen drei Kategorien deutlich höher als die zugesagten Lieferungen an die Ukraine. Die größten Bestände haben die Nato-Staaten außerhalb der EU. **Long description:** Nato-Staaten (ohne EU) verfügen über 10931 Kampf- und Schützenpanzer, EU-Staaten über 4696. Demgegenüber stehen 788 Zusagen an die Ukraine. Bei 155- und 152-Haubitzen haben die Nato-Staaten (ohne EU) 4130, EU-Staaten 2696 und die Zusagen betragen 657. Bei Mehrfachraketenwerfern sind es 828 bei Nato (ohne EU), 824 bei der EU und 100 Zusagen an die Ukraine.	**SBERT:** 0.86 **LLM as Judge:** *(n=1)* ▪ Clarity: 5 ▪ Completeness: 5 ▪ Conciseness: 1 ▪ PC: 5 ▪ Neutrality: 2 ▪ Correctness: 5

7. Alt text **Short description (metadata):** Senkrechtes Balkendiagramm. Titel: Die Ukraine erhält nur wenige Waffen aus den westlichen Beständen. Untertitel: Bei Kriegsbeginn 2022 vorhandenes und funktionstüchtiges Kriegsgerät in westlichen Arsenalen. Waagrechte Achse: Tausender Schritte von Null bis 11000. Senkrechte Achse: Kampf- und Schützenpanzer, 155- und 152-Haubitzen, Mehrfachraketenwerfer. Drei Balken pro Kategorie: Nato ohne EU-Staaten (dunkelblau), EU-Staaten (hellblau), Zusagen an die Ukraine (orange). **Short description (overview):** Die Bestände an funktionsfähigem Kriegsgerät in den Nato-Staaten (ohne EU) und den EU-Staaten sind in allen drei Kategorien deutlich höher als die Zusagen an die Ukraine, wobei die Bestände an Kampf- und Schützenpanzern am größten sind. **Long description:** Kampf- und Schützenpanzer weisen mit 10931 im Nato-Bereich und 4696 in den EU-Staaten die höchsten Bestände auf. Zusagen an die Ukraine für Kampf- und Schützenpanzer betragen nur 788. Bei den Haubitzen belaufen sich die Bestände auf 4130 (Nato) und 2696 (EU), während 657 zugesagt wurden. Mehrfachraketenwerfer sind mit 828 (Nato) und 824 (EU) am geringsten vorhanden, davon wurden 100 zugesagt.	**SBERT:** 0.86 **LLM as Judge:** *(n=1)* ▪ Clarity: 5 ▪ Completeness: 5 ▪ Conciseness: 1 ▪ PC: 5 ▪ Neutrality: 3 ▪ Correctness: 5
8. Alt text **Short description (metadata):** Senkrechtes Balkendiagramm. Titel: Die Ukraine erhält nur wenige Waffen aus den westlichen Beständen. Untertitel: Bei Kriegsbeginn 2022 vorhandenes und funktionstüchtiges Kriegsgerät in westlichen Arsenalen. Waagrechte Achse: 0 bis 12000 Stück. Senkrechte Achse: Kampf- und Schützenpanzer, 155- und 152-Haubitzen, Mehrfachraketenwerfer. Drei Balken pro Kategorie: Nato (ohne EU-Staaten) (dunkelblau), EU-Staaten (hellblau), Zusagen an die Ukraine (orange). **Short description (overview):** Die Bestände an Kriegsgerät in Nato- und EU-Staaten sind in allen drei Kategorien deutlich höher als die zugesagten Lieferungen an die Ukraine. Die Bestände der Nato (ohne EU-Staaten) sind durchweg am höchsten. **Long description:** Bei Kampf- und Schützenpanzern sind die Bestände der Nato (ohne EU-Staaten) mit 10931 am größten, gefolgt von der EU mit 4696, während die Zusagen bei 788 liegen. Bei 155- und 152-Haubitzen hat die Nato (ohne EU-Staaten) 4130, die EU 2696, und die Zusagen betragen 657. Bei Mehrfachraketenwerfern sind die Bestände in der Nato (ohne EU-Staaten) mit 828 und in der EU mit 824 vergleichbar, die Zusagen belaufen sich auf 100.	**SBERT:** 0.86 **LLM as Judge:** *(n=1)* ▪ Clarity: 5 ▪ Completeness: 5 ▪ Conciseness: 1 ▪ PC: 5 ▪ Neutrality: 3 ▪ Correctness: 4

9. Alt text **Short description (metadata):** Senkrechtes Balkendiagramm. Titel: Die Ukraine erhält nur wenige Waffen aus den westlichen Beständen. Untertitel: Bei Kriegsbeginn 2022 vorhandenes und funktionstüchtiges Kriegsgerät in westlichen Arsenalen. Waagrechte Achse: 0 bis 11000 Stückzählung. Senkrechte Achse: Kampf- und Schützenpanzer, 155- und 152-Haubitzen, Mehrfachraketenwerfer. Drei Balken pro Waffentyp: Nato (ohne EU-Staaten) (dunkelblau), EU-Staaten (hellblau), Zusagen an die Ukraine (orange). **Short description (overview):** Die Bestände an Kriegsgerät in den Nato- und EU-Staaten sind um ein Vielfaches höher als die Zusagen an die Ukraine. Insbesondere bei Kampf- und Schützenpanzern sind die Bestände am größten, während die Zusagen deutlich geringer sind. **Long description:** Kampf- und Schützenpanzer sind mit 10931 (Nato ohne EU) und 4696 (EU-Staaten) am häufigsten, mit 788 Zusagen an die Ukraine. Bei 155- und 152-Haubitzen stehen 4130 (Nato ohne EU) und 2696 (EU-Staaten) Bestände 657 Zusagen gegenüber. Die Mehrfachraketenwerferbestände betragen 828 (Nato ohne EU) und 824 (EU-Staaten), mit nur 100 Zusagen.	**SBERT:** 0.85 **LLM as Judge:** *(n=1)* ▪ Clarity: 5 ▪ Completeness: 5 ▪ Conciseness: 2 ▪ PC: 5 ▪ Neutrality: 3 ▪ Correctness: 5
10. Alt text **Short description (metadata):** Senkrechtes Balkendiagramm. Titel: Die Ukraine erhält nur wenige Waffen aus den westlichen Beständen. Untertitel: Bei Kriegsbeginn 2022 vorhandenes und funktionstüchtiges Kriegsgerät in westlichen Arsenalen. Waagrechte Achse: 0 bis 11000 Stück. Senkrechte Achse: Kampf- und Schützenpanzer, 155- und 152-Haubitzen, Mehrfachraketenwerfer. Drei Balken pro Kategorie: Nato (ohne EU-Staaten) (dunkelblau), EU-Staaten (hellblau), Zusagen an die Ukraine (orange). **Short description (overview):** Die Bestände an funktionsfähigem Kriegsgerät in westlichen Arsenalen, insbesondere bei Kampf- und Schützenpanzern, übersteigen die Zusagen an die Ukraine bei weitem. Die größten Bestände in allen Kategorien sind bei der Nato (ohne EU-Staaten) zu finden. **Long description:** Nato (ohne EU-Staaten) besitzt mit 10931 Kampf- und Schützenpanzern und 4130 Haubitzen die größten Bestände in den militärischen Bereichen. Die EU-Staaten verfügen über Bestände von 4696 Kampf- und Schützenpanzern und 2696 Haubitzen. Die Zusagen an die Ukraine belaufen sich auf 788 Kampf- und Schützenpanzer sowie 657 Haubitzen. Bei den Mehrfachraketenwerfern sind die Bestände von Nato (ohne EU-Staaten) mit 828 und EU-Staaten mit 824 fast gleich hoch, während die Zusagen nur 100 betragen.	**SBERT:** 0.85 **LLM as Judge:** *(n=1)* ▪ Clarity: 5 ▪ Completeness: 5 ▪ Conciseness: 1 ▪ PC: 5 ▪ Neutrality: 3 ▪ Correctness: 5

01e843ba181f97facd55faf6789b906a

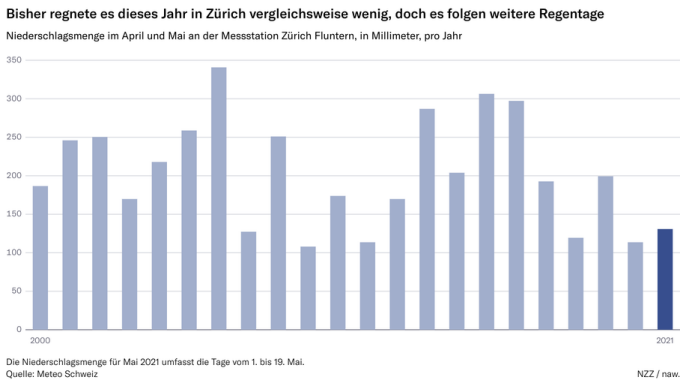

Golden standard
Short description (metadata): Senkrechtes Balkendiagramm. Titel: Bisher regnete es dieses Jahr in Zürich vergleichsweise wenig, doch es folgen weitere Regentage. Untertitel: Niederschlagsmenge im April und Mai an der Messstation Zürich Fluntern, in Millimetern, pro Jahr. Die Niederschlagsmenge für Mai 2021 umfasst die Tage vom 1. bis 19. Mai. Waagrechte Achse: Jahre 2000 bis 2021. Senkrechte Achse: 0 bis 350 Millimeter. **Short description (overview):** Die Niederschlagsmenge in Zürich im April und Mai zeigt zwischen 2000 und 2021 keine klare Tendenz. Die Werte schwanken zwischen 100 und 350 Millimetern pro Jahr. **Long description:** Im betrachteten Zeitraum liegt der Durchschnitt bei rund 200 Millimetern. In einzelnen Jahren, sind es höhere Werte von über 300 Millimetern (2006, 2015), während die Niederschlagsmenge in anderen Jahren zwischen 100 und 150 Millimetern liegt (2007, 2009, 2011, 2018, 2020). Im Jahr 2021 beträgt die bisher gemessene Niederschlagsmenge rund 130 Millimeter, basierend auf Messungen bis zum 19. Mai.

1. Alt text **Short description (metadata):** Senkrechtes Balkendiagramm. Titel: Bisher regnete es dieses Jahr in Zürich vergleichsweise wenig, doch es folgen weitere Regentage. Untertitel: Niederschlagsmenge im April und Mai an der Messstation Zürich Fluntern, in Millimeter, pro Jahr. Waagrechte Achse: Zeitraum 2000 bis 2021. Senkrechte Achse: 0 bis 350 Millimeter. **Short description (overview):** Die Niederschlagsmenge schwankt stark zwischen den Jahren, mit einem Höchstwert im Jahr 2006. Die Menge für 2021 liegt im unteren Bereich der letzten Jahre. **Long description:** Die Niederschlagsmenge schwankt zwischen 108,0 Millimetern (2009) und 340,8 Millimetern (2006). Der Durchschnitt liegt bei etwa 200 Millimetern. Der niedrigste Wert liegt 2009 bei 108,0 Millimetern. Die Niederschlagsmenge für 2021 beträgt 130,8 Millimeter.	**SBERT:** 0.89 **LLM as Judge:** *(n=1)* ▪ Clarity: 4 ▪ Completeness: 3 ▪ Conciseness: 1 ▪ PC: 5 ▪ Neutrality: 3 ▪ Correctness: 3
2. Alt text **Short description (metadata):** Senkrechtes Balkendiagramm. Titel: Bisher regnete es dieses Jahr in Zürich vergleichsweise wenig, doch es folgen weitere Regentage. Untertitel: Niederschlagsmenge im April und Mai an der Messstation Zürich Fluntern, in Millimeter, pro Jahr. Waagrechte Achse: Zeitraum 2000 bis 2021. Senkrechte Achse: Ausschnitt 0 bis 350 Millimeter. **Short description (overview):** Die Niederschlagsmenge schwankt deutlich über die Jahre, wobei 2006 der Höchstwert erreicht wird. 2021 liegt die Niederschlagsmenge im unteren Bereich. **Long description:** Die Niederschlagsmenge schwankt zwischen 108,0 Millimetern im Jahr 2009 und 340,8 Millimetern im Jahr 2006. Die durchschnittliche Niederschlagsmenge liegt bei etwa 200 Millimetern. 2021 beträgt die Niederschlagsmenge 130,8 Millimeter.	**SBERT:** 0.88 **LLM as Judge:** *(n=1)* ▪ Clarity: 4 ▪ Completeness: 2 ▪ Conciseness: 1 ▪ PC: 5 ▪ Neutrality: 3 ▪ Correctness: 3

3. Alt text **Short description (metadata):** Senkrechtes Balkendiagramm. Titel: Bisher regnete es dieses Jahr in Zürich vergleichsweise wenig, doch es folgen weitere Regentage. Untertitel: Niederschlagsmenge im April und Mai an der Messstation Zürich Fluntern, in Millimeter, pro Jahr. Waagrechte Achse: Zeitraum 2000 bis 2021. Senkrechte Achse: Ausschnitt 0 bis 350 Millimeter. **Short description (overview):** Die Niederschlagsmenge für die Monate April und Mai an der Messstation Zürich Fluntern schwankt stark zwischen 108,0 und 340,8 Millimetern. Die Niederschlagsmenge im Jahr 2021 ist vergleichsweise gering. **Long description:** Die Niederschlagsmenge zeigt starke Schwankungen zwischen 108,0 Millimeter im Jahr 2009 und 340,8 Millimeter im Jahr 2006. Der Durchschnitt liegt bei etwa 197 Millimeter. Im Jahr 2021 beträgt die Niederschlagsmenge 130,8 Millimeter, was eine vergleichsweise niedrige Zahl darstellt.	**SBERT:** 0.88 **LLM as Judge:** *(n=1)* ▪ Clarity: 4 ▪ Completeness: 2 ▪ Conciseness: 1 ▪ PC: 5 ▪ Neutrality: 3 ▪ Correctness: 3
4. Alt text **Short description (metadata):** Senkrechtes Balkendiagramm. Titel: Bisher regnete es dieses Jahr in Zürich vergleichsweise wenig, doch es folgen weitere Regentage. Untertitel: Niederschlagsmenge im April und Mai an der Messstation Zürich Fluntern, in Millimeter, pro Jahr. Waagrechte Achse: Zeitraum 2000 bis 2021. Senkrechte Achse: 0 bis 350 Millimeter. **Short description (overview):** Die Niederschlagsmenge im April und Mai schwankt im betrachteten Zeitraum stark, zeigt aber keinen klaren Trend. Die Menge im Jahr 2021 liegt im unteren Bereich. Die höchsten Werte werden in den Jahren 2006, 2015 und 2016 verzeichnet. **Long description:** Die Niederschlagsmenge im April und Mai schwankt zwischen 108.0 Millimetern (2009) und 340.8 Millimetern (2006). Der Wert für 2021 (130.8 Millimeter) liegt unter dem Durchschnitt der Jahre 2000 bis 2020. Besonders hohe Niederschlagsmengen gibt es 2006 (340.8 Millimeter), 2015 (306.4 Millimeter) und 2016 (297.3 Millimeter).	**SBERT:** 0.88 **LLM as Judge:** *(n=1)* ▪ Clarity: 5 ▪ Completeness: 4 ▪ Conciseness: 1 ▪ PC: 5 ▪ Neutrality: 2 ▪ Correctness: 3
5. Alt text **Short description (metadata):** Senkrechtes Balkendiagramm. Titel: Bisher regnete es dieses Jahr in Zürich vergleichsweise wenig, doch es folgen weitere Regentage. Untertitel: Niederschlagsmenge im April und Mai an der Messstation Zürich Fluntern, in Millimeter, pro Jahr. Waagrechte Achse: Zeitraum 2000 bis 2021. Senkrechte Achse: 0 bis 350 Millimeter. **Short description (overview):** Die Niederschlagsmenge zwischen April und Mai an der Messstation Zürich Fluntern schwankt stark über die Jahre. Der Höchstwert wurde 2006 gemessen. Die Niederschlagsmenge 2021 ist vergleichsweise niedrig und liegt im unteren Bereich der Messwerte. **Long description:** Die Niederschlagsmenge schwankt zwischen dem niedrigen Wert von 108.0 Millimetern (2009) und dem hohen Wert von 340.8 Millimetern (2006). Der Durchschnitt liegt bei etwa 197 Millimetern. Die Niederschlagsmenge 2021 beträgt 130.8 Millimeter.	**SBERT:** 0.85 **LLM as Judge:** *(n=1)* ▪ Clarity: 4 ▪ Completeness: 3 ▪ Conciseness: 2 ▪ PC: 5 ▪ Neutrality: 3 ▪ Correctness: 3

6. Alt text **Short description (metadata):** Senkrechtes Balkendiagramm. Titel: Bisher regnete es dieses Jahr in Zürich vergleichsweise wenig, doch es folgen weitere Regentage. Untertitel: Niederschlagsmenge im April und Mai an der Messstation Zürich Fluntern, in Millimeter, pro Jahr. Waagrechte Achse: 2000 bis 2021. Senkrechte Achse: 0 bis 350 Millimeter. **Short description (overview):** Die Niederschlagsmenge in Zürich Fluntern im April und Mai schwankt über die Jahre stark, weist jedoch keinen klaren Trend auf. **Long description:** Die Niederschlagsmenge startet im Jahr 2000 bei 186,6 Millimetern, schwankt in den folgenden Jahren und erreicht 2006 mit 340,8 Millimetern einen Höchstwert. Anschliessend schwanken die Werte weiter und liegen im Jahr 2021 mit 130,8 Millimetern im unteren Bereich.	**SBERT:** 0.85 **LLM as Judge:** *(n=1)* ▪ Clarity: 5 ▪ Completeness: 4 ▪ Conciseness: 2 ▪ PC: 5 ▪ Neutrality: 5 ▪ Correctness: 4
7. Alt text **Short description (metadata):** Senkrechtes Balkendiagramm. Titel: Bisher regnete es dieses Jahr in Zürich vergleichsweise wenig, doch es folgen weitere Regentage. Untertitel: Niederschlagsmenge im April und Mai an der Messstation Zürich Fluntern, in Millimeter, pro Jahr. Waagrechte Achse: Zeitraum 2000 bis 2021. Senkrechte Achse: 0 bis 350 Millimeter. **Short description (overview):** Die Niederschlagsmenge im April und Mai schwankt stark im beobachteten Zeitraum. Sie lag in den Jahren 2006, 2015 und 2016 am höchsten, während sie 2009, 2020 und 2011 am niedrigsten war. Die Menge im Jahr 2021 liegt im unteren Bereich. **Long description:** Die Niederschlagsmenge schwankt zwischen 108,0 Millimetern im Jahr 2009 (niedrigster Wert) und 340,8 Millimetern im Jahr 2006 (höchster Wert). Die Menge für Mai 2021 liegt mit 130,8 Millimetern im unteren Drittel der gemessenen Werte.	**SBERT:** 0.84 **LLM as Judge:** *(n=1)* ▪ Clarity: 5 ▪ Completeness: 4 ▪ Conciseness: 2 ▪ PC: 5 ▪ Neutrality: 4 ▪ Correctness: 5
8. Alt text **Short description (metadata):** Senkrechtes Balkendiagramm. Titel: Bisher regnete es dieses Jahr in Zürich vergleichsweise wenig, doch es folgen weitere Regentage. Untertitel: Niederschlagsmenge im April und Mai an der Messstation Zürich Fluntern, in Millimeter, pro Jahr. Waagrechte Achse: Zeitraum 2000 bis 2021. Senkrechte Achse: Ausschnitt 0 bis 350 Millimeter. **Short description (overview):** Die Niederschlagsmenge schwankt im dargestellten Zeitraum stark. Das Jahr 2021 weist mit 130.8 Millimetern eine der geringeren Mengen auf, was die Aussage des Titels bestätigt. **Long description:** Die Niederschlagsmenge beginnt im Jahr 2000 bei 186.6 Millimetern und steigt bis zu ihrem Höchststand 2006 mit 340.8 Millimetern. Danach schwankt sie stark, wobei die Mindestwerte um die 110 Millimeter liegen, erreicht in den Jahren 2009 (108.0 mm), 2020 (113.6 mm) und 2011 (113.6 mm). Der Endwert 2021 beträgt 130.8 Millimeter.	**SBERT:** 0.84 **LLM as Judge:** *(n=1)* ▪ Clarity: 4 ▪ Completeness: 5 ▪ Conciseness: 1 ▪ PC: 5 ▪ Neutrality: 2 ▪ Correctness: 4

9. Alt text **Short description (metadata):** Senkrechtes Balkendiagramm. Titel: Bisher regnete es dieses Jahr in Zürich vergleichsweise wenig, doch es folgen weitere Regentage. Untertitel: Niederschlagsmenge im April und Mai an der Messstation Zürich Fluntern, in Millimeter, pro Jahr. Waagrechte Achse: Zeitraum 2000 bis 2021. Senkrechte Achse: 0 bis 350 Millimeter. **Short description (overview):** Die Niederschlagsmenge schwankt stark zwischen den Jahren, mit einem Höchstwert im Jahr 2006. Die Menge im Jahr 2021 ist vergleichsweise niedrig. **Long description:** 2000 liegt der Wert bei 186,6 Millimetern. Bis 2006 steigen die Niederschlagsmengen, mit einem Spitzenwert von 340,8 Millimetern. Danach sinken sie stark und schwanken im weiteren Verlauf, wobei das Jahr 2020 einen Tiefstwert von 113,6 Millimetern aufweist. 2021 liegt die Niederschlagsmenge bei 130,8 Millimetern.	**SBERT:** 0.83 **LLM as Judge:** *(n=1)* ▪ Clarity: 5 ▪ Completeness: 4 ▪ Conciseness: 1 ▪ PC: 5 ▪ Neutrality: 3 ▪ Correctness: 2
10. Alt text **Short description (metadata):** Senkrechtes Balkendiagramm. Titel: Bisher regnete es dieses Jahr in Zürich vergleichsweise wenig, doch es folgen weitere Regentage. Untertitel: Niederschlagsmenge im April und Mai an der Messstation Zürich Fluntern, in Millimeter, pro Jahr. Waagrechte Achse: Zeitraum 2000 bis 2021 in Einjahresabständen. Senkrechte Achse: 0 bis 350 Millimeter. **Short description (overview):** Die Niederschlagsmengen in den Jahren 2000 bis 2021 schwanken stark, wobei 2006 der Höchstwert und 2009 der Tiefstwert verzeichnet werden. Im Jahr 2021 ist die Niederschlagsmenge im Vergleich zum Mittelwert der Vorjahre gering. **Long description:** Der Anfangswert der Niederschlagsmenge liegt 2000 bei 186,6 Millimetern. Der Verlauf schwankt stark. Die höchsten gemessenen Werte sind 2006 mit 340,8 und 2015 mit 306,4 Millimetern. Die geringsten Mengen sind 2009 und 2020 mit jeweils 108 und 113,6 Millimetern. Der Endwert beträgt 2021 130,8 Millimeter.	**SBERT:** 0.83 **LLM as Judge:** *(n=1)* ▪ Clarity: 5 ▪ Completeness: 4 ▪ Conciseness: 1 ▪ PC: 5 ▪ Neutrality: 2 ▪ Correctness: 3

016b459adf53c4e44c03cc7e70dbd26c

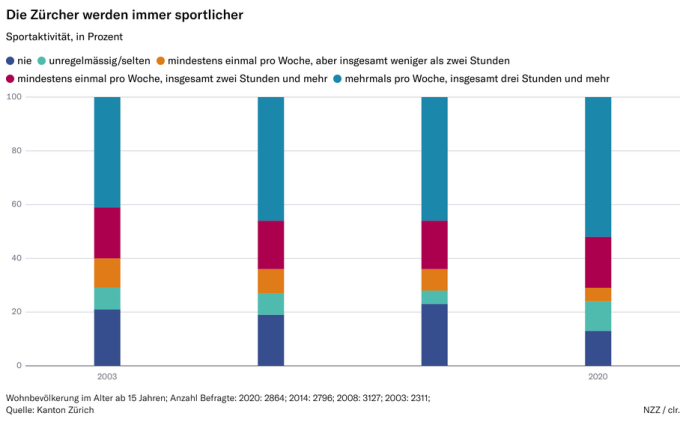

Golden standard

Short description (metadata): Senkrechtes Balkendiagramm. Titel: Die Zürcher werden immer sportlicher. Untertitel: Sportaktivität, in Prozent. Wohnbevölkerung im Alter ab 15 Jahren; Anzahl Befragte: 2020: 2864; 2014: 2796; 2008: 3127; 2003: 2311. Waagrechte Achse: 2003, 2008, 2014, 2020. Senkrechte Achse: 0 bis 100 Prozent. Pro Jahr ein Balken unterteilt in fünf Anteile: nie (blau), unregelmässig/selten (grün), mindestens einmal pro Woche, aber insgesamt weniger als zwei Stunden (orange), mindestens einmal pro Woche, insgesamt zwei Stunden und mehr (rot), mehrmals pro Woche drei Stunden, insgesamt drei Stunden und mehr (türkis).

Short description (overview): Von 2003 bis 2020 verändern sich die Aktivitätsanteile jeweils um minus 8 bis 11 Prozent. Am meisten steigt der Anteil von mehrmals pro Woche, insgesamt drei Stunden und mehr.

Long description: Zwischen 2003 und 2020 sinkt der Anteil derjenigen, die nie aktiv sind, um 8 Prozent, während der Anteil derjenigen, die mehrmals pro Woche aktiv sind, um 11 Prozent steigt. Die anderen Aktivitätsformen verändern sich weniger: unregelmässig/selten (plus 3 Prozent), mindestens einmal pro Woche, aber insgesamt weniger als zwei Stunden (minus 6 Prozent) und mindestens einmal pro Woche, insgesamt zwei Stunden und mehr (keine Veränderung).

1. Alt text	**SBERT:** 0.89
Short description (metadata): Senkrecht gestapeltes Balkendiagramm. Titel: Die Zürcher werden immer sportlicher. Untertitel: Sportaktivität, in Prozent. Waagrechte Achse: Zeitreihe: von 2003 bis 2020. Senkrechte Achse: (Ausschnitt) Null bis Einhundert Prozent. Segmente pro Balken: nie (blau), unregelmässig/selten (Türkis), mindestens einmal pro Woche, aber insgesamt weniger als zwei Stunden (Orange), mindestens einmal pro Woche, insgesamt zwei Stunden und mehr (Rot), mehrmals pro Woche, insgesamt drei Stunden und mehr (Dunkeltürkis). **Short description (overview):** Der Anteil der Personen, die mehrmals pro Woche für insgesamt drei Stunden und mehr Sport treiben, steigt von 41 Prozent im Jahr 2003 auf 52 Prozent im Jahr 2020. Der Anteil derjenigen, die nie Sport treiben, sinkt im gleichen Zeitraum deutlich. **Long description:** Der Anteil der Personen, die nie Sport treiben, sinkt von 21 Prozent im Jahr 2003 auf 13 Prozent im Jahr 2020. Der Wert für 'unregelmässig/selten' schwankt zwischen fünf und elf Prozent. Der Anteil der mindestens einmal pro Woche, aber insgesamt weniger als zwei Stunden Sporttreibenden sinkt von elf auf fünf Prozent. Die Gruppe 'mindestens einmal pro Woche, insgesamt zwei Stunden und mehr' bleibt mit 18 bis 19 Prozent relativ stabil. Die Gruppe der Personen, die 'mehrmals pro Woche, insgesamt drei Stunden und mehr' Sport treiben, steigt von 41 Prozent (2003) auf 52 Prozent (2020).	**LLM as Judge:** *(n=1)* ▪ Clarity: 5 ▪ Completeness: 5 ▪ Conciseness: 1 ▪ PC: 5 ▪ Neutrality: 5 ▪ Correctness: 4

2. Alt text **Short description (metadata):** Senkrecht gestapeltes Balkendiagramm. Titel: Die Zürcher werden immer sportlicher. Untertitel: Sportaktivität, in Prozent. Waagrechte Achse: Zeitreihe: 2003, 2008, 2014, 2020. Senkrechte Achse: 0 bis 100 Prozent. Segmente pro Balken: nie (dunkelblau), unregelmässig/selten (hellgrün), mindestens einmal pro Woche, aber insgesamt weniger als zwei Stunden (orange), mindestens einmal pro Woche, insgesamt zwei Stunden und mehr (weinrot), mehrmals pro Woche, insgesamt drei Stunden und mehr (türkis). **Short description (overview):** Über den Zeitraum von 2003 bis 2020 steigt die Sportaktivität der Zürcher Bevölkerung. Die Anteile der Personen, die mehrmals pro Woche und insgesamt drei Stunden und mehr Sport treiben, steigen von 41 Prozent auf 52 Prozent an und werden zum dominantesten Segment. **Long description:** Der Anteil der Personen, die mehrmals pro Woche und insgesamt drei Stunden und mehr Sport treiben, steigt von 41 Prozent in 2003 auf 52 Prozent in 2020. Der Anteil derjenigen, die nie Sport treiben, sinkt von 21 Prozent auf 13 Prozent. Die Kategorie unregelmässig oder selten schwankt zwischen fünf und elf Prozent. Die mittlere Kategorie mindestens einmal pro Woche und zwei Stunden oder mehr bleibt stabil bei 18 bis 19 Prozent.	**SBERT:** 0.87 **LLM as Judge:** *(n=1)* ▪ Clarity: 5 ▪ Completeness: 3 ▪ Conciseness: 1 ▪ PC: 5 ▪ Neutrality: 5 ▪ Correctness: 5
3. Alt text **Short description (metadata):** Senkrecht gestapeltes Balkendiagramm. Titel: Die Zürcher werden immer sportlicher. Untertitel: Sportaktivität, in Prozent. Waagrechte Achse: Zeitreihe: 2003, 2008, 2014, 2020. Senkrechte Achse: 0 bis 100 Prozent. Segmente pro Balken: nie (dunkelblau), unregelmässig/selten (hellgrün), mindestens einmal pro Woche, aber insgesamt weniger als zwei Stunden (orange), mindestens einmal pro Woche, insgesamt zwei Stunden und mehr (dunkelrot), mehrmals pro Woche, insgesamt drei Stunden und mehr (türkis). **Short description (overview):** Die höchsten Sportaktivitäten ('mindestens einmal pro Woche und mehr') steigen von 71 Prozent im Jahr 2003 auf 86 Prozent im Jahr 2020. Die Segmente mit geringerer Aktivität ("nie" und "unregelmässig/selten") sinken von 29 Prozent auf 14 Prozent. **Long description:** Über den gesamten Zeitraum steigt der Anteil der mehrmaligen sportlichen Betätigung pro Woche von 41 Prozent im Jahr 2003 auf 52 Prozent im Jahr 2020. Die Sportaktivität 'mindestens einmal pro Woche, aber insgesamt weniger als zwei Stunden' sinkt von 11 Prozent auf 5 Prozent. Der Anteil der Personen, die 'nie' Sport treiben, sinkt von 21 Prozent auf 13 Prozent, während die Kategorie 'unregelmässig/selten' von 8 Prozent auf 11 Prozent steigt.	**SBERT:** 0.86 **LLM as Judge:** *(n=1)* ▪ Clarity: 4 ▪ Completeness: 3 ▪ Conciseness: 1 ▪ PC: 2 ▪ Neutrality: 5 ▪ Correctness: 2

4. Alt text **Short description (metadata):** Senkrecht gestapeltes Balkendiagramm. Titel: Die Zürcher werden immer sportlicher. Untertitel: Sportaktivität, in Prozent. Waagrechte Achse: Zeitreihe: 2003 bis 2020 (Intervall: unregelmässig). Senkrechte Achse: 0 bis 100 Prozent. Segmente pro Balken: nie (dunkelblau), unregelmässig/selten (türkis), mindestens einmal pro Woche, aber insgesamt weniger als zwei Stunden (orange), mindestens einmal pro Woche, insgesamt zwei Stunden und mehr (weinrot), mehrmals pro Woche, insgesamt drei Stunden und mehr (blau). **Short description (overview):** Der Anteil der Bevölkerung in Zürich, der mehrmals pro Woche, insgesamt mindestens drei Stunden Sport treibt, steigt kontinuierlich an und dominiert die Sportaktivitätsraten über den gesamten Zeitraum von 2003 bis 2020. Die Segmentanteile jener, die nie Sport treiben, nehmen deutlich ab, während sich die anderen Segmente nur geringfügig verschieben. **Long description:** Der Anteil der Bevölkerung, die mehrmals pro Woche, insgesamt drei Stunden und mehr Sport treibt, steigt von 41 Prozent im Jahr 2003 auf 52 Prozent im Jahr 2020. Der Anteil der Personen, die nie Sport treiben, sinkt von 21 Prozent auf 13 Prozent. Die restlichen Segmente weisen geringere Veränderungen auf: Unregelmässig/selten steigt von acht auf elf Prozent. Mindestens einmal pro Woche, aber weniger als zwei Stunden, sinkt von elf auf fünf Prozent. Mindestens einmal pro Woche, zwei Stunden und mehr, bleibt relativ stabil bei 18 bis 19 Prozent.	**SBERT:** 0.86 **LLM as Judge:** *(n=1)* ▪ Clarity: 5 ▪ Completeness: 3 ▪ Conciseness: 1 ▪ PC: 5 ▪ Neutrality: 5 ▪ Correctness: 5
5. Alt text **Short description (metadata):** Senkrecht gestapeltes Balkendiagramm. Titel: Die Zürcher werden immer sportlicher. Untertitel: Sportaktivität, in Prozent. Waagrechte Achse: Zeitreihe: 2003 bis 2020. Senkrechte Achse: ausschnitt: 0 bis 100 Prozent. Segmente pro Balken: nie (dunkelblau), unregelmässig/selten (hellgrün), mindestens einmal pro Woche, aber insgesamt weniger als zwei Stunden (orange), mindestens einmal pro Woche, insgesamt zwei Stunden und mehr (weinrot), mehrmals pro Woche, insgesamt drei Stunden und mehr (türkis). **Short description (overview):** Während der Anteil der Personen, die nie Sport treiben, von 2003 bis 2020 stark sinkt, nimmt der Anteil der Personen, die mehrmals pro Woche Sport treiben, deutlich zu. **Long description:** Der Anteil der Personen, die nie Sport treiben (dunkelblau), sinkt von 21 Prozent im Jahr 2003 auf 13 Prozent im Jahr 2020. Im Gegensatz dazu steigt der Anteil der Personen, die mehrmals pro Woche, insgesamt drei Stunden und mehr (türkis), Sport treiben, von 41 Prozent auf 52 Prozent. Die anderen Kategorien bleiben im Zeitraum von 2003 bis 2020 relativ stabil, mit leichten Schwankungen um ihre Durchschnittswerte.	**SBERT:** 0.86 **LLM as Judge:** *(n=1)* ▪ Clarity: 5 ▪ Completeness: 3 ▪ Conciseness: 1 ▪ PC: 5 ▪ Neutrality: 5 ▪ Correctness: 4

6. Alt text **Short description (metadata):** Senkrecht gestapeltes Balkendiagramm. Titel: Die Zürcher werden immer sportlicher. Untertitel: Sportaktivität, in Prozent. Waagrechte Achse: Zeitreihe: 2003 bis 2020. Senkrechte Achse: 0 bis 100 Prozent. Segmente pro Balken: nie (dunkelblau), unregelmässig/selten (türkis), mindestens einmal pro Woche, aber insgesamt weniger als zwei Stunden (orange), mindestens einmal pro Woche, insgesamt zwei Stunden und mehr (weinrot), mehrmals pro Woche, insgesamt drei Stunden und mehr (blau). **Short description (overview):** Die sportliche Aktivität steigt kontinuierlich von 2003 bis 2020. Besonders stark nimmt der Anteil der mehrmals pro Woche Sporttreibenden zu, während der Anteil derjenigen, die nie Sport treiben, deutlich sinkt. **Long description:** Der Anteil der Personen, die mehrmals pro Woche, insgesamt drei Stunden und mehr Sport treiben (blau), steigt deutlich von 41 Prozent im Jahr 2003 auf 52 Prozent im Jahr 2020. Im gleichen Zeitraum sinkt der Anteil derjenigen, die nie Sport treiben (dunkelblau), von 21 auf 13 Prozent. Die Segmente "mindestens einmal pro Woche, insgesamt zwei Stunden und mehr" (weinrot) und "unregelmässig/selten" (türkis) bleiben mit 18 bis 19 bzw. 5 bis 11 Prozent relativ stabil. Das Segment "mindestens einmal pro Woche, aber insgesamt weniger als zwei Stunden" (orange) sinkt von 11 auf 5 Prozent.	**SBERT:** 0.86 **LLM as Judge:** *(n=1)* ▪ Clarity: 5 ▪ Completeness: 4 ▪ Conciseness: 2 ▪ PC: 5 ▪ Neutrality: 5 ▪ Correctness: 3
7. Alt text **Short description (metadata):** Senkrecht gestapeltes Balkendiagramm. Titel: Die Zürcher werden immer sportlicher. Untertitel: Sportaktivität, in Prozent. Waagrechte Achse: Zeitreihe: von 2003 bis 2020. Senkrechte Achse: 0 bis 100 Prozent. Segmente pro Balken: nie (dunkelblau), unregelmässig/selten (türkis), mindestens einmal pro Woche, aber insgesamt weniger als zwei Stunden (orange), mindestens einmal pro Woche, insgesamt zwei Stunden und mehr (dunkelrot), mehrmals pro Woche, insgesamt drei Stunden und mehr (hellblau). **Short description (overview):** Der Anteil der sportlich Aktiven (mehrmals pro Woche) steigt zwischen 2003 und 2020 deutlich an, während der Anteil der Inaktiven sinkt. Das Segment "mehrmals pro Woche, insgesamt drei Stunden und mehr" ist durchgehend das dominierende und erhöht seinen Anteil. **Long description:** Der Anteil der Befragten, die nie Sport treiben, sinkt von 21 Prozent im Jahr 2003 auf 13 Prozent im Jahr 2020. Das Segment "mehrmals pro Woche, insgesamt drei Stunden und mehr" steigt kontinuierlich von 41 Prozent auf 52 Prozent an, mit einem leichten Anstieg in den Jahren 2008 und 2014 auf 46 Prozent. Die "unregelmässig/selten" Sporttreibenden schwanken: 8 Prozent in 2003, ein starker Rückgang auf 5 Prozent in 2014, gefolgt von einem Anstieg auf 11 Prozent in 2020. Die mittlere Kategorie "mindestens einmal pro Woche, insgesamt zwei Stunden und mehr" bleibt stabil um 18 bis 19 Prozent.	**SBERT:** 0.85 **LLM as Judge:** *(n=1)* ▪ Clarity: 5 ▪ Completeness: 3 ▪ Conciseness: 1 ▪ PC: 5 ▪ Neutrality: 5 ▪ Correctness: 4

8. Alt text **Short description (metadata):** Senkrecht gestapeltes Balkendiagramm. Titel: Die Zürcher werden immer sportlicher. Untertitel: Sportaktivität, in Prozent. Waagrechte Achse: Zeitreihe: 2003, 2008, 2014, 2020. Senkrechte Achse: 0 bis 100 Prozent. Segmente pro Balken: nie (dunkelblau), unregelmässig/selten (hellgrün), mindestens einmal pro Woche, aber insgesamt weniger als zwei Stunden (orange), mindestens einmal pro Woche, insgesamt zwei Stunden und mehr (weinrot), mehrmals pro Woche, insgesamt drei Stunden und mehr (türkis). **Short description (overview):** Über den Zeitraum von 2003 bis 2020 zeigt sich eine Verschiebung hin zu mehr Sportaktivität. Der Anteil der Personen, die nie Sport treiben, sinkt deutlich, während der Anteil derer, die mehrmals pro Woche über drei Stunden Sport treiben, stark zunimmt und zum dominanten Segment wird. **Long description:** Der Anteil der Personen, die nie Sport treiben, sinkt von einundzwanzig Prozent im Jahr 2003 auf dreizehn Prozent im Jahr 2020. Das Segment "mehrmals pro Woche, insgesamt drei Stunden und mehr" steigt kontinuierlich von einundvierzig Prozent (2003) auf sechsundvierzig Prozent (2008 und 2014) und erreicht im Jahr 2020 zweiundfünfzig Prozent. Die Kategorie "unregelmässig/selten" schwankt zwischen fünf und elf Prozent. Die Segmente "mindestens einmal pro Woche, aber insgesamt weniger als zwei Stunden" und "mindestens einmal pro Woche, insgesamt zwei Stunden und mehr" bleiben über den Zeitraum relativ stabil bei elf bis neun Prozent respektive achtzehn bis neunzehn Prozent.	**SBERT:** 0.85 **LLM as Judge:** *(n=1)* ▪ Clarity: 5 ▪ Completeness: 4 ▪ Conciseness: 1 ▪ PC: 5 ▪ Neutrality: 3 ▪ Correctness: 3
9. Alt text **Short description (metadata):** Senkrecht gestapeltes Balkendiagramm. Titel: Die Zürcher werden immer sportlicher. Untertitel: Sportaktivität, in Prozent. Waagrechte Achse: Zeitreihe: von 2003 bis 2020. Senkrechte Achse: 0 bis 100 Prozent. Segmente pro Balken: nie, unregelmässig/selten, mindestens einmal pro Woche, aber insgesamt weniger als zwei Stunden, mindestens einmal pro Woche, insgesamt zwei Stunden und mehr, mehrmals pro Woche, insgesamt drei Stunden und mehr. **Short description (overview):** Über den Zeitraum von 2003 bis 2020 steigt der Anteil der Zürcher, die mehrmals pro Woche Sport treiben und insgesamt drei Stunden und mehr aufwenden, von 41 Prozent auf 52 Prozent. Parallel dazu verringert sich der Anteil derer, die nie Sport treiben, von 21 Prozent auf 13 Prozent. **Long description:** Der Anteil der Personen, die mehrmals pro Woche drei Stunden und mehr Sport treiben, steigt von 41 Prozent (2003) auf 52 Prozent (2020), unterbrochen von einer Stagnation zwischen 2008 und 2014 bei 46 Prozent. Der Anteil der Nicht-Sportler sinkt von 21 Prozent (2003) auf 13 Prozent (2020). Die Gruppe der unregelmässig/selten Sporttreibenden steigt von 8 Prozent auf 11 Prozent. Die anderen Sport-Kategorien (einmal pro Woche weniger als zwei Stunden und einmal pro Woche zwei Stunden und mehr) zeigen geringere Veränderungen, wobei die erste Kategorie von 11 Prozent auf 5 Prozent sinkt und die zweite Kategorie von 19 Prozent auf 19 Prozent stabil bleibt.	**SBERT:** 0.84 **LLM as Judge:** *(n=1)* ▪ Clarity: 5 ▪ Completeness: 4 ▪ Conciseness: 1 ▪ PC: 5 ▪ Neutrality: 5 ▪ Correctness: 5

10. Alt text	SBERT: 0.79
Short description (metadata): Senkrecht gestapeltes Balkendiagramm. Titel: Die Zürcher werden immer sportlicher. Untertitel: Sportaktivität, in Prozent. Waagrechte Achse: Zeitreihe: 2003 bis 2020 (Intervall: unregelmäßig). Senkrechte Achse: 0 bis 100 Prozent. Segmente pro Balken: 5. **Short description (overview):** Über den Zeitraum von 2003 bis 2020 nimmt der Anteil der Personen zu, die mehrmals pro Woche mindestens drei Stunden Sport treiben. Gleichzeitig sinkt der Anteil der Nicht-Sportler deutlich. **Long description:** Der Anteil der Personen, die nie Sport treiben, sinkt von 21 Prozent im Jahr 2003 auf 13 Prozent im Jahr 2020. Dagegen steigt der Anteil derer, die mehrmals pro Woche insgesamt drei Stunden und mehr Sport treiben, von 41 Prozent auf 52 Prozent. Die Anteile der anderen Kategorien bleiben relativ stabil oder sinken leicht: "mindestens einmal pro Woche, insgesamt zwei Stunden und mehr" liegt um 18 bis 19 Prozent. "Unregelmäßig/selten" und "mindestens einmal pro Woche, aber insgesamt weniger als zwei Stunden" schwanken zwischen 5 und 11 Prozent.	**LLM as Judge:** *(n=1)* ▪ Clarity: 5 ▪ Completeness: 5 ▪ Conciseness: 2 ▪ PC: 5 ▪ Neutrality: 5 ▪ Correctness: 5

016934e7c13b1b546fdea80efd96eba5

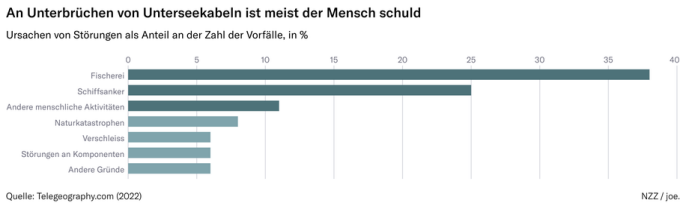

Golden standard

Short description (metadata): Waagrechtes Balkendiagramm. Titel: An Unterbrüchen von Unterseekabeln ist meist der Mensch schuld. Untertitel: Ursachen von Störungen als Anteil an der Zahl der Vorfälle, in %. Waagrechte Achse: 0 bis 40 %. Senkrechte Achse: Fischerei, Schiffsanker, andere menschliche Aktivitäten, Naturkatastrophen, Verschleiss, Störungen an Komponenten, Andere Gründe.

Short description (overview): Rund 70 % der Unterbrüche von Unterseekabeln werden durch Fischerei, Schiffsanker und andere menschliche Aktivitäten verursacht.

Long description: Fischerei verursacht knapp 40 % der Unterbrüche, Schiffsanker 25 % und andere menschliche Aktivitäten rund 10 %. Naturkatastrophen, Verschleiss, Störungen an Komponenten und andere Gründe machen jeweils 6 % aus.

1. Alt text **Short description (metadata):** Waagerechtes Balkendiagramm. Titel: An Unterbrüchen von Unterseekabeln ist meist der Mensch schuld. Untertitel: Ursachen von Störungen als Anteil an der Zahl der Vorfälle, in %. Waagrechte Achse: 0 bis 40 %. Senkrechte Achse: Fischerei, Schiffsanker, Andere menschliche Aktivitäten, Naturkatastrophen, Verschleiss, Störungen an Komponenten, Andere Gründe. **Short description (overview):** Menschliche Aktivitäten, insbesondere Fischerei und Schiffsanker, sind die Hauptursachen für Störungen an Unterseekabeln und machen zwei Drittel aller Vorfälle aus. Der Rest verteilt sich auf Naturkatastrophen, Verschleiss, Komponentenstörungen und andere Gründe. **Long description:** Fischerei ist mit 38 % die häufigste Ursache, gefolgt von Schiffsankern mit 25 % und anderen menschlichen Aktivitäten mit 11 %. Naturkatastrophen machen 8 % aus. Verschleiss, Störungen an Komponenten und andere Gründe liegen jeweils bei 6 %.	**SBERT:** 0.88 **LLM as Judge:** *(n=1)* ▪ Clarity: 5 ▪ Completeness: 5 ▪ Conciseness: 1 ▪ PC: 5 ▪ Neutrality: 3 ▪ Correctness: 3
2. Alt text **Short description (metadata):** Waagerechtes Balkendiagramm. Titel: An Unterbrüchen von Unterseekabeln ist meist der Mensch schuld. Untertitel: Ursachen von Störungen als Anteil an der Zahl der Vorfälle, in %. Waagrechte Achse: 0 bis 40 %. Senkrechte Achse: Fischerei, Schiffsanker, Andere menschliche Aktivitäten, Naturkatastrophen, Verschleiss, Störungen an Komponenten, Andere Gründe. **Short description (overview):** Menschliche Aktivitäten, insbesondere Fischerei und Schiffsanker, sind die dominierenden Ursachen für Störungen von Unterseekabeln. **Long description:** Fischerei ist mit 38 Prozent die häufigste Ursache, gefolgt von Schiffsankern mit 25 Prozent und anderen menschlichen Aktivitäten mit 11 Prozent. Naturkatastrophen verursachen 8 Prozent der Störungen. Verschleiss, Störungen an Komponenten und andere Gründe liegen jeweils bei 6 Prozent.	**SBERT:** 0.87 **LLM as Judge:** *(n=1)* ▪ Clarity: 5 ▪ Completeness: 5 ▪ Conciseness: 1 ▪ PC: 5 ▪ Neutrality: 5 ▪ Correctness: 5
3. Alt text **Short description (metadata):** Waagerechtes Balkendiagramm. Titel: An Unterbrüchen von Unterseekabeln ist meist der Mensch schuld. Untertitel: Ursachen von Störungen als Anteil an der Zahl der Vorfälle, in %. Waagrechte Achse: 0 bis 40 Prozent. Senkrechte Achse: Fischerei, Schiffsanker, Andere menschliche Aktivitäten, Naturkatastrophen, Verschleiss, Störungen an Komponenten, Andere Gründe. **Short description (overview):** Menschliche Aktivitäten, insbesondere Fischerei und Schiffsanker, sind die Hauptursachen für Unterbrüche an Unterseekabeln. **Long description:** Fischerei ist mit 38 Prozent die häufigste Ursache, gefolgt von Schiffsankern mit 25 Prozent. Andere menschliche Aktivitäten verursachen 11 Prozent. Naturkatastrophen sind mit 8 Prozent angegeben. Die Kategorien Verschleiss, Störungen an Komponenten und Andere Gründe liegen jeweils bei 6 Prozent.	**SBERT:** 0.86 **LLM as Judge:** *(n=1)* ▪ Clarity: 5 ▪ Completeness: 5 ▪ Conciseness: 2 ▪ PC: 5 ▪ Neutrality: 5 ▪ Correctness: 5

4. Alt text **Short description (metadata):** Waagerechtes Balkendiagramm. Titel: An Unterbrüchen von Unterseekabeln ist meist der Mensch schuld. Untertitel: Ursachen von Störungen als Anteil an der Zahl der Vorfälle, in %. Waagrechte Achse: 0 bis 40 %. Senkrechte Achse: Fischerei, Schiffsanker, Andere menschliche Aktivitäten, Naturkatastrophen, Verschleiss, Störungen an Komponenten, Andere Gründe. **Short description (overview):** Menschliche Aktivitäten sind mit weitem Abstand die häufigsten Ursachen für Unterbrüche von Unterseekabeln. Fischerei und Schiffsanker machen zusammen fast zwei Drittel aller Störungen aus. **Long description:** Fischerei ist mit 38 Prozent die häufigste Ursache, gefolgt von Schiffsankern mit 25 Prozent. Andere menschliche Aktivitäten liegen bei 11 Prozent. Naturkatastrophen verursachen 8 Prozent der Störungen. Verschleiss, Störungen an Komponenten und Andere Gründe liegen jeweils bei 6 Prozent.	**SBERT:** 0.85 **LLM as Judge:** *(n=1)* ▪ Clarity: 5 ▪ Completeness: 5 ▪ Conciseness: 1 ▪ PC: 5 ▪ Neutrality: 5 ▪ Correctness: 5
5. Alt text **Short description (metadata):** Waagerechtes Balkendiagramm. Titel: An Unterbrüchen von Unterseekabeln ist meist der Mensch schuld. Untertitel: Ursachen von Störungen als Anteil an der Zahl der Vorfälle, in %. Waagrechte Achse: 0 bis 40 Prozent. Senkrechte Achse: Fischerei, Schiffsanker, Andere menschliche Aktivitäten, Naturkatastrophen, Verschleiss, Störungen an Komponenten, Andere Gründe. **Short description (overview):** Die Fischerei ist die bei weitem häufigste Ursache für Störungen von Unterseekabeln, gefolgt von Schiffsankern. Menschliche Aktivitäten sind für den Grossteil der Störungen verantwortlich. **Long description:** Fischerei ist die häufigste Ursache mit 38 Prozent, Schiffsanker folgen mit 25 Prozent. Andere menschliche Aktivitäten verursachen 11 Prozent. Naturkatastrophen sind für 8 Prozent, Verschleiss, Störungen an Komponenten und Andere Gründe jeweils für 6 Prozent der Vorfälle verantwortlich.	**SBERT:** 0.85 **LLM as Judge:** *(n=1)* ▪ Clarity: 5 ▪ Completeness: 5 ▪ Conciseness: 1 ▪ PC: 5 ▪ Neutrality: 3 ▪ Correctness: 5
6. Alt text **Short description (metadata):** Waagrechtes Balkendiagramm. Titel: An Unterbrüchen von Unterseekabeln ist meist der Mensch schuld. Untertitel: Ursachen von Störungen als Anteil an der Zahl der Vorfälle, in Prozent. Waagrechte Achse: 0 bis 40 Prozent. Senkrechte Achse: Fischerei, Schiffsanker, Andere menschliche Aktivitäten, Naturkatastrophen, Verschleiss, Störungen an Komponenten, Andere Gründe. **Short description (overview):** Menschliche Aktivitäten, insbesondere Fischerei und Schiffsanker, sind die weitaus häufigsten Ursachen für Störungen von Unterseekabeln. **Long description:** Fischerei ist mit 38 Prozent die häufigste Ursache, gefolgt von Schiffsankern mit 25 Prozent. Andere menschliche Aktivitäten verursachen 11 Prozent. Naturkatastrophen sind für 8 Prozent verantwortlich. Verschleiss, Störungen an Komponenten und andere Gründe liegen jeweils bei 6 Prozent.	**SBERT:** 0.85 **LLM as Judge:** *(n=1)* ▪ Clarity: 5 ▪ Completeness: 5 ▪ Conciseness: 2 ▪ PC: 5 ▪ Neutrality: 2 ▪ Correctness: 5

7. Alt text **Short description (metadata):** Waagerechtes Balkendiagramm. Titel: An Unterbrüchen von Unterseekabeln ist meist der Mensch schuld. Untertitel: Ursachen von Störungen als Anteil an der Zahl der Vorfälle, in %. Waagrechte Achse: 0 bis 40 Prozent. Senkrechte Achse: Fischerei, Schiffsanker, Andere menschliche Aktivitäten, Naturkatastrophen, Verschleiss, Störungen an Komponenten, Andere Gründe. **Short description (overview):** Die am häufigsten genannten Ursachen für Störungen an Unterseekabeln sind menschlicher Natur: Fischerei (38%) und Schiffsanker (25%). Die Naturkatastrophen (8%), Verschleiss (6%), Störungen an Komponenten (6%) und Andere Gründe (6%) haben eine geringere Relevanz. **Long description:** Fischerei ist mit 38 Prozent die häufigste Ursache, gefolgt von Schiffsankern mit 25 Prozent und anderen menschlichen Aktivitäten mit 11 Prozent. Naturkatastrophen erreichen 8 Prozent, während Verschleiss, Störungen an Komponenten und andere Gründe jeweils 6 Prozent ausmachen.	**SBERT:** 0.84 **LLM as Judge:** *(n=1)* ▪ Clarity: 5 ▪ Completeness: 5 ▪ Conciseness: 1 ▪ PC: 5 ▪ Neutrality: 3 ▪ Correctness: 5
8. Alt text **Short description (metadata):** Waagerechtes Balkendiagramm. Titel: An Unterbrüchen von Unterseekabeln ist meist der Mensch schuld. Untertitel: Ursachen von Störungen als Anteil an der Zahl der Vorfälle, in %. Waagrechte Achse: 0 bis 40 Prozent. Senkrechte Achse: Fischerei, Schiffsanker, Andere menschliche Aktivitäten, Naturkatastrophen, Verschleiss, Störungen an Komponenten, Andere Gründe. **Short description (overview):** Menschliche Aktivitäten (Fischerei, Schiffsanker, andere) sind die häufigsten Ursachen für Störungen an Unterseekabeln und liegen deutlich vor Naturkatastrophen und technischen Ursachen. **Long description:** Die Fischerei ist mit 38 Prozent die häufigste Ursache, gefolgt von Schiffsankern mit 25 Prozent. Andere menschliche Aktivitäten verursachen 11 Prozent. Naturkatastrophen sind für 8 Prozent verantwortlich. Verschleiss, Störungen an Komponenten und andere Gründe liegen jeweils bei 6 Prozent.	**SBERT:** 0.83 **LLM as Judge:** *(n=1)* ▪ Clarity: 5 ▪ Completeness: 5 ▪ Conciseness: 1 ▪ PC: 5 ▪ Neutrality: 5 ▪ Correctness: 4
9. Alt text **Short description (metadata):** Waagerechtes Balkendiagramm. Titel: An Unterbrüchen von Unterseekabeln ist meist der Mensch schuld. Untertitel: Ursachen von Störungen als Anteil an der Zahl der Vorfälle, in %. Waagrechte Achse: 0 bis 40 %. Senkrechte Achse: Fischerei, Schiffsanker, Andere menschliche Aktivitäten, Naturkatastrophen, Verschleiss, Störungen an Komponenten, Andere Gründe. **Short description (overview):** Der dominante Anteil der Störungsursachen wird durch menschliches Handeln verursacht (Fischerei, Schiffsanker, andere menschliche Aktivitäten). **Long description:** Fischerei verursacht mit 38 Prozent den grössten Anteil, gefolgt von Schiffsankern mit 25 Prozent und anderen menschlichen Aktivitäten mit 11 Prozent. Naturkatastrophen sind für 8 Prozent der Störungen verantwortlich. Die Kategorien Verschleiss, Störungen an Komponenten und Andere Gründe betragen jeweils 6 Prozent.	**SBERT:** 0.82 **LLM as Judge:** *(n=1)* ▪ Clarity: 5 ▪ Completeness: 5 ▪ Conciseness: 2 ▪ PC: 5 ▪ Neutrality: 5 ▪ Correctness: 5

10. Alt text	SBERT: 0.8
Short description (metadata): Waagerechtes Balkendiagramm. Titel: An Unterbrüchen von Unterseekabeln ist meist der Mensch schuld. Untertitel: Ursachen von Störungen als Anteil an der Zahl der Vorfälle, in %. Waagrechte Achse: 0 bis 40 Prozent. Senkrechte Achse: Fischerei, Schiffsanker, Andere menschliche Aktivitäten, Naturkatastrophen, Verschleiss, Störungen an Komponenten, Andere Gründe. **Short description (overview):** Die am häufigsten genannten Ursachen für Störungen von Unterseekabeln sind menschlicher Natur (Fischerei, Schiffsanker und andere menschliche Aktivitäten). Fischerei ist mit Abstand der größte Anteil. **Long description:** Fischerei ist mit 38 Prozent die häufigste Ursache, gefolgt von Schiffsanker mit 25 Prozent. Andere menschliche Aktivitäten verursachen 11 Prozent der Störungen. Ursachen wie Naturkatastrophen (8 Prozent), Verschleiss (6 Prozent), Störungen an Komponenten (6 Prozent) und Andere Gründe (6 Prozent) liegen darunter.	**LLM as Judge:** *(n=1)* ▪ Clarity: 5 ▪ Completeness: 5 ▪ Conciseness: 2 ▪ PC: 5 ▪ Neutrality: 3 ▪ Correctness: 5

009b187b6b1fe7ca85fcde3801e0c555

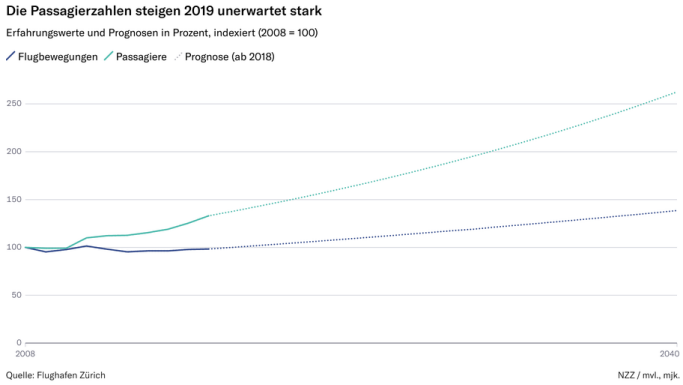

Golden standard

Short description (metadata): Liniendiagramm: Titel: Die Passagierzahlen steigen 2019 unerwartet stark. Untertitel: Erfahrungswerte und Prognosen in Prozent, indexiert (2008 = 100). Waagrechte Achse: Zeitraum 2008 bis 2040. Senkrechte Achse: 0 bis 250. Daten: Jährliche Werte. Zwei Linien: Flugbewegungen (blau), Passagiere (türkis). Ab 2018 gepunktete Linien (Prognosen).

Short description (overview): Die Erfahrungwerte und Prognosen für Flugbewegungen und Passagiere steigen beide, Passagierzahlen stärker.

Long description: Flugbewegungen: Schwanken 2008 bis 2017 zwischen 95 und 102 Punkten. Ab 2018 startet die Prognose bei knapp 100 und steigt danach kontinuierlich auf knapp 140 im Jahr 2040. Passagiere: 2008 bis 2017 Anstieg von 100 auf rund 130. Ab 2018 Prognose von knapp 140 auf gut 260 im Jahr 2040.

1. Alt text **Short description (metadata):** Diagrammtyp: Liniendiagramm. Titel: Die Passagierzahlen steigen 2019 unerwartet stark. Untertitel: Erfahrungswerte und Prognosen in Prozent, indexiert (2008 = 100). Waagerechte Achse: Zeitraum 2008 bis 2040. Senkrechte Achse: Aussschnitt 0 bis 250 in Prozent. Daten: Jährliche Werte. Zwei Linien: Flugbewegungen (Dunkelblau), Passagiere (Türkis), mit Prognose ab 2018. **Short description (overview):** Die Passagierzahlen zeigen von Beginn an eine deutlich stärkere Steigerung als die Flugbewegungen. Während die Flugbewegungen bis 2018 nahezu konstant bleiben und danach langsam steigen, steigen die Passagierzahlen moderat bis 2018 und danach wesentlich schneller in der Prognose. **Long description:** Die Flugbewegungen starten 2008 bei 100 Prozent und bewegen sich bis 2018 nahezu konstant zwischen 95 und 102 Prozent. Ab 2018 steigen die Flugbewegungen langsamer auf prognostizierte etwa 138 Prozent bis 2040. Die Passagierzahlen beginnen ebenfalls bei 100 Prozent im Jahr 2008, steigen bis 2018 auf etwa 137 Prozent und prognostizieren bis 2040 einen steilen Anstieg auf rund 262 Prozent.	**SBERT:** 0.88 **LLM as Judge:** *(n=1)* ▪ Clarity: 5 ▪ Completeness: 5 ▪ Conciseness: 1 ▪ PC: 4 ▪ Neutrality: 2 ▪ Correctness: 5
2. Alt text **Short description (metadata):** Liniendiagramm. Titel: Die Passagierzahlen steigen 2019 unerwartet stark. Untertitel: Erfahrungswerte und Prognosen in Prozent, indexiert (2008 = 100). Waagrechte Achse: Zeitraum 2008 bis 2040. Senkrechte Achse: Ausschnitt 0 bis 250. Daten: Jährliche Werte. Zwei Linien: Flugbewegungen (Dunkelblau), Passagiere (Türkis), mit Prognose ab 2018 (gepunktet). **Short description (overview):** Während die Zahl der Passagiere kontinuierlich und stark steigt, bleiben die Flugbewegungen über den gesamten Zeitraum relativ konstant auf einem niedrigen Niveau. Die Prognosen ab 2018 setzen den jeweiligen Trend fort, wobei die Passagierzahlen bis 2040 deutlich höher prognostiziert werden. **Long description:** Die Flugbewegungen beginnen 2008 bei 100, sinken bis 2009 auf rund 95, schwanken danach bis 2017 zwischen 95 und etwa 101 und bleiben bis 2040 auf niedrigem Niveau, wo sie auf rund 138 steigen. Die Passagierzahlen beginnen ebenfalls bei 100 im Jahr 2008, steigen danach kontinuierlich bis auf rund 133 im Jahr 2017. Die Prognose setzt den starken Anstieg fort bis sie 2040 auf rund 262 steigen.	**SBERT:** 0.88 **LLM as Judge:** *(n=1)* ▪ Clarity: 5 ▪ Completeness: 5 ▪ Conciseness: 1 ▪ PC: 5 ▪ Neutrality: 2 ▪ Correctness: 5

3. Alt text **Short description (metadata):** Liniendiagramm. Titel: Die Passagierzahlen steigen 2019 unerwartet stark. Untertitel: Erfahrungswerte und Prognosen in Prozent, indexiert (2008 = 100). Waagerechte Achse: Zeitraum 2008 bis 2040. Senkrechte Achse: Ausschnitt 0 bis 250 in Prozent. Daten: Jährliche Werte. Zwei Linien: Flugbewegungen (dunkelblau), Passagiere (türkis). Die Prognose ab 2018 ist gepunktet dargestellt. **Short description (overview):** Die Passagierzahlen steigen im Vergleichszeitraum deutlich stärker als die Flugbewegungen. Während die Flugbewegungen fast durchgängig nahe dem Ausgangswert von 100 verbleiben und nur leicht ansteigen, steigen die Passagierzahlen kontinuierlich und erreichen ein wesentlich höheres Niveau. **Long description:** Die Flugbewegungen beginnen bei 100 und schwanken bis 2017 zwischen etwa 95 und 101. Ab 2018 steigt die Prognose sehr moderat, von knapp 100 auf den Endwert von etwa 138 im Jahr 2040. Die Passagierzahlen beginnen ebenfalls bei 100, steigen bis 2017 kontinuierlich auf etwa 133. Die Prognose ab 2018 setzt diesen starken Anstieg fort und endet 2040 bei etwa 262.	**SBERT:** 0.85 **LLM as Judge:** *(n=1)* ▪ Clarity: 5 ▪ Completeness: 4 ▪ Conciseness: 2 ▪ PC: 5 ▪ Neutrality: 2 ▪ Correctness: 5
4. Alt text **Short description (metadata):** Diagrammtyp: Liniendiagramm. Titel: Die Passagierzahlen steigen 2019 unerwartet stark. Untertitel: Erfahrungswerte und Prognosen in Prozent, indexiert (2008 = 100). Waagerechte Achse: Zeitraum 2008 bis 2040. Senkrechte Achse: Ausschnitt 0 bis 250 in Indexpunkten. Daten: Jährliche Werte. Zwei Linien: Flugbewegungen (Dunkelblau), Passagiere (Türkis), mit Prognose ab 2018. **Short description (overview):** Die Passagierzahlen steigen über den gesamten Zeitraum wesentlich stärker als die Flugbewegungen. Während die Flugbewegungen bis 2017 weitgehend stabil auf dem Ausgangsniveau bleiben und danach leicht steigen, weisen die Passagierzahlen von Beginn an einen klar steigenden Trend auf, der sich ab 2018 in der Prognose stark fortsetzt und die Flugbewegungen weit übersteigt. **Long description:** Die Flugbewegungen starten 2008 bei 100 Indexpunkten, sinken zu Beginn leicht und bleiben bis 2017 mit geringen Schwankungen nahe des Ausgangswerts. Von 2018 bis 2040 steigen die prognostizierten Flugbewegungen moderat von etwa 100 auf rund 138 Indexpunkte. Die Passagierzahlen starten ebenfalls bei 100 Indexpunkten, steigen bis 2017 kontinuierlich auf rund 133 Indexpunkte. Ab 2018 steigen die prognostizierten Passagierzahlen deutlich weiter an und erreichen bis 2040 etwa 262 Indexpunkte.	**SBERT:** 0.85 **LLM as Judge:** *(n=1)* ▪ Clarity: 5 ▪ Completeness: 5 ▪ Conciseness: 1 ▪ PC: 5 ▪ Neutrality: 3 ▪ Correctness: 5

5. Alt text **Short description (metadata):** Liniendiagramm. Titel: Die Passagierzahlen steigen 2019 unerwartet stark. Untertitel: Erfahrungswerte und Prognosen in Prozent, indexiert (2008 = 100). Waagrechte Achse: Zeitraum 2008 bis 2040. Senkrechte Achse: Ausschnitt 0 bis 250. Daten: Jährliche Werte. Zwei Linien: Flugbewegungen (Dunkelblau), Passagiere (Türkisgrün). Die Prognose (ab 2018) ist gepunktet dargestellt. **Short description (overview):** Die Passagierzahlen steigen deutlich stärker an als die Anzahl der Flugbewegungen. Während die Flugbewegungen über den gesamten dargestellten Zeitraum nur leicht ansteigen, zeigen die Passagierzahlen einen kontinuierlich starken Anstieg, der sich in der prognostizierten Zeit noch weiter fortsetzt. **Long description:** Die Flugbewegungen beginnen bei 100 im Jahr 2008, sinken bis 2009 auf den niedrigsten Wert, steigen bis 2011 und pendeln sich danach bis 2017 auf einem ähnlichen Niveau ein. Ab der Prognose steigen die Flugbewegungen von etwa 100 leicht und gleichmässig bis 2040 auf etwa 138 an. Die Passagierzahlen verzeichnen von 2008 an einen kontinuierlichen Anstieg, von 100 bis 2018 auf etwa 137. In der Prognose steigen die Passagierzahlen deutlich weiter bis 2040 auf etwa 263 an und liegen damit wesentlich höher als die Flugbewegungen.	**SBERT:** 0.81 **LLM as Judge:** *(n=1)* ▪ Clarity: 5 ▪ Completeness: 5 ▪ Conciseness: 1 ▪ PC: 5 ▪ Neutrality: 1 ▪ Correctness: 5
6. Alt text **Short description (metadata):** Liniendiagramm. Titel: Die Passagierzahlen steigen 2019 unerwartet stark. Untertitel: Erfahrungswerte und Prognosen in Prozent, indexiert (2008 = 100). Waagerechte Achse: Zeitraum 2008 bis 2040. Senkrechte Achse: Ausschnitt 0 bis 250 in Prozent. Daten: Jährliche Werte. Drei Linientypen: Flugbewegungen (dunkelblau), Passagiere (türkis), Prognose (ab 2018; jeweils als gepunktete Linie). **Short description (overview):** Während die Passagierzahlen (türkis) seit 2008 kontinuierlich und stark steigen, bleiben die Flugbewegungen (dunkelblau) fast konstant. Ab 2018 werden für beide Kennzahlen signifikant unterschiedliche Entwicklungen prognostiziert: Die Passagierzahlen werden voraussichtlich weiterhin sehr stark steigen, während die Flugbewegungen konstant leicht ansteigen. **Long description:** Der Index der Flugbewegungen hält sich zwischen 2008 und 2017 auf einem Niveau nahe 100, mit leichten Schwankungen bis etwa 101 im Jahr 2011 und einem Minimum von etwa 95 im Jahr 2009 und 2013. Im Gegensatz dazu steigen die Passagierzahlen von 100 im Jahr 2008 kontinuierlich auf etwa 133 im Jahr 2017. Ab 2018 wird prognostiziert, dass die Passagierzahlen weiterhin stark auf etwa 263 im Jahr 2040 steigen. Die Flugbewegungen werden hingegen nur leicht auf etwa 138 im Jahr 2040 steigen.	**SBERT:** 0.81 **LLM as Judge:** *(n=1)* ▪ Clarity: 5 ▪ Completeness: 5 ▪ Conciseness: 1 ▪ PC: 5 ▪ Neutrality: 2 ▪ Correctness: 5

7. Alt text **Short description (metadata):** Liniendiagramm. Titel: Die Passagierzahlen steigen 2019 unerwartet stark. Untertitel: Erfahrungswerte und Prognosen in Prozent, indexiert (2008 = 100). Waagerechte Achse: Zeitraum 2008 bis 2040. Senkrechte Achse: Ausschnitt 0 bis 250 Indexpunkte. Daten: Jährliche Werte. Zwei Linien mit Prognose ab 2018: Flugbewegungen (dunkelblau), Passagiere (türkis). **Short description (overview):** Während die Zahl der Flugbewegungen über den gesamten Zeitraum nur moderat steigt, zeigt die Zahl der Passagiere einen deutlich stärkeren und kontinuierlichen Anstieg. Die Passagierzahlen steigen insbesondere ab 2011 stärker und entfernen sich von den Flugbewegungen, was auf eine höhere Auslastung schliessen lässt. **Long description:** Die Flugbewegungen beginnen 2008 bei 100 und schwanken bis 2017 zwischen 95 und 102. Ab 2018 steigt die Prognose leicht und kontinuierlich von knapp 100 auf etwa 138 im Jahr 2040. Die Passagierzahlen starten ebenfalls bei 100 im Jahr 2008, steigen bis 2011 auf etwa 110, sinken kurz und zeigen danach einen stetigen Anstieg bis 2017 auf etwa 133. Die Prognose ab 2018 setzt diesen Anstieg fort und erreicht 2040 etwa 262.	**SBERT:** 0.8 **LLM as Judge:** *(n=1)* ▪ Clarity: 3 ▪ Completeness: 5 ▪ Conciseness: 1 ▪ PC: 5 ▪ Neutrality: 3 ▪ Correctness: 2
8. Alt text **Short description (metadata):** Liniendiagramm. Titel: Die Passagierzahlen steigen 2019 unerwartet stark. Untertitel: Erfahrungswerte und Prognosen in Prozent, indexiert (2008 = 100). Waagrechte Achse: Zeitraum 2008 bis 2040. Senkrechte Achse: Ausschnitt 0 bis 250. Daten: Jährliche Werte. Zwei Linien: Flugbewegungen (Dunkelblau), Passagiere (Türkis), mit Prognosen ab 2018 (gepunktet). **Short description (overview):** Während die Zahl der Passagiere über den gesamten Zeitraum stark zunimmt, bleiben die Flugbewegungen bis etwa 2018 auf einem konstanten Niveau um den Ausgangswert von 100, um dann langsam anzusteigen. Die Prognosen zeigen, dass die Passagierzahlen bis 2040 weitaus stärker zunehmen werden als die Flugbewegungen. **Long description:** Die Flugbewegungen beginnen 2008 bei 100, sinken kurz und verbleiben bis 2017 weitgehend zwischen 95 und 98, bevor sie leicht steigen und gemäss Prognose bis 2040 nur langsam auf 138 ansteigen. Die Passagierzahlen beginnen ebenfalls bei 100, steigen jedoch ab 2011 deutlich an und erreichen 2017 den Wert von 133. Die Prognose zeigt für die Passagierzahlen einen kontinuierlichen, steilen Anstieg auf über 262 bis 2040.	**SBERT:** 0.79 **LLM as Judge:** *(n=1)* ▪ Clarity: 5 ▪ Completeness: 5 ▪ Conciseness: 1 ▪ PC: 5 ▪ Neutrality: 1 ▪ Correctness: 3

9. Alt text **Short description (metadata):** Liniendiagramm. Titel: Die Passagierzahlen steigen 2019 unerwartet stark. Untertitel: Erfahrungswerte und Prognosen in Prozent, indexiert (2008 = 100). Waagerechte Achse: Zeitraum 2008 bis 2040. Senkrechte Achse: Ausschnitt 0 bis 250 in Prozent. Daten: Jährliche Werte. Zwei Linien: Flugbewegungen (dunkelblau) und Passagiere (türkis), ab 2018 jeweils als gepunktete Linie dargestellt (Prognose). **Short description (overview):** Die Entwicklung der Passagierzahlen steigt signifikant stärker an als die der Flugbewegungen. Während die Passagierzahlen von 2008 bis 2040 voraussichtlich um mehr als das 2,5-fache steigen, bleiben die Flugbewegungen über den gesamten Zeitraum relativ stabil, mit nur einem leichten Anstieg gegen Ende der Prognose. **Long description:** Die Flugbewegungen beginnen bei 100 Prozent und schwanken bis 2018 zwischen 95 und 102 Prozent. Die Prognose zeigt bis 2040 einen langsamen, stetigen Anstieg auf rund 138 Prozent. Die Passagierzahlen beginnen ebenfalls bei 100 Prozent, steigen bis 2018 jedoch kontinuierlich auf etwa 137 Prozent. Die Prognose zeigt einen exponentiell wirkenden Anstieg von 2018 bis 2040 auf schätzungsweise 262 Prozent.	**SBERT:** 0.78 **LLM as Judge:** *(n=1)* ▪ Clarity: 5 ▪ Completeness: 5 ▪ Conciseness: 1 ▪ PC: 4 ▪ Neutrality: 2 ▪ Correctness: 3
10. Alt text **Short description (metadata):** Liniendiagramm. Titel: Die Passagierzahlen steigen 2019 unerwartet stark. Untertitel: Erfahrungswerte und Prognosen in Prozent, indexiert (2008 = 100). Waagerechte Achse: Zeitraum 2008 bis 2040. Senkrechte Achse: Ausschnitt 0 bis 250 in Prozent. Daten: Jährliche Werte. Drei Linien: Flugbewegungen (dunkelblau), Passagiere (türkis), Prognose (ab 2018) (gepunktet). **Short description (overview):** Die Passagierzahlen steigen über den gesamten Zeitraum sehr viel stärker an als die Anzahl der Flugbewegungen. Während die Flugbewegungen nur moderat zunehmen, verdoppeln sich die Passagierzahlen bis zum Ende des dargestellten Zeitraums mehr als. **Long description:** Die Flugbewegungen beginnen bei 100 Prozent, sinken kurzzeitig, bleiben bis etwa 2017 auf einem Niveau zwischen 95 und 99 Prozent, bevor sie leicht auf rund 101 Prozent im Jahr 2019 steigen. Die Prognose zeigt eine weiterhin moderate Zunahme bis 2040 auf etwa 138 Prozent. Die Passagierzahlen starten bei 100 Prozent, steigen kontinuierlich und erreichen 2019 rund 141 Prozent. Die Prognose zeigt einen deutlichen Anstieg auf rund 262 Prozent im Jahr 2040.	**SBERT:** 0.72 **LLM as Judge:** *(n=1)* ▪ Clarity: 5 ▪ Completeness: 5 ▪ Conciseness: 1 ▪ PC: 5 ▪ Neutrality: 1 ▪ Correctness: 3

0313da61de86779a1c0b46f571670e55

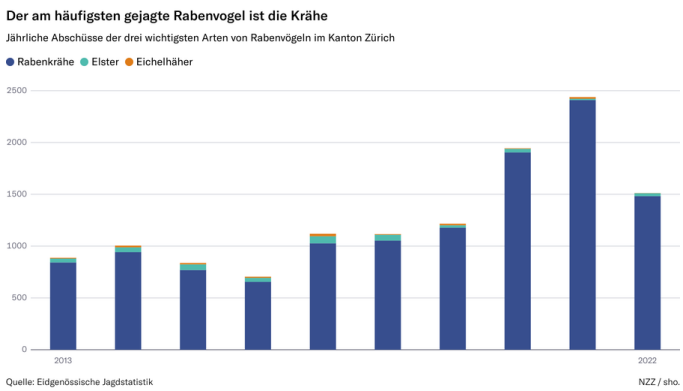

Golden standard

Short description (metadata): Senkrechtes Balkendiagramm. Titel: Der am häufigsten gejagte Rabenvogel ist die Krähe. Untertitel: Jährliche Abschüsse der drei wichtigsten Rabenvogelarten im Kanton Zürich. Waagrechte Achse: Jahre 2013 bis 2022. Senkrechte Achse: 0 bis 2500 Abschüsse. Pro Jahr ein Balken unterteilt in drei Anteile: Rabenkrähe (dunkelblau), Elster (türkis), Eichelhäher (orange).

Short description (overview): Nach einem Anstieg bis 2021 ging die Gesamtzahl 2022 auf etwa 1'500 zurück. Die Rabenkrähe stellt mit über 90 % in allen Jahren den grössten Anteil der Abschüsse.

Long description: Anzahl Abschüsse pro Jahr: 2013 bis 2016 etwa 650 bis 950; 2017 bis 2019 etwa 1'000 bis 1'200; 2020 Anstieg auf rund 1'900; 2021 Höchstwert mit rund 2'400; 2022 Rückgang auf etwa 1'500. Anteile nach Art: Rabenkrähe 94 bis 99 %, Elster 1 bis 7 %, Eichelhäher meist unter 2 %.

1. Alt text **Short description (metadata):** Senkrecht gestapeltes Balkendiagramm. Titel: Der am häufigsten gejagte Rabenvogel ist die Krähe. Untertitel: Jährliche Abschüsse der drei wichtigsten Arten von Rabenvögeln im Kanton Zürich. Waagrechte Achse: Zeitreihe 2013 bis 2022. Senkrechte Achse: Null bis 2 500 [Abschüsse]. Segmente pro Balken: Rabenkrähe (dunkelblau), Elster (türkis), Eichelhäher (orange). **Short description (overview):** Die Gesamtzahl der Abschüsse schwankt stark zwischen etwa 700 (2016) und 2 450 (2021). Die Rabenkrähe stellt in jedem Jahr das mit Abstand dominierende Segment dar. **Long description:** Die Gesamtzahl der Abschüsse liegt 2013 bei etwa 890, steigt bis 2014 auf knapp 1 000, sinkt bis 2016 auf circa 700 und steigt bis 2021 auf den Höchststand von rund 2 440, bevor sie 2022 auf etwa 1 510 sinkt. Die Rabenkrähe macht den grössten Anteil aus und spiegelt die Gesamtentwicklung wider. Elster und Eichelhäher liegen konstant im niedrigen zweistelligen Bereich und haben einen vernachlässigbaren Einfluss auf die Gesamtentwicklung.	**SBERT:** 0.88 **LLM as Judge:** *(n=1)* ▪ Clarity: 5 ▪ Completeness: 5 ▪ Conciseness: 1 ▪ PC: 5 ▪ Neutrality: 5 ▪ Correctness: 4
2. Alt text **Short description (metadata):** Senkrecht gestapeltes Balkendiagramm. Titel: Der am häufigsten gejagte Rabenvogel ist die Krähe. Untertitel: Jährliche Abschüsse der drei wichtigsten Arten von Rabenvögeln im Kanton Zürich. Waagrechte Achse: Zeitreihe von 2013 bis 2022. Senkrechte Achse: Null bis 2500. Segmente pro Balken: Rabenkrähe (dunkelblau), Elster (türkis), Eichelhäher (orange). **Short description (overview):** Die Gesamtzahl der Abschüsse schwankt stark, zeigt aber über den Zeitraum 2013 bis 2021 einen deutlichen Anstieg mit einem Peak im Jahr 2021. Die Rabenkrähe dominiert durchgehend mit dem weitaus grössten Anteil an den Abschüssen. **Long description:** Die Gesamtabschüsse steigen von 887 im Jahr 2013 auf einen Höchststand von 2438 im Jahr 2021, bevor sie 2022 auf 1512 sinken. Die Rabenkrähe ist in allen Jahren das klar führende Segment, ihr Anteil variiert zwischen 90 und 98 Prozent. Elster und Eichelhäher machen konstant nur kleine Anteile der gesamten Abschüsse aus.	**SBERT:** 0.87 **LLM as Judge:** *(n=1)* ▪ Clarity: 5 ▪ Completeness: 4 ▪ Conciseness: 1 ▪ PC: 5 ▪ Neutrality: 5 ▪ Correctness: 5

3. Alt text **Short description (metadata):** Senkrechtes gestapeltes Balkendiagramm. Titel: Der am häufigsten gejagte Rabenvogel ist die Krähe. Untertitel: Jährliche Abschüsse der drei wichtigsten Arten von Rabenvögeln im Kanton Zürich. Waagrechte Achse: Zeitreihe von 2013 bis 2022 (jährlich). Senkrechte Achse: 0 bis 2500. Segmente pro Balken: Rabenkrähe (dunkelblau), Elster (türkis), Eichelhäher (orange). **Short description (overview):** Die Gesamtzahl der Abschüsse zeigt von 2013 bis 2021 einen deutlichen Anstieg mit einem Höhepunkt in 2021 (über 2400). Die Rabenkrähe dominiert durchgehend die Abschusszahlen, während Elster und Eichelhäher nur geringe Anteile ausmachen. **Long description:** Die Gesamtabschüsse steigen von rund 880 im Jahr 2013 auf ein Spitzenjahr 2021 mit über 2400 Abschüssen, gefolgt von einem Rückgang auf etwa 1512 im Jahr 2022. Die Rabenkrähe ist das Leitsegment, deren Abschüsse von 842 (2013) auf 2409 (2021) steigen, dann auf 1482 sinken. Die Anteile der Elster schwanken zwischen 13 und 68 Abschüssen, wobei der höchste Wert 2017 erreicht wird. Der Eichelhäher bildet mit maximal 24 Abschüssen (2017) das kleinste Segment.	**SBERT:** 0.86 **LLM as Judge:** *(n=1)* ▪ Clarity: 5 ▪ Completeness: 5 ▪ Conciseness: 1 ▪ PC: 5 ▪ Neutrality: 3 ▪ Correctness: 5
4. Alt text **Short description (metadata):** Senkrecht gestapeltes Balkendiagramm. Titel: Der am häufigsten gejagte Rabenvogel ist die Krähe. Untertitel: Jährliche Abschüsse der drei wichtigsten Arten von Rabenvögeln im Kanton Zürich. Waagrechte Achse: Zeitreihe von 2013 bis 2022. Senkrechte Achse: Null bis 2500. Segmente pro Balken: Rabenkrähe (dunkelblau), Elster (türkis), Eichelhäher (orange). **Short description (overview):** Die Gesamtzahl der Abschüsse der drei Rabenvögel zeigt von 2013 bis 2021 einen starken Anstieg, mit einem Höchstwert in 2021 und einem markanten Rückgang in 2022. Die Rabenkrähe dominiert durchgehend und macht den grössten Anteil der Abschüsse aus. **Long description:** Die Gesamtzahl der Abschüsse steigt von 887 in 2013 auf den Spitzenwert von 2438 in 2021, bevor sie in 2022 auf 1512 sinkt. Die Rabenkrähe ist das grösste Segment und steigt von 842 in 2013 auf einen Peak von 2409 in 2021. Elster und Eichelhäher machen nur einen sehr kleinen, variierenden Anteil aus, wobei der höchste Wert der Elster bei 68 in 2017 und beim Eichelhäher bei 24 in 2017 liegt. Die niedrigste Zahl für die Rabenkrähe ist 655 in 2016.	**SBERT:** 0.86 **LLM as Judge:** *(n=1)* ▪ Clarity: 5 ▪ Completeness: 5 ▪ Conciseness: 1 ▪ PC: 5 ▪ Neutrality: 3 ▪ Correctness: 5

5. Alt text **Short description (metadata):** Senkrecht gestapeltes Balkendiagramm. Titel: Der am häufigsten gejagte Rabenvogel ist die Krähe. Untertitel: Jährliche Abschüsse der drei wichtigsten Arten von Rabenvögeln im Kanton Zürich. Waagrechte Achse: Zeitreihe von 2013 bis 2022. Senkrechte Achse: Null bis 2500. Segmente pro Balken: Rabenkrähe (dunkelblau), Elster (türkis), Eichelhäher (orange). **Short description (overview):** Die Gesamtzahl der Abschüsse schwankt zwischen etwa 700 und 2450 pro Jahr, mit einem starken Anstieg von 2016 bis 2021 und einem Rückgang im Jahr 2022. Die Rabenkrähe dominiert konstant alle Jahre und macht stets den grössten Anteil aus. **Long description:** Die Gesamtabschüsse starten 2013 bei 887, sinken bis 2016 auf 705, steigen anschliessend signifikant bis zum Höchstwert von 2438 im Jahr 2021 und sinken 2022 auf 1512. Die Rabenkrähe ist das Leitsegment, wobei die Abschüsse 2021 (2409) am höchsten sind. Elster und Eichelhäher sind die Sekundärsegmente, deren Anteile im Vergleich zur Rabenkrähe meist gering sind und über die Jahre schwanken.	**SBERT:** 0.86 **LLM as Judge:** *(n=1)* ▪ Clarity: 5 ▪ Completeness: 5 ▪ Conciseness: 1 ▪ PC: 5 ▪ Neutrality: 5 ▪ Correctness: 5
6. Alt text **Short description (metadata):** Senkrecht gestapeltes Balkendiagramm. Titel: Der am häufigsten gejagte Rabenvogel ist die Krähe. Untertitel: Jährliche Abschüsse der drei wichtigsten Arten von Rabenvögeln im Kanton Zürich. Waagrechte Achse: Zeitreihe von 2013 bis 2022. Senkrechte Achse: Null bis 2500. Segmente pro Balken: Rabenkrähe (dunkelblau), Elster (türkis), Eichelhäher (orange). **Short description (overview):** Die Gesamtzahl der Abschüsse schwankt zwischen 650 und 2500, mit einem starken Anstieg von 2017 bis 2021 (Peak) und einem Rückgang im letzten Jahr. Die Rabenkrähe dominiert durchgehend alle Jahre mit Abstand. **Long description:** Die Gesamtzahl der Abschüsse stieg von rund 880 im Jahr 2013 auf einen Höchstwert von etwa 2440 im Jahr 2021, fiel aber 2022 auf rund 1510. Vor 2017 war das Niveau stabil zwischen 650 und 1000. Die Rabenkrähe stellt das Gros der Abschüsse, mit Tiefstwerten von 655 (2016) und einem Peak von 2409 (2021). Elster und Eichelhäher machen nur einen minimalen Anteil der Gesamtabschüsse aus, wobei die Elster leicht dominanter ist als der Eichelhäher.	**SBERT:** 0.85 **LLM as Judge:** *(n=1)* ▪ Clarity: 5 ▪ Completeness: 5 ▪ Conciseness: 1 ▪ PC: 5 ▪ Neutrality: 3 ▪ Correctness: 4
7. Alt text **Short description (metadata):** Senkrechtes gestapeltes Balkendiagramm. Titel: Der am häufigsten gejagte Rabenvogel ist die Krähe. Untertitel: Jährliche Abschüsse der drei wichtigsten Arten von Rabenvögeln im Kanton Zürich. Waagrechte Achse: 2013 bis 2022. Senkrechte Achse: null bis 2500. Segmente pro Balken: Rabenkrähe (dunkelblau), Elster (türkis), Eichelhäher (orange). **Short description (overview):** Die Gesamtzahl der Abschüsse schwankt stark, zeigt aber über den Zeitraum von 2013 bis 2021 einen deutlichen Anstieg mit einem Spitzenwert im Jahr 2021, gefolgt von einem Rückgang im Jahr 2022. Das Segment Rabenkrähe dominiert durchgehend die Abschüsse. **Long description:** Die Gesamtzahl der Abschüsse stieg von rund 887 im Jahr 2013 auf einen Höchstwert von 2438 im Jahr 2021, bevor sie 2022 auf 1512 sank. Die Rabenkrähe stellt das dominierende Segment dar, ihr Anteil liegt stets über 90 Prozent der Gesamtmenge. Die Elster (meist 25 bis 68 Abschüsse) und der Eichelhäher (meist 2 bis 24 Abschüsse) bilden nur geringfügige Anteile der gesamten Jagdstrecke.	**SBERT:** 0.85 **LLM as Judge:** *(n=1)* ▪ Clarity: 5 ▪ Completeness: 4 ▪ Conciseness: 2 ▪ PC: 5 ▪ Neutrality: 3 ▪ Correctness: 4

8. Alt text **Short description (metadata):** Senkrecht gestapeltes Balkendiagramm. Titel: Der am häufigsten gejagte Rabenvogel ist die Krähe. Untertitel: Jährliche Abschüsse der drei wichtigsten Arten von Rabenvögeln im Kanton Zürich. Waagrechte Achse: Zeitreihe 2013 bis 2022. Senkrechte Achse: Null bis 2500. Segmente pro Balken: Rabenkrähe (dunkelblau), Elster (türkis), Eichelhäher (orange). **Short description (overview):** Die Gesamtzahl der jährlichen Abschüsse schwankt stark, mit einem Anstieg von etwa 890 (2013) auf einen Spitzenwert von 2438 (2021), gefolgt von einem Rückgang auf 1512 im Jahr 2022. Die Abschüsse der Rabenkrähe dominieren eindeutig die Gesamtzahl und zeigen die stärksten Schwankungen. **Long description:** Die Gesamtzahl der Abschüsse liegt 2013 bei etwa 890, sinkt bis 2016 auf einen Tiefwert von 705, steigt dann kontinuierlich bis zum Spitzenjahr 2021 mit 2438 und sinkt 2022 wieder auf 1512. Die Rabenkrähe stellt durchgehend das dominierende Segment mit einem Anteil von über neunzig Prozent, ihre Zahlenentwicklung bestimmt den Verlauf des Gesamtwertes. Die Abschüsse von Elster und Eichelhäher liegen konstant im unteren Bereich von meist unter je siebzig Abschüssen pro Jahr.	**SBERT:** 0.84 **LLM as Judge:** *(n=1)* ▪ Clarity: 5 ▪ Completeness: 5 ▪ Conciseness: 1 ▪ PC: 5 ▪ Neutrality: 3 ▪ Correctness: 4
9. Alt text **Short description (metadata):** Senkrechtes gestapeltes Balkendiagramm. Titel: Der am häufigsten gejagte Rabenvogel ist die Krähe. Untertitel: Jährliche Abschüsse der drei wichtigsten Arten von Rabenvögeln im Kanton Zürich. Waagrechte Achse: Zeitreihe von 2013 bis 2022. Senkrechte Achse: 0 bis 2500. Segmente pro Balken: Rabenkrähe (dunkelblau), Elster (türkis), Eichelhäher (orange). **Short description (overview):** Die Gesamtzahl der Abschüsse schwankt zwischen etwa 700 und 2400 pro Jahr, mit einem deutlichen Höchstwert im Jahr 2021. Die Rabenkrähe dominiert konstant alle Jahre mit über 90 Prozent der gejagten Vögel und bestimmt massgeblich die Entwicklung. **Long description:** Die Gesamtabschusszahl verzeichnete von 2013 (887) bis 2016 (705) einen leichten Rückgang, stieg dann kontinuierlich bis zum Höchstwert 2021 (2438) an und sank 2022 wieder (1512). Die Rabenkrähe macht stets den grössten Anteil aus und bildet den Haupttrend ab. Die Anteile von Elster und Eichelhäher sind marginal und bleiben jeweils unter 100 Abschüssen pro Jahr, mit geringen Schwankungen ohne klare Tendenz.	**SBERT:** 0.83 **LLM as Judge:** *(n=1)* ▪ Clarity: 5 ▪ Completeness: 5 ▪ Conciseness: 2 ▪ PC: 5 ▪ Neutrality: 5 ▪ Correctness: 5

10. Alt text	SBERT: 0.81
Short description (metadata): Senkrechtes gestapeltes Balkendiagramm. Titel: Der am häufigsten gejagte Rabenvogel ist die Krähe. Untertitel: Jährliche Abschüsse der drei wichtigsten Arten von Rabenvögeln im Kanton Zürich. Waagrechte Achse: Zeitreihe von 2013 bis 2022 (jährlich). Senkrechte Achse: Null bis 2500. Segmente pro Balken: Rabenkrähe (dunkelblau), Elster (türkis), Eichelhäher (orange). **Short description (overview):** Die Gesamtzahl der Abschüsse schwankt zwischen 650 und fast 2450. Die Rabenkrähe dominiert konstant alle Jahre mit weitem Abstand. Die Elster und der Eichelhäher machen nur einen sehr kleinen, nahezu konstanten Anteil aus. **Long description:** Die Gesamtzahl der Abschüsse war 2013 etwa 890 und sinkt bis 2016 auf circa 700. Anschliessend steigt die Zahl bis zum Spitzenwert von 2450 im Jahr 2021, gefolgt von einem Rückgang auf rund 1510 im Jahr 2022. Die Rabenkrähe ist das grösste Segment mit über 90 Prozent der gesamten Abschüsse, von 842 (2013) bis 2409 (2021). Die Elster und der Eichelhäher machen zusammen in allen Jahren nicht mehr als zehn Prozent aus, die Elster mehr als der Eichelhäher.	**LLM as Judge:** *(n=1)* ▪ Clarity: 5 ▪ Completeness: 2 ▪ Conciseness: 1 ▪ PC: 5 ▪ Neutrality: 3 ▪ Correctness: 3

0819c8effbf081938ef522a36994376d

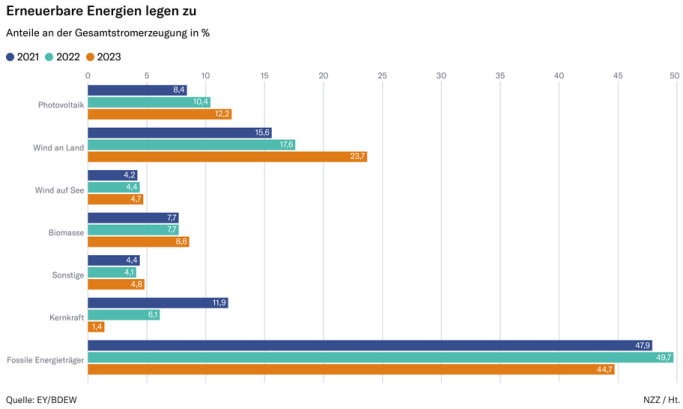

Golden standard

Short description (metadata): Waagrechtes Balkendiagramm. Titel: Erneuerbare Energien legen zu. Untertitel: Anteile an der Gesamtstromerzeugung in %. Waagrechte Achse: 0 bis 50 %. Senkrechte Achse: Photovoltaik, Wind an Land, Wind auf See, Biomasse, Sonstige, Kernkraft und fossile Energieträger. Pro Energiequelle drei Balken: 2021 (blau), 2022 (türkis), 2023 (orange).

Short description (overview): Die Anteile von Kernkraft und fossilen Energieträgern sinken, diejenigen aller anderen Energiequellen steigen. Der Anteil fossiler Energieträger an der Gesamtstromerzeugung ist der grösste Anteil (knapp 45 bis 50%) in allen drei Jahren.

Long description: Zwischen 2021 und 2023 sinkt der Anteil fossiler Energieträger an der Stromerzeugung von knapp 50 % auf 45 %, während die Kernkraft im selben Zeitraum von etwa 12% auf 1 % sinkt. Gleichzeitig steigt der Anteil von Windenergie an Land deutlich von rund 15 % auf fast 25 % und der Anteil der Photovoltaik von etwa 8 % auf 12%. Auch Biomasse (von 8 % auf 9 %), Wind auf See (von 4 % auf 5%) und sonstige erneuerbare Quellen (von 4,5 % auf 5 %) steigen leicht.

1. Alt text **Short description (metadata):** Waagerechtes Balkendiagramm. Titel: Erneuerbare Energien legen zu. Untertitel: Anteile an der Gesamtstromerzeugung in %. Waagrechte Achse: 0 bis 50 Prozent. Senkrechte Achse: Photovoltaik, Wind an Land, Wind auf See, Biomasse, Sonstige, Kernkraft, Fossile Energieträger. Drei Balken pro Energieträger: 2021 (dunkelblau), 2022 (türkis), 2023 (orange). **Short description (overview):** Bei den erneuerbaren Energieträgern steigen die Anteile an der Gesamtstromerzeugung von 2021 bis 2023 deutlich, während der Anteil der Kernkraft stark sinkt. Der Anteil an fossilen Energieträgern ist in allen drei Jahren am höchsten. **Long description:** Der Anteil von Wind an Land steigt von 15,6 auf 23,7 Prozent, Photovoltaik von 8,4 auf 12,2 Prozent und Biomasse von 7,7 auf 8,6 Prozent. Der Anteil der Kernkraft sinkt stark von 11,9 auf 1,4 Prozent. Die fossilen Energieträger liegen bei 47,9 Prozent im Jahr 2021, steigen auf 49,7 Prozent im Jahr 2022 und sinken auf 44,7 Prozent im Jahr 2023.	**SBERT:** 0.88 **LLM as Judge:** *(n=1)* ▪ Clarity: 4 ▪ Completeness: 2 ▪ Conciseness: 1 ▪ PC: 5 ▪ Neutrality: 4 ▪ Correctness: 5
2. Alt text **Short description (metadata):** Waagrechtes Balkendiagramm. Titel: Erneuerbare Energien legen zu. Untertitel: Anteile an der Gesamtstromerzeugung in %. Waagrechte Achse: 0 bis 50 Prozent. Senkrechte Achse: Photovoltaik, Wind an Land, Wind auf See, Biomasse, Sonstige, Kernkraft, Fossile Energieträger. Drei Balken pro Energieträger: 2021 (blau), 2022 (türkis), 2023 (orange). **Short description (overview):** Während die Anteile der Erneuerbaren Energien und der Biomasse an der Gesamtstromerzeugung insgesamt steigen, ist ein starker Rückgang des Anteils der Kernkraft zu verzeichnen. Fossile Energieträger spielen weiterhin die grösste Rolle, wobei ihr Anteil 2023 leicht gesunken ist. **Long description:** Der Anteil von Wind an Land ist von 15,6 Prozent im Jahr 2021 auf 23,7 Prozent im Jahr 2023 gestiegen und der von Photovoltaik von 8,4 auf 12,2 Prozent gestiegen. Der Anteil der Kernkraft ist stark von 11,9 Prozent auf 1,4 Prozent gesunken. Der Anteil fossiler Energieträger lag 2021 bei 47,9 Prozent, stieg 2022 auf 49,7 Prozent und ist im Jahr 2023 auf 44,7 Prozent gesunken.	**SBERT:** 0.86 **LLM as Judge:** *(n=1)* ▪ Clarity: 4 ▪ Completeness: 3 ▪ Conciseness: 2 ▪ PC: 5 ▪ Neutrality: 3 ▪ Correctness: 5
3. Alt text **Short description (metadata):** Waagerechtes Balkendiagramm. Titel: Erneuerbare Energien legen zu. Untertitel: Anteile an der Gesamtstromerzeugung in %. Waagrechte Achse: 0 bis 50 Prozent. Senkrechte Achse: Photovoltaik, Wind an Land, Wind auf See, Biomasse, Sonstige, Kernkraft, Fossile Energieträger. Drei Balken pro E-Träger: 2021 (dunkelblau), 2022 (türkis), 2023 (orange). **Short description (overview):** Während die Anteile der erneuerbaren Energieträger an der Gesamtstromerzeugung insgesamt steigen, sinkt der Anteil fossiler Energieträger im Jahr 2023 im Vergleich zu 2022. **Long description:** Der Anteil von Wind an Land steigt am stärksten von 15,6 Prozent in 2021 auf 23,7 Prozent in 2023. Der Anteil von Photovoltaik steigt von 8,4 auf 12,2 Prozent. Kernkraft sinkt stark von 11,9 auf 1,4 Prozent. Fossile Energieträger sinken im Jahr 2023 leicht auf 44,7 Prozent, nach einem Anstieg von 47,9 Prozent in 2021 auf 49,7 Prozent in 2022.	**SBERT:** 0.85 **LLM as Judge:** *(n=1)* ▪ Clarity: 5 ▪ Completeness: 3 ▪ Conciseness: 2 ▪ PC: 5 ▪ Neutrality: 5 ▪ Correctness: 5

4. Alt text **Short description (metadata):** Waagerechtes Balkendiagramm. Titel: Erneuerbare Energien legen zu. Untertitel: Anteile an der Gesamtstromerzeugung in %. Waagrechte Achse: Null bis 50 Prozent. Senkrechte Achse: Photovoltaik, Wind an Land, Wind auf See, Biomasse, Sonstige, Kernkraft und Fossile Energieträger. Drei Balken pro Energieträger: 2021 (dunkelblau), 2022 (türkis), 2023 (orange). **Short description (overview):** Während die Anteile der Erneuerbaren Energieträger insgesamt in den Jahren 2021 bis 2023 größtenteils steigen, sinkt der Anteil der Kernkraft stark. Der Anteil der fossilen Energieträger bewegt sich in den drei Jahren relativ stabil um die 47 Prozent. **Long description:** Der Anteil von Photovoltaik steigt von 8,4 auf 12,2 Prozent. Der Anteil von Wind an Land steigt stark von 15,6 auf 23,7 Prozent. Wind auf See steigt von 4,2 auf 4,7 Prozent, und Biomasse von 7,7 auf 8,6 Prozent. Der Anteil von Kernkraft sinkt stark von 11,9 auf 1,4 Prozent. Die fossilen Energieträger bewegen sich zwischen 44,7 und 49,7 Prozent.	**SBERT:** 0.83 **LLM as Judge:** *(n=1)* ▪ Clarity: 5 ▪ Completeness: 3 ▪ Conciseness: 1 ▪ PC: 5 ▪ Neutrality: 3 ▪ Correctness: 5
5. Alt text **Short description (metadata):** Waagerechtes Balkendiagramm. Titel: Erneuerbare Energien legen zu. Untertitel: Anteile an der Gesamtstromerzeugung in Prozent. Waagrechte Achse: 0 bis 50 Prozent. Senkrechte Achse: Photovoltaik, Wind an Land, Wind auf See, Biomasse, Sonstige, Kernkraft und Fossile Energieträger. Drei Balken pro Energieträger: 2021 (dunkelblau), 2022 (türkis), 2023 (orange). **Short description (overview):** Während in den Jahren 2021 bis 2023 der Anteil erneuerbarer Energien an der Stromerzeugung deutlich steigt, sinkt der Anteil von Kernkraft drastisch und der Anteil fossiler Energieträger schwankt um die 47 Prozent. **Long description:** Der Anteil von Wind an Land steigt am stärksten von 15,6 auf 23,7 Prozent, gefolgt von Photovoltaik von 8,4 auf 12,2 Prozent. Der Anteil von Wind auf See und Biomasse steigt leicht auf 4,7 beziehungsweise 8,6 Prozent. Kernkraft sinkt drastisch von 11,9 auf 1,4 Prozent. Fossile Energieträger sinken im Betrachtungszeitraum von 47,9 auf 44,7 Prozent, mit einem Höchststand von 49,7 Prozent im Jahr 2022.	**SBERT:** 0.83 **LLM as Judge:** *(n=1)* ▪ Clarity: 5 ▪ Completeness: 4 ▪ Conciseness: 2 ▪ PC: 5 ▪ Neutrality: 3 ▪ Correctness: 5
6. Alt text **Short description (metadata):** Waagerechtes Balkendiagramm. Titel: Erneuerbare Energien legen zu. Untertitel: Anteile an der Gesamtstromerzeugung in Prozent. Waagrechte Achse: 0 bis 50 Prozent. Senkrechte Achse: Photovoltaik, Wind an Land, Wind auf See, Biomasse, Sonstige, Kernkraft und Fossile Energieträger. Drei Balken pro Energieträger: 2021 (blau), 2022 (türkis), 2023 (orange). **Short description (overview):** Während die Anteile der erneuerbaren Energieträger an der Gesamtstromerzeugung in den Jahren 2021 bis 2023 fast durchweg gestiegen sind, ist der Anteil der Kernkraft stark gesunken und der Anteil fossiler Energieträger auf ähnlichem Niveau geblieben. **Long description:** Der Anteil von Wind an Land ist von 15,6 auf 23,7 Prozent gestiegen, und der Photovoltaik-Anteil von 8,4 auf 12,2 Prozent. Der Anteil fossiler Energieträger bewegt sich dabei um 47 Prozent. Der Anteil der Kernkraft ist von 11,9 auf 1,4 Prozent gesunken.	**SBERT:** 0.82 **LLM as Judge:** *(n=1)* ▪ Clarity: 5 ▪ Completeness: 3 ▪ Conciseness: 1 ▪ PC: 5 ▪ Neutrality: 5 ▪ Correctness: 4

7. Alt text **Short description (metadata):** Waagrechtes Balkendiagramm. Titel: Erneuerbare Energien legen zu. Untertitel: Anteile an der Gesamtstromerzeugung in %. Waagrechte Achse: 0 bis 50 Prozent. Senkrechte Achse: Photovoltaik, Wind an Land, Wind auf See, Biomasse, Sonstige, Kernkraft, Fossile Energieträger. Drei Balken pro Energieträger: 2021 (dunkelblau), 2022 (türkis), 2023 (orange). **Short description (overview):** Während die Anteile der Erneuerbaren Energien und der Windenergie an Land besonders stark steigen, sinken die Beiträge der Kernkraft und der fossilen Energieträger deutlich. **Long description:** Der Beitrag von Wind an Land steigt von 15,6 im Jahr 2021 auf 23,7 Prozent im Jahr 2023, und der der Photovoltaik von 8,4 auf 12,2 Prozent. Kernkraft sinkt von 11,9 auf 1,4 Prozent, und fossile Energieträger von 47,9 auf 44,7 Prozent. Der Anteil von Wind auf See steigt leicht von 4,2 auf 4,7 Prozent, Biomasse von 7,7 auf 8,6 Prozent, und Sonstige von 4,4 auf 4,8 Prozent.	**SBERT:** 0.8 **LLM as Judge:** *(n=1)* ▪ Clarity: 4 ▪ Completeness: 5 ▪ Conciseness: 2 ▪ PC: 5 ▪ Neutrality: 3 ▪ Correctness: 4
8. Alt text **Short description (metadata):** Waagerechtes Balkendiagramm. Titel: Erneuerbare Energien legen zu. Untertitel: Anteile an der Gesamtstromerzeugung in Prozent. Waagrechte Achse: 0 bis 50 Prozent. Senkrechte Achse: Photovoltaik, Wind an Land, Wind auf See, Biomasse, Sonstige, Kernkraft, Fossile Energieträger. Drei Balken pro Energieträger: 2021 (blau), 2022 (türkis), 2023 (orange). **Short description (overview):** Zwischen 2021 und 2023 stiegen die Anteile fast aller erneuerbarer Energieträger an der Gesamtstromerzeugung. Gleichzeitig sanken die Anteile von Kernkraft und fossilen Energieträgern. **Long description:** Der Anteil von Photovoltaik stieg von 8,4 auf 12,2 Prozent und der von Wind an Land von 15,6 auf 23,7 Prozent. Biomasse stieg von 7,7 auf 8,6 Prozent. Der Anteil von Kernkraft sank stark von 11,9 auf 1,4 Prozent. Die fossilen Energieträger sanken von 47,9 auf 44,7 Prozent.	**SBERT:** 0.8 **LLM as Judge:** *(n=1)* ▪ Clarity: 5 ▪ Completeness: 3 ▪ Conciseness: 2 ▪ PC: 4 ▪ Neutrality: 4 ▪ Correctness: 5
9. Alt text **Short description (metadata):** Waagerechtes Balkendiagramm. Titel: Erneuerbare Energien legen zu. Untertitel: Anteile an der Gesamtstromerzeugung in %. Waagrechte Achse: 0 bis 50 Prozent in Fünf-Prozent-Schritten. Senkrechte Achse: Kategorien Photovoltaik, Wind an Land, Wind auf See, Biomasse, Sonstige, Kernkraft und Fossile Energieträger. Drei Balken pro Kategorie: 2021 (dunkelblau), 2022 (türkis), 2023 (orange). **Short description (overview):** In den Jahren 2021 bis 2023 steigen die Anteile der erneuerbaren Energien signifikant an, insbesondere bei Photovoltaik und Wind an Land, während fossile Energieträger leicht sinken und Kernkraft stark abnimmt. **Long description:** Der Anteil von Photovoltaik steigt von 8,4 auf 12,2 Prozent und Wind an Land von 15,6 auf 23,7 Prozent. Wind auf See steigt leicht von 4,2 auf 4,7 Prozent, und Biomasse von 7,7 auf 8,6 Prozent. Kernkraft sinkt stark von 11,9 auf 1,4 Prozent. Die fossilen Energieträger sinken leicht von 47,9 auf 44,7 Prozent.	**SBERT:** 0.77 **LLM as Judge:** *(n=1)* ▪ Clarity: 4 ▪ Completeness: 2 ▪ Conciseness: 2 ▪ PC: 5 ▪ Neutrality: 5 ▪ Correctness: 4

10. Alt text	SBERT: 0.77
Short description (metadata): Waagerechtes Balkendiagramm. Titel: Erneuerbare Energien legen zu. Untertitel: Anteile an der Gesamtstromerzeugung in Prozent. Waagrechte Achse: 0 bis 50 Prozent. Senkrechte Achse: Photovoltaik, Wind an Land, Wind auf See, Biomasse, Sonstige, Kernkraft, Fossile Energieträger. Drei Balken pro Energieträger: 2021 (dunkelblau), 2022 (türkis), 2023 (orange). **Short description (overview):** Während Wind und Sonne deutlich an der Stromerzeugung gewinnen, bleibt der Anteil fossiler Energieträger auf einem hohen Niveau. **Long description:** Der Anteil von Wind an Land steigt von 15,6 auf 23,7 Prozent, Photovoltaik von 8,4 auf 12,2 Prozent. Kernkraft sinkt stark von 11,9 auf 1,4 Prozent. Die Spannweite von Wind auf See, Biomasse und Sonstige liegt zwischen 4,1 (Sonstige, 2022) und 8,6 Prozent (Biomasse, 2023). Der Anteil fossiler Energieträger bewegt sich zwischen 44,7 und 49,7 Prozent.	**LLM as Judge:** *(n=1)* ▪ Clarity: 4 ▪ Completeness: 4 ▪ Conciseness: 1 ▪ PC: 5 ▪ Neutrality: 3 ▪ Correctness: 5

01ba465f792500066ff5d6bee1f170c1

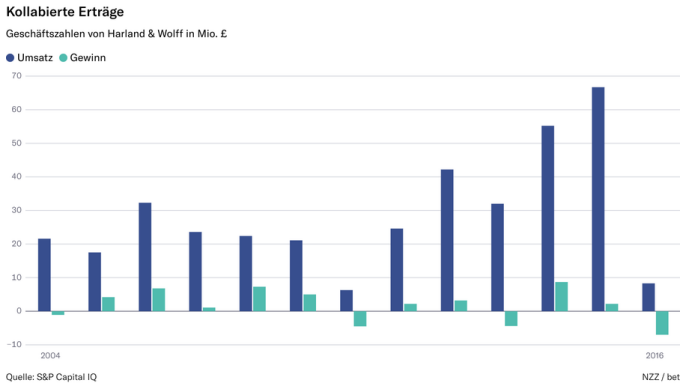

Golden standard

Short description (metadata): Senkrechtes Balkendiagramm. Titel: Kollabierte Erträge. Untertitel: Geschäftszahlen von Harland & Wolff in Mio. £. Waagrechte Achse: 2004 bis 2016. Senkrechte Achse: Minus 10 bis 70 Millionen £. Zwei Balken pro Jahr: Umsatz (blau), Gewinn (türkis).

Short description (overview): Zwischen 2004 und 2016 schwanken Umsatz und Gewinn von Harland & Wolff deutlich, wobei der Umsatz in allen Jahren höher ausfällt als der Gewinn.

Long description: Von 2004 bis 2011 liegt der Umsatz überwiegend zwischen 20 und 30 Millionen Pfund, mit einem Ausreisser nach unten auf etwa 6 Millionen Pfund (2010). Zwischen 2012 und 2015 steigt der Umsatz auf über 60 Millionen Pfund, bevor er 2016 auf unter 10 Millionen fällt. Der Gewinn zeigt im gleichen Zeitraum Schwankungen zwischen rund 9 Millionen und minus 7 Millionen Pfund. Ein klarer Zusammenhang zwischen Umsatz und Gewinn ist nicht erkennbar.

1. Alt text **Short description (metadata):** Senkrechtes Balkendiagramm. Titel: Kollabierte Erträge. Untertitel: Geschäftszahlen von Harland & Wolff in Mio. £. Waagrechte Achse: Zeitreihe von 2004 bis 2016. Senkrechte Achse (Ausschnitt): minus zehn bis 70 Millionen Pfund. Zwei Balken pro Jahr: Umsatz (dunkelblau), Gewinn (türkis). **Short description (overview):** Der Umsatz von Harland & Wolff schwankt stark, mit einem Höchstwert im Jahr 2015, während der Gewinn grösstenteils im positiven Bereich liegt, jedoch mehrfach Verluste aufweist. **Long description:** Der Umsatz bewegt sich zwischen 6.3 Millionen Pfund im Jahr 2010 und 66.7 Millionen Pfund im Jahr 2015. Die Gewinnwerte liegen zwischen minus 7.0 Millionen Pfund im Jahr 2016 und 8.7 Millionen Pfund im Jahr 2014. Gewinneinbrüche unter Null sind in den Jahren 2004, 2010, 2013 und 2016 zu verzeichnen.	**SBERT:** 0.87 **LLM as Judge:** *(n=1)* ▪ Clarity: 4 ▪ Completeness: 4 ▪ Conciseness: 1 ▪ PC: 4 ▪ Neutrality: 3 ▪ Correctness: 5
2. Alt text **Short description (metadata):** Senkrechtes Balkendiagramm. Titel: Kollabierte Erträge. Untertitel: Geschäftszahlen von Harland & Wolff in Mio. £. Waagrechte Achse: Zeitreihe von 2004 bis 2016. Senkrechte Achse: minus zehn bis 70 Mio. £. Zwei Balken pro Jahr: Umsatz (dunkelblau), Gewinn (hellgrün). **Short description (overview):** Der Umsatz von Harland & Wolff schwankt deutlich im Zeitraum von 2004 bis 2016. Der Gewinn ist in den meisten Jahren positiv, weist jedoch auch signifikante Verluste auf, besonders im Jahr 2016. **Long description:** Der Umsatz bewegt sich zwischen 6,3 Millionen £ (2010) und 66,7 Millionen £ (2015). Nach dem Höchstwert sinkt der Umsatz 2016 stark. Der Gewinn fluktuiert zwischen minus 7,0 Millionen £ (2016) und 8,7 Millionen £ (2014). In den Jahren 2004, 2010, 2013 und 2016 verzeichnet das Unternehmen Verluste.	**SBERT:** 0.87 **LLM as Judge:** *(n=1)* ▪ Clarity: 5 ▪ Completeness: 3 ▪ Conciseness: 1 ▪ PC: 5 ▪ Neutrality: 5 ▪ Correctness: 5
3. Alt text **Short description (metadata):** Senkrechtes Balkendiagramm. Titel: Kollabierte Erträge. Untertitel: Geschäftszahlen von Harland & Wolff in Mio. £. Waagrechte Achse: Zeitreihe von 2004 bis 2016 (Intervall 1 Jahr). Senkrechte Achse: Ausschnitt minus zehn bis 70 Mio. £. Zwei Balken pro Jahr: Umsatz (dunkelblau), Gewinn (türkis). **Short description (overview):** Der Umsatz von Harland & Wolff schwankt über den Zeitraum stark und erreicht 2015 einen Höchstwert, während der Gewinn mehrfach im negativen Bereich liegt, insbesondere 2016. **Long description:** Der Umsatz bewegt sich von 21,6 Millionen Pfund im Jahr 2004 bis auf 66,7 Millionen Pfund im Jahr 2015, sinkt dann aber stark auf 8,3 Millionen Pfund im Jahr 2016. Der Gewinn liegt mehrfach im negativen Bereich, etwa 2004 bei minus 1,1 Millionen Pfund und 2016 bei minus 7,0 Millionen Pfund. Die höchsten Gewinne werden 2014 mit 8,7 Millionen Pfund erzielt.	**SBERT:** 0.87 **LLM as Judge:** *(n=1)* ▪ Clarity: 5 ▪ Completeness: 3 ▪ Conciseness: 1 ▪ PC: 5 ▪ Neutrality: 5 ▪ Correctness: 5

4. Alt text **Short description (metadata):** Senkrechtes Balkendiagramm. Titel: Kollabierte Erträge. Untertitel: Geschäftszahlen von Harland & Wolff in Mio. £. Waagrechte Achse: Zeitreihe von 2004 bis 2016. Senkrechte Achse: minus zehn bis 70 Mio. £. Zwei Balken pro Jahr: Umsatz (dunkelblau), Gewinn (hellgrün). **Short description (overview):** Der Umsatz von Harland & Wolff schwankte stark mit einem Höchststand im Jahr 2015, während der Gewinn in mehreren Jahren negativ war und ebenfalls erheblich schwankte. **Long description:** Der Umsatz bewegt sich zwischen 6,3 Millionen £ (2010 und 2016) und 66,7 Millionen £ (2015). Der Gewinn liegt im Zeitraum zwischen minus 7,0 Millionen £ (2016) und 8,7 Millionen £ (2014). Negative Gewinne verzeichnen die Jahre 2004, 2010, 2013 und 2016.	**SBERT:** 0.87 **LLM as Judge:** *(n=1)* ▪ Clarity: 3 ▪ Completeness: 5 ▪ Conciseness: 2 ▪ PC: 5 ▪ Neutrality: 3 ▪ Correctness: 3
5. Alt text **Short description (metadata):** Senkrechtes Balkendiagramm. Titel: Kollabierte Erträge. Untertitel: Geschäftszahlen von Harland & Wolff in Mio. £. Waagrechte Achse: Zeitreihe von 2004 bis 2016. Senkrechte Achse: minus 10 bis 70 Mio. £. Zwei Balken pro Jahr: Umsatz (dunkelblau), Gewinn (türkis). **Short description (overview):** Der Umsatz von Harland & Wolff schwankt stark über die Jahre, mit einem Tiefststand im Jahr 2016. Der Gewinn ist in den meisten Jahren positiv, weist aber ebenfalls große Schwankungen auf und ist in einigen Jahren negativ. **Long description:** Der Umsatz zeigt eine starke Volatilität. Nach einem Anstieg von 21,6 Millionen Pfund im Jahr 2004 auf den Höchstwert von 66,7 Millionen Pfund im Jahr 2015 sinkt er stark auf 8,3 Millionen Pfund im Jahr 2016. Der Gewinn liegt überwiegend im positiven Bereich, ist aber in den Jahren 2004, 2010, 2013 und 2016 negativ. Das Maximum erreicht der Gewinn im Jahr 2014 mit 8,7 Millionen Pfund und das Minimum im Jahr 2016 mit minus 7,0 Millionen Pfund.	**SBERT:** 0.86 **LLM as Judge:** *(n=1)* ▪ Clarity: 5 ▪ Completeness: 5 ▪ Conciseness: 1 ▪ PC: 5 ▪ Neutrality: 5 ▪ Correctness: 3
6. Alt text **Short description (metadata):** Senkrechtes Balkendiagramm. Titel: Kollabierte Erträge. Untertitel: Geschäftszahlen von Harland & Wolff in Mio. £. Waagrechte Achse: Zeitreihe von 2004 bis 2016. Senkrechte Achse: minus zehn bis 70 Mio. £. Zwei Balken pro Jahr: Umsatz (dunkelblau), Gewinn (hellgrün). **Short description (overview):** Der Umsatz von Harland & Wolff schwankt stark über die Jahre, von einem Tiefpunkt im Jahr 2010 stark steigend bis 2015, während der Gewinn meist gering ist und häufig negativ. **Long description:** Der Umsatz bewegt sich zwischen 6,3 Mio. £ (2010) und 66,7 Mio. £ (2015). Der Gewinn liegt in den meisten Jahren im einstelligen Millionenbereich und ist fünfmal negativ (2004, 2010, 2013, 2016). Zwischen 2010 und 2015 steigen die Umsatzzahlen stark, von 6,3 Mio. £ auf 66,7 Mio. £. Die Jahre 2015 und 2016 bilden den höchsten Umsatz- bzw. den geringsten Gewinnwert der gesamten Periode.	**SBERT:** 0.84 **LLM as Judge:** *(n=1)* ▪ Clarity: 5 ▪ Completeness: 4 ▪ Conciseness: 2 ▪ PC: 4 ▪ Neutrality: 5 ▪ Correctness: 3

7. Alt text **Short description (metadata):** Senkrechtes Balkendiagramm. Titel: Kollabierte Erträge. Untertitel: Geschäftszahlen von Harland & Wolff in Mio. £. Waagrechte Achse: Zeitreihe von 2004 bis 2016. Senkrechte Achse: von minus 10 bis 70 Mio. £. Zwei Balken pro Jahr: Umsatz (dunkelblau), Gewinn (helltürkis). **Short description (overview):** Der Umsatz von Harland & Wolff schwankte stark im Beobachtungszeitraum und erreichte 2015 einen Höchstwert, während der Gewinn zwischen minus 7 und 8.7 Millionen Pfund lag und keine klare Trendentwicklung zeigte. **Long description:** Der Umsatz bewegt sich zwischen 6.3 Millionen Pfund im Jahr 2010 und 66.7 Millionen Pfund im Jahr 2015. Der Gewinn variiert zwischen minus 7 Millionen Pfund im Jahr 2016 und 8.7 Millionen Pfund im Jahr 2014. Der Gewinn ist in den Jahren 2004, 2010, 2013 und 2016 negativ.	**SBERT:** 0.84 **LLM as Judge:** *(n=1)* ▪ Clarity: 5 ▪ Completeness: 4 ▪ Conciseness: 2 ▪ PC: 5 ▪ Neutrality: 3 ▪ Correctness: 4
8. Alt text **Short description (metadata):** Senkrechtes Balkendiagramm. Titel: Kollabierte Erträge. Untertitel: Geschäftszahlen von Harland & Wolff in Mio. £. Waagrechte Achse: Zeitreihe von 2004 bis 2016 (Intervall/Abstand: 1 Jahr). Senkrechte Achse: minus 10 bis 70 Mio. £. Zwei Balken pro Jahr: Umsatz (dunkelblau), Gewinn (hellblau). **Short description (overview):** Während der Umsatz von Harland & Wolff im betrachteten Zeitraum stark schwankt, liegt der Gewinn meistens im positiven Bereich, weist jedoch in vier Jahren Verluste auf. **Long description:** Der Umsatz schwankt stark, beginnt 2004 bei 21.6 Millionen Pfund, sinkt bis 2010 auf 6.3 Millionen Pfund und steigt danach bis 2015 auf den Höchstwert von 66.7 Millionen Pfund, bevor er 2016 auf 8.3 Millionen Pfund sinkt. Der Gewinn liegt meistens im positiven Bereich, mit negativen Werten von minus 1.1 (2004), minus 4.5 (2010), minus 4.4 (2013) und minus 7.0 (2016). Der höchste Gewinn wird 2014 mit 8.7 Millionen Pfund verzeichnet.	**SBERT:** 0.83 **LLM as Judge:** *(n=1)* ▪ Clarity: 5 ▪ Completeness: 5 ▪ Conciseness: 1 ▪ PC: 5 ▪ Neutrality: 5 ▪ Correctness: 4
9. Alt text **Short description (metadata):** Senkrechtes Balkendiagramm. Titel: Kollabierte Erträge. Untertitel: Geschäftszahlen von Harland & Wolff in Mio. £. Waagrechte Achse: Zeitreihe von 2004 bis 2016. Senkrechte Achse: minus 10 bis 70 Mio. £. Zwei Balken pro Jahr: Umsatz (dunkelblau), Gewinn (türkis). **Short description (overview):** Der Umsatz von Harland & Wolff zeigt über den Zeitraum 2004 bis 2016 eine stark schwankende Entwicklung mit einem Maximum im Jahr 2015, während der Gewinn mehrfach negativ ausfällt. **Long description:** Der Umsatz bewegt sich zwischen 6,3 Mio. £ (2010) und 66,7 Mio. £ (2015). Nach 21,6 Mio. £ im Jahr 2004 fällt der Umsatz auf 6,3 Mio. £ (2010), steigt bis 2015 auf 66,7 Mio. £ und sinkt im Jahr 2016 stark auf 8,3 Mio. £. Der Gewinn ist 2004 negativ (minus 1,1 Mio. £), fällt 2010 auf minus 4,5 Mio. £, steigt 2014 auf 8,7 Mio. £ und sinkt 2016 auf minus 7,0 Mio. £.	**SBERT:** 0.83 **LLM as Judge:** *(n=1)* ▪ Clarity: 5 ▪ Completeness: 5 ▪ Conciseness: 1 ▪ PC: 5 ▪ Neutrality: 5 ▪ Correctness: 5

10. Alt text	SBERT: 0.82
Short description (metadata): Senkrechtes Balkendiagramm. Titel: Kollabierte Erträge. Untertitel: Geschäftszahlen von Harland & Wolff in Mio. £. Waagrechte Achse: Zeitreihe von 2004 bis 2016 (jährlich). Senkrechte Achse: minus 10 bis 70 Mio. £. Zwei Balken pro Jahr: Umsatz (dunkelblau), Gewinn (helltürkis). **Short description (overview):** Der Umsatz von Harland & Wolff schwankt stark im Zeitraum 2004 bis 2016 und erreicht 2015 ein Maximum. Der Gewinn ist in den meisten Jahren positiv, weist aber auch vier Jahre mit Verlusten auf, darunter ein historisches Tief 2016. **Long description:** Der Umsatz bewegt sich bis 2010 zwischen 6,3 Mio. und 32,3 Mio. £, um dann stark zu steigen und 2015 bei 66,7 Mio. £ zu liegen. 2016 sinkt er auf 8,3 Mio. £. Der Gewinn liegt in vier Jahren im negativen Bereich: 2004 (minus 1,1 Mio. £), 2010 (minus 4,5 Mio. £), 2013 (minus 4,4 Mio. £) und 2016 (minus 7,0 Mio. £). Das Maximum des Gewinns wird 2014 mit 8,7 Mio. £ erreicht. Im letzten Jahr liegt der Gewinn bei minus 7,0 Mio. £.	**LLM as Judge:** *(n=1)* ▪ Clarity: 5 ▪ Completeness: 5 ▪ Conciseness: 2 ▪ PC: 5 ▪ Neutrality: 3 ▪ Correctness: 5

006f6723bd41797d2bb1e3f65444757f

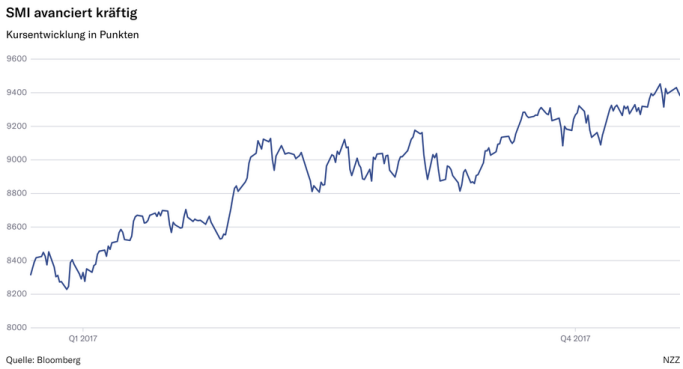

Golden standard

Short description (metadata): Liniendiagramm. Titel: SMI avanciert kräftig. Untertitel: Kursentwicklung in Punkten. Waagrechte Achse: Zeitraum Anfang Januar bis Ende Dezember 2017. Senkrechte Achse: Ausschnitt von 8000 bis 9600 Punkten. Daten: Tägliche Werte.

Short description (overview): Der SMI steigt 2017 um rund 1100 Punkte und zeigt dabei Schwankungen von wenigen bis zu 200 Punkten.

Long description: Anfang Januar beträgt der SMI rund 8300 Punkte, steigt bis Ende März auf gut 8600 Punkten und überschreitet sprunghaft die 9000-Punkte-Marke anfangs Mai. Über den Sommer pendelt er zwischen 8800 und 9200 Punkten, bevor er bis Jahresende auf rund 9400 Punkte steigt.

1. Alt text **Short description (metadata):** Liniendiagramm. Titel: SMI avanciert kräftig. Untertitel: Kursentwicklung in Punkten. Waagerechte Achse: Zeitraum Q1 2017 bis Q4 2017. Senkrechte Achse: Ausschnitt 8000 bis 9600 Punkte. Daten: Täglich Werte. **Short description (overview):** Der Kurs des SMI steigt über das Jahr 2017 hinweg deutlich an, wobei der grösste Anstieg im zweiten Halbjahr erfolgt und von starken Schwankungen begleitet wird. **Long description:** Der SMI Kurs startet Anfang 2017 bei rund 8300 Punkten und steigt bis Ende März auf etwa 8650 Punkte. Im zweiten Quartal steigt der Kurs zuerst stark auf über 9100 Punkte im Mai, sinkt aber bis Ende Juni auf rund 8900 Punkte. In Q3 setzt ein Anstieg auf über 9100 Punkte ein, gefolgt von einem leichten Rückgang bis Ende August, bevor der Kurs bis Ende September auf rund 9200 Punkte steigt. Im vierten Quartal steigt der Kurs bis zum Jahresende auf den Höchststand von rund 9400 Punkten.	**SBERT:** 0.86 **LLM as Judge:** *(n=1)* ▪ Clarity: 4 ▪ Completeness: 4 ▪ Conciseness: 2 ▪ PC: 5 ▪ Neutrality: 2 ▪ Correctness: 3
2. Alt text **Short description (metadata):** Liniendiagramm. Titel: SMI avanciert kräftig. Untertitel: Kursentwicklung in Punkten. Waagerechte Achse: Zeitraum Anfang Q1 2017 bis Ende Q4 2017. Senkrechte Achse: Ausschnitt 8000 bis 9600 Punkte. Daten: Tägliche Werte. **Short description (overview):** Der SMI steigt über das gesamte Jahr 2017 hinweg stark an, beginnend bei rund 8300 Punkten und endend bei über 9300 Punkten. **Long description:** Der Index startet Anfang Januar 2017 bei etwa 8316 Punkten. Nach anfänglichen Schwankungen mit einem Tiefpunkt bei 8229 Punkten im Januar steigt der Wert bis Ende April auf über 8800 Punkte und erreicht im Mai einen ersten Höchststand von 9123 Punkten nach einem rasanten Anstieg. Bis Ende August schwankt der Index, tendiert jedoch leicht abwärts, bis ein Tief bei 8814 Punkten erreicht ist. Von September an steigt der SMI mit geringen Schwankungen kontinuierlich und erreicht Ende Dezember seinen Höchstwert von 9452 Punkten, bevor er leicht auf 9383 Punkte sinkt.	**SBERT:** 0.85 **LLM as Judge:** *(n=1)* ▪ Clarity: 5 ▪ Completeness: 5 ▪ Conciseness: 1 ▪ PC: 5 ▪ Neutrality: 1 ▪ Correctness: 5
3. Alt text **Short description (metadata):** Liniendiagramm. Titel: SMI avanciert kräftig. Untertitel: Kursentwicklung in Punkten. Waagrechte Achse: Zeitraum Anfang Q1 2017 bis Ende Q4 2017. Senkrechte Achse: Ausschnitt 8000 bis 9600 Punkte. Daten: Täglich Werte. **Short description (overview):** Der SMI-Kurs steigt über das Jahr 2017 hinweg kontinuierlich an, wobei er in der zweiten Jahreshälfte stärkere Schwankungen zeigt. **Long description:** Der Kurs beginnt bei etwa 8300 Punkten und steigt bis Ende Q1 auf rund 8650 Punkte. Nach einem Anstieg auf knapp über 9100 Punkte im Mai, fällt er kurz ab, um bis Oktober auf etwa 9250 Punkte zu steigen. Das Jahr endet mit dem Höchstwert von rund 9400 Punkten.	**SBERT:** 0.85 **LLM as Judge:** *(n=1)* ▪ Clarity: 5 ▪ Completeness: 3 ▪ Conciseness: 2 ▪ PC: 5 ▪ Neutrality: 2 ▪ Correctness: 2

4. Alt text **Short description (metadata):** Liniendiagramm. Titel: SMI avanciert kräftig. Untertitel: Kursentwicklung in Punkten. Waagerechte Achse: Zeitraum Q1 2017 bis Q4 2017. Senkrechte Achse: Ausschnitt 8000 bis 9600 Punkte. Daten: Täglich Werte. **Short description (overview):** Der SMI-Index verzeichnete im Jahr 2017 insgesamt einen deutlichen Aufwärtstrend mit bemerkenswerten Schwankungen, insbesondere in der Jahresmitte. **Long description:** Der Index beginnt 2017 bei rund 8300 Punkten, sinkt kurzzeitig auf etwa 8229 Punkte (Ende Januar), bevor er bis Ende März auf rund 8660 Punkte steigt. Nach einem leichten Rückgang steigt er von Ende April (8711) auf beinahe 9150 Punkte (Mitte Mai). Der Index schwankt danach stark, sinkend auf ungefähr 8810 (Anfang Juni), bevor er im Juli/August zwischen circa 8870 und 9170 Punkten pendelt. Ab September steigt der Index wieder deutlich und stabilisiert sich im vierten Quartal zwischen 9150 und 9450, mit dem Höchstwert von rund 9452 Punkten am 18. Dezember.	**SBERT:** 0.84 **LLM as Judge:** *(n=1)* ▪ Clarity: 5 ▪ Completeness: 5 ▪ Conciseness: 2 ▪ PC: 5 ▪ Neutrality: 2 ▪ Correctness: 5
5. Alt text **Short description (metadata):** Liniendiagramm. Titel: SMI avanciert kräftig. Untertitel: Kursentwicklung in Punkten. Waagerechte Achse: Zeitraum Q1 2017 bis Q4 2017. Senkrechte Achse: Ausschnitt 8000 bis 9600 Punkte. Daten: Tägliche Werte. **Short description (overview):** Die SMI-Kursentwicklung zeigt im Jahr 2017 einen deutlichen Aufwärtstrend mit kontinuierlichen Schwankungen und erreicht zum Jahresende hin einen Höchstwert. **Long description:** Die Kurse steigen von etwa 8316 Punkten Anfang März 2017 zunächst leicht, sinken dann bis Mitte Januar auf rund 8229 Punkte. Danach steigen sie bis Ende Mai auf über 9100 Punkte. Es folgen starke Schwankungen bei etwa 8800 bis 9000 Punkten, bevor die Kurse im September stark steigen und bis Ende Dezember den Höchstwert von rund 9452 Punkten erreichen.	**SBERT:** 0.82 **LLM as Judge:** *(n=1)* ▪ Clarity: 3 ▪ Completeness: 3 ▪ Conciseness: 2 ▪ PC: 2 ▪ Neutrality: 3 ▪ Correctness: 1
6. Alt text **Short description (metadata):** Liniendiagramm. Titel: SMI avanciert kräftig. Untertitel: Kursentwicklung in Punkten. Waagrechte Achse: Zeitraum Q1 2017 bis Q4 2017. Senkrechte Achse: Ausschnitt 8000 bis 9600 Punkte. Daten: Täglich Werte. **Short description (overview):** Die Aktienkurse des SMI steigen im Verlauf des Jahres 2017 mit Schwankungen kontinuierlich an und erreichen am Ende des Jahres den Höchstwert. **Long description:** Der SMI Kurs startet Anfang 2017 bei rund 8300 Punkten und sinkt bis Ende Januar auf den Tiefstwert von 8229 Punkten. Danach steigt der Kurs, mit einer Phase leichter Rückgänge im März und April, bis Mitte Mai auf über 9100 Punkte. Von Juni bis September schwankt der Kurs stark um 9000 Punkte, bevor er im letzten Quartal auf das Jahresmaximum von 9452 Punkten am 18. Dezember steigt.	**SBERT:** 0.82 **LLM as Judge:** *(n=1)* ▪ Clarity: 5 ▪ Completeness: 5 ▪ Conciseness: 2 ▪ PC: 5 ▪ Neutrality: 3 ▪ Correctness: 5

7. Alt text **Short description (metadata):** Liniendiagramm. Titel: SMI avanciert kräftig. Untertitel: Kursentwicklung in Punkten. Waagrechte Achse: Zeitraum Q1 2017 bis Q4 2017. Senkrechte Achse: Ausschnitt 8000 bis 9600 Punkte. Daten: Täglich Werte. **Short description (overview):** Die SMI-Kursentwicklung zeigt im Verlauf des Jahres 2017 einen deutlichen Anstieg, unterbrochen von Phasen starker Schwankungen. **Long description:** Der SMI startet Anfang 2017 bei rund 8316 Punkten und verzeichnet bis Ende März einen Anstieg auf rund 8659 Punkte. Bis Ende Mai steigt der Wert auf das Niveau von 9127 Punkten, gefolgt von einer Phase starker Schwankungen bis Ende August. Ab September setzt ein kontinuierlicher Anstieg ein, der bis zum Höchstwert von rund 9452 Punkten im Dezember führt.	**SBERT:** 0.81 **LLM as Judge:** *(n=1)* ▪ Clarity: 5 ▪ Completeness: 5 ▪ Conciseness: 2 ▪ PC: 5 ▪ Neutrality: 2 ▪ Correctness: 4
8. Alt text **Short description (metadata):** Liniendiagramm. Titel: SMI avanciert kräftig. Untertitel: Kursentwicklung in Punkten. Waagrechte Achse: Zeitraum Anfang Q1 2017 bis Ende Q4 2017. Senkrechte Achse: Ausschnitt 8000 bis 9600 Punkte. Daten: Täglich Werte. **Short description (overview):** Der SMI-Kurs steigt im Jahresverlauf 2017 kräftig an, unterbrochen von Phasen starker Schwankungen. **Long description:** Der Kurs beginnt 2017 bei rund 8300 Punkten und sinkt im Januar auf circa 8230 Punkte, bevor er bis Mitte März auf ungefähr 8700 Punkte ansteigt. Nach einer kurzen Phase der Schwankung zwischen 8500 und 8700 Punkten erfolgt Ende April ein starker Anstieg auf über 9100 Punkte im Mai. Nach einer Konsolidierungsphase im Sommer zwischen 8800 und 9100 Punkten steigt der Kurs im September über 9300 Punkte. Nach kleineren Schwankungen bis Ende November steigt der Kurs im Dezember auf über 9400 Punkte und beendet das Jahr bei rund 9380 Punkten.	**SBERT:** 0.81 **LLM as Judge:** *(n=1)* ▪ Clarity: 5 ▪ Completeness: 5 ▪ Conciseness: 2 ▪ PC: 5 ▪ Neutrality: 2 ▪ Correctness: 3
9. Alt text **Short description (metadata):** Liniendiagramm. Titel: SMI avanciert kräftig. Untertitel: Kursentwicklung in Punkten. Waagerechte Achse: Zeitraum Q1 2017 bis Q4 2017. Senkrechte Achse: Ausschnitt 8000 bis 9600 Punkte. Daten: Täglich Werte. **Short description (overview):** Der Kurs des SMI steigt über das Jahr 2017 hinweg deutlich, mit einigen Phasen hoher Volatilität, und erreicht zum Ende des Jahres Spitzenwerte. **Long description:** Der SMI beginnt das Jahr 2017 bei rund 8316 Punkten (Anfang Q1). Nach anfänglichen Schwankungen mit einem Tief bei circa 8229 Punkten im Januar, steigt der Kurs bis Ende März auf circa 8658 Punkte. Im zweiten Quartal setzt sich der Aufwärtstrend fort, beschleunigt sich im April und erreicht im Mai Werte um 9100 Punkte, gefolgt von einer Phase starker Schwankungen. Im dritten Quartal schwankt der Kurs zwischen 8814 und 9157 Punkten. Im vierten Quartal steigt der SMI stetig auf seinen Höchststand von 9452 Punkten im Dezember.	**SBERT:** 0.8 **LLM as Judge:** *(n=1)* ▪ Clarity: 4 ▪ Completeness: 5 ▪ Conciseness: 1 ▪ PC: 5 ▪ Neutrality: 2 ▪ Correctness: 4

10. Alt text	SBERT: 0.79
Short description (metadata): Liniendiagramm. Titel: SMI avanciert kräftig. Untertitel: Kursentwicklung in Punkten. Waagerechte Achse: Zeitraum Q1 2017 bis Q4 2017. Senkrechte Achse: Ausschnitt 8000 bis 9600 Punkte. Daten: Täglich Werte. **Short description (overview):** Der Kurs des SMI steigt über das Jahr 2017 von ca. 8300 Punkten auf ca. 9400 Punkte, wobei er in der Mitte des Jahres eine Phase mit grösseren Schwankungen erfährt. **Long description:** Der Kurs startet Anfang Q1 2017 bei etwa 8300 Punkten und sinkt leicht, bevor er bis Ende Q1 auf ca. 8700 Punkte steigt. Im zweiten Quartal steigt der Kurs stark und erreicht mit kleinen Rücksetzern fast 9200 Punkte. Im zweiten Halbjahr schwankt der Kurs zwischen 8800 und 9100 Punkten, steigt aber gegen Ende des Jahres auf den Höchststand von ca. 9400 Punkten.	**LLM as Judge:** *(n=1)* ▪ Clarity: 4 ▪ Completeness: 4 ▪ Conciseness: 2 ▪ PC: 5 ▪ Neutrality: 2 ▪ Correctness: 2

07d00172c0f2b9dd3facaed885de0c8d

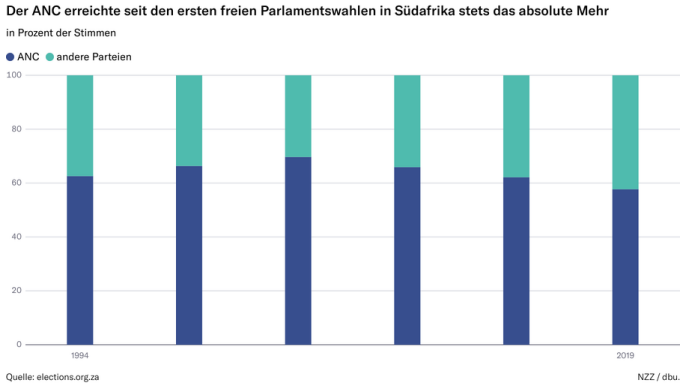

Golden standard

Short description (metadata): Senkrechtes Balkendiagramm. Titel: Der ANC erreichte seit den ersten freien Parlamentswahlen in Südafrika stets das absolute Mehr. Untertitel: in Prozent der Stimmen. Waagrechte Achse: 1994 bis 2019 in Fünfjahresschritten. Senkrechte Achse: 0 bis 100 Prozent. Pro Jahr ein Balken, unterteilt in zwei Anteile: ANC (blau), andere Parteien (türkis).

Short description (overview): Der ANC hat bei jeder Wahl in Südafrika die absolute Mehrheit der Stimmen.

Long description: Der ANC steigert seinen Stimmenanteil von rund 63 % (1994) auf etwa 70 % (2004), den Höchstwert. Seither sinkt er kontinuierlich und beträgt 2019 knapp 60 %.

1. Alt text **Short description (metadata):** Senkrecht gestapeltes Balkendiagramm. Titel: Der ANC erreichte seit den ersten freien Parlamentswahlen in Südafrika stets das absolute Mehr. Untertitel: in Prozent der Stimmen. Waagrechte Achse: 0 bis 100 Prozent. Senkrechte Achse: 1994, 1999, 2004, 2009, 2014, 2019. Segmente pro Balken: ANC (dunkelblau), andere Parteien (türkis). **Short description (overview):** Der Stimmenanteil des ANC blieb über den gesamten Zeitraum über der absoluten Mehrheit, zeigt aber insgesamt einen sinkenden Trend. **Long description:** Der Stimmenanteil des ANC sank von 62,60 Prozent im Jahr 1994 auf 57,70 Prozent im Jahr 2019, mit einem Höchststand von 69,69 Prozent im Jahr 2004. Entsprechend stieg der Anteil der anderen Parteien von 37,40 Prozent im Jahr 1994 auf 42,30 Prozent im Jahr 2019.	**SBERT:** 0.86 **LLM as Judge:** *(n=1)* ▪ Clarity: 5 ▪ Completeness: 3 ▪ Conciseness: 2 ▪ PC: 5 ▪ Neutrality: 5 ▪ Correctness: 2
2. Alt text **Short description (metadata):** Senkrecht gestapeltes Balkendiagramm. Titel: Der ANC erreichte seit den ersten freien Parlamentswahlen in Südafrika stets das absolute Mehr. Untertitel: in Prozent der Stimmen. Waagrechte Achse: 0 bis 100 Prozent. Senkrechte Achse: 1994, 1999, 2004, 2009, 2014, 2019. Segmente pro Balken: ANC (dunkelblau), andere Parteien (türkis). **Short description (overview):** Der ANC hält seit 1994 die absolute Mehrheit, wobei sein Stimmenanteil im Zeitverlauf tendenziell sinkt und der Anteil der anderen Parteien steigt. **Long description:** Der Stimmenanteil des ANC lag 1994 bei 62,6 Prozent und stieg bis 2004 auf den Höchstwert von 69,7 Prozent. Seit 2004 sinkt der Anteil des ANC kontinuierlich und erreicht 2019 den Tiefstwert von 57,7 Prozent. Der Anteil anderer Parteien bewegte sich zwischen dem Tiefstwert von 30,3 Prozent im Jahr 2004 und dem Höchstwert von 42,3 Prozent im Jahr 2019.	**SBERT:** 0.86 **LLM as Judge:** *(n=1)* ▪ Clarity: 4 ▪ Completeness: 2 ▪ Conciseness: 2 ▪ PC: 5 ▪ Neutrality: 5 ▪ Correctness: 4
3. Alt text **Short description (metadata):** Senkrecht gestapeltes Balkendiagramm. Titel: Der ANC erreichte seit den ersten freien Parlamentswahlen in Südafrika stets das absolute Mehr. Untertitel: in Prozent der Stimmen. Waagrechte Achse: 0 bis 100 Prozent. Senkrechte Achse: 1994, 1999, 2004, 2009, 2014, 2019. Segmente pro Balken: ANC (dunkelblau), andere Parteien (türkis). **Short description (overview):** Der ANC hält seit 1994 die absolute Mehrheit, jedoch sinkt sein Stimmenanteil tendenziell. **Long description:** Der Stimmenanteil des ANC lag 1994 bei 62,6 Prozent, stieg bis 2004 auf 69,69 Prozent und sank seither auf 57,7 Prozent im Jahr 2019. Entsprechend stieg der Anteil der anderen Parteien von 37,4 Prozent (1994) auf 42,3 Prozent (2019).	**SBERT:** 0.85 **LLM as Judge:** *(n=1)* ▪ Clarity: 5 ▪ Completeness: 4 ▪ Conciseness: 1 ▪ PC: 5 ▪ Neutrality: 5 ▪ Correctness: 3

4. Alt text **Short description (metadata):** Senkrecht gestapeltes Balkendiagramm. Titel: Der ANC erreichte seit den ersten freien Parlamentswahlen in Südafrika stets das absolute Mehr. Untertitel: in Prozent der Stimmen. Waagrechte Achse: 0 bis 100 Prozent. Senkrechte Achse: 1994, 1999, 2004, 2009, 2014, 2019. Segmente pro Balken: ANC (dunkelblau), andere Parteien (türkis). **Short description (overview):** Der ANC hält seit 1994 die absolute Mehrheit der Stimmen, jedoch sinkt der Anteil des ANC an den Gesamtstimmen über die Zeit. **Long description:** Der Stimmenanteil des ANC begann bei 62,6 Prozent im Jahr 1994, erreichte seinen Höchstwert von 69,7 Prozent im Jahr 2004 und sank bis 2019 auf 57,7 Prozent. Im gleichen Zeitraum stieg der Anteil der Stimmen für andere Parteien von 37,4 Prozent (1994) auf 42,3 Prozent (2019).	**SBERT:** 0.83 **LLM as Judge:** *(n=1)* ▪ Clarity: 4 ▪ Completeness: 4 ▪ Conciseness: 2 ▪ PC: 5 ▪ Neutrality: 5 ▪ Correctness: 3
5. Alt text **Short description (metadata):** Senkrecht gestapeltes Balkendiagramm. Titel: Der ANC erreichte seit den ersten freien Parlamentswahlen in Südafrika stets das absolute Mehr. Untertitel: in Prozent der Stimmen. Die senkrechte Achse reicht von 0 bis 100 in Prozent. Die waagrechte Achse zeigt die Jahre 1994, 1999, 2004, 2009, 2014, 2019. Pro Jahr ein Balken, unterteilt in zwei Segmente: ANC (dunkelblau), andere Parteien (türkis). **Short description (overview):** Der ANC hält seit 1994 die absolute Mehrheit in Südafrika, allerdings sinkt dieser Anteil kontinuierlich von 2004 bis 2019. **Long description:** Der ANC erreichte 1994 einen Stimmenanteil von 62,6 Prozent, der bis 2004 auf 69,69 Prozent stieg. Danach sank der Anteil fast kontinuierlich ab und erreichte 2019 den Tiefstwert von 57,7 Prozent.	**SBERT:** 0.83 **LLM as Judge:** *(n=1)* ▪ Clarity: 5 ▪ Completeness: 3 ▪ Conciseness: 2 ▪ PC: 5 ▪ Neutrality: 5 ▪ Correctness: 5
6. Alt text **Short description (metadata):** Senkrecht gestapeltes Balkendiagramm. Titel: Der ANC erreichte seit den ersten freien Parlamentswahlen in Südafrika stets das absolute Mehr. Untertitel: in Prozent der Stimmen. Waagrechte Achse: 1994, 1999, 2004, 2009, 2014, 2019. Senkrechte Achse: 0 bis 100 Prozent. Segmente pro Balken: ANC (dunkelblau), andere Parteien (türkis). **Short description (overview):** Der Stimmenanteil des ANC lag in allen dargestellten Wahlen über 50 Prozent, sank jedoch seit 2004 deutlich. **Long description:** Der Stimmenanteil des ANC stieg von 62,60 Prozent im Jahr 1994 auf einen Höchstwert von 69,69 Prozent im Jahr 2004, um anschliessend kontinuierlich auf 57,70 Prozent im Jahr 2019 zu sinken. Der Anteil der anderen Parteien stieg entsprechend von 30,31 Prozent im Jahr 2004 auf 42,30 Prozent im Jahr 2019.	**SBERT:** 0.83 **LLM as Judge:** *(n=1)* ▪ Clarity: 5 ▪ Completeness: 3 ▪ Conciseness: 2 ▪ PC: 5 ▪ Neutrality: 3 ▪ Correctness: 5
7. Alt text **Short description (metadata):** Senkrecht gestapeltes Balkendiagramm. Titel: Der ANC erreichte seit den ersten freien Parlamentswahlen in Südafrika stets das absolute Mehr. Untertitel: in Prozent der Stimmen. Waagrechte Achse: 1994, 1999, 2004, 2009, 2014, 2019. Senkrechte Achse: 0 bis 100 Prozent. Segmente pro Balken: ANC (dunkelblau), andere Parteien (türkis). **Short description (overview):** Der ANC dominierte die Wahlen von 1994 bis 2019, allerdings sank sein Stimmenanteil tendenziell. **Long description:** Der Stimmenanteil des ANC sank von 62,60 Prozent im Jahr 1994 auf 57,70 Prozent im Jahr 2019. Den höchsten Stimmenanteil erreichte der ANC im Jahr 2004 mit 69,69 Prozent. Der Anteil anderer Parteien stieg seit 2004 stetig an und erreichte im Jahr 2019 den Höchstwert von 42,30 Prozent.	**SBERT:** 0.83 **LLM as Judge:** *(n=1)* ▪ Clarity: 5 ▪ Completeness: 3 ▪ Conciseness: 1 ▪ PC: 5 ▪ Neutrality: 3 ▪ Correctness: 5

8. Alt text **Short description (metadata):** Senkrecht gestapeltes Balkendiagramm. Titel: Der ANC erreichte seit den ersten freien Parlamentswahlen in Südafrika stets das absolute Mehr. Untertitel: in Prozent der Stimmen. Waagrechte Achse: 0 bis 100 Prozent. Senkrechte Achse: 1994, 1999, 2004, 2009, 2014, 2019. Segmente pro Balken: ANC (dunkelblau), andere Parteien (türkis). **Short description (overview):** Der ANC dominiert die Wahlen durchgehend, jedoch sinkt sein Stimmenanteil seit 2004 tendenziell, während der Anteil der anderen Parteien steigt. **Long description:** Der ANC starts 1994 mit 62.6 Prozent der Stimmen, erreicht den Höchstwert von 69.69 Prozent im Jahr 2004 und sinkt anschliessend kontinuierlich auf 57.7 Prozent im Jahr 2019. Die anderen Parteien beginnen bei 37.4 Prozent im Jahr 1994, erreichen ihren Tiefstwert 2004 (30.31 Prozent) und steigern sich bis 2019 auf 42.3 Prozent.	**SBERT:** 0.82 **LLM as Judge:** *(n=1)* ▪ Clarity: 4 ▪ Completeness: 3 ▪ Conciseness: 1 ▪ PC: 5 ▪ Neutrality: 5 ▪ Correctness: 4
9. Alt text **Short description (metadata):** Senkrecht gestapeltes Balkendiagramm. Titel: Der ANC erreichte seit den ersten freien Parlamentswahlen in Südafrika stets das absolute Mehr. Untertitel: in Prozent der Stimmen. Waagrechte Achse: 0 bis 100 Prozent Stimmen. Senkrechte Achse: 1994, 1999, 2004, 2009, 2014, 2019. Segmente pro Balken: ANC (dunkelblau), andere Parteien (türkis). **Short description (overview):** Der ANC hält seit 1994 die absolute Mehrheit der Stimmen, jedoch sinkt sein Stimmenanteil seit 2004 kontinuierlich. **Long description:** Der Stimmenanteil des ANC stieg von 62,6 Prozent im Jahr 1994 auf einen Höchststand von 69,69 Prozent im Jahr 2004. Danach sank der Anteil stetig bis auf 57,7 Prozent im Jahr 2019. Entsprechend stieg der Anteil der anderen Parteien von einem Tiefststand von 30,31 Prozent im Jahr 2004 auf 42,3 Prozent im Jahr 2019.	**SBERT:** 0.81 **LLM as Judge:** *(n=1)* ▪ Clarity: 2 ▪ Completeness: 2 ▪ Conciseness: 1 ▪ PC: 5 ▪ Neutrality: 5 ▪ Correctness: 3
10. Alt text **Short description (metadata):** Senkrecht gestapeltes Balkendiagramm. Titel: Der ANC erreichte seit den ersten freien Parlamentswahlen in Südafrika stets das absolute Mehr. Untertitel: in Prozent der Stimmen. Waagrechte Achse: 1994 bis 2019. Senkrechte Achse: 0 bis 100 Prozent. Segmente pro Balken: ANC (dunkelblau), andere Parteien (türkis). **Short description (overview):** Der ANC hält seit 1994 durchgehend die absolute Mehrheit der Stimmen, jedoch sinkt sein Stimmenanteil seit 2004. **Long description:** Der Stimmenanteil des ANC stieg von 62.6 Prozent im Jahr 1994 auf den Höhepunkt von 69.69 Prozent im Jahr 2004, und sank bis 2019 auf 57.7 Prozent ab. Der Anteil der anderen Parteien sank zunächst auf einen Tiefpunkt von 30.31 Prozent im Jahr 2004, und stieg bis 2019 auf 42.3 Prozent.	**SBERT:** 0.79 **LLM as Judge:** *(n=1)* ▪ Clarity: 5 ▪ Completeness: 3 ▪ Conciseness: 2 ▪ PC: 5 ▪ Neutrality: 5 ▪ Correctness: 5

015b1d1184288f807143043e2decb8b3

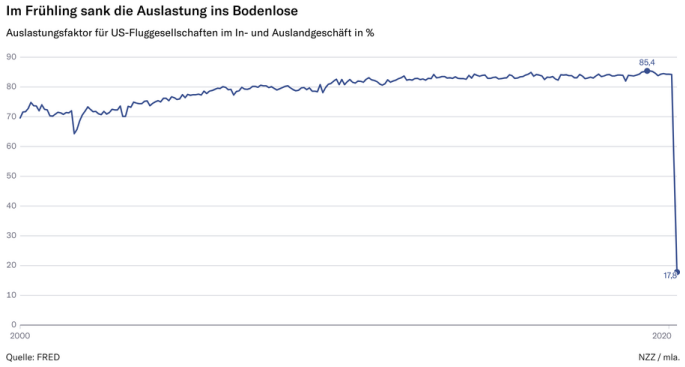

Golden standard

Short description (metadata): Liniendiagramm. Titel: Im Frühling sank die Auslastung ins Bodenlose. Untertitel: Auslastungsfaktor für US-Fluggesellschaften im In- und Auslandsgeschäft in %. Waagrechte Achse: Zeitraum Januar 2000 bis April 2020. Senkrechte Achse: 0 bis 90 %. Daten: Monatliche Werte.

Short description (overview): Die Auslastung steigt leicht über 20 Jahre hinweg, bevor sie in den letzten zwei Monaten stark sinkt.

Long description: Von Januar 2000 bis Februar 2020 steigt die Auslastung von rund 70 % auf rund 85 % dem Höchstwert. Im März 2020 sinkt die Auslastung auf knapp 51 % und im April 2020 auf knapp 18 %, den Tiefpunkt des gesamten Zeitraums.

1. Alt text **Short description (metadata):** Liniendiagramm. Titel: Im Frühling sank die Auslastung ins Bodenlose. Untertitel: Auslastungsfaktor für US-Fluggesellschaften im In- und Auslandgeschäft in Percentage. Waagrechte Achse: Zeitraum 2000 bis Mitte 2020. Senkrechte Achse: 0 bis 90 Percentage. Daten: Monatliche Werte. **Short description (overview):** Die Auslastung bewegt sich von 2000 bis Anfang 2020 mit leichten Schwankungen auf einem stabilen, langsam steigenden Niveau, bevor sie im Frühling 2020 drastisch sinkt. **Long description:** Von 2000 bis 2020 steigt die durchschnittliche Auslastung von rund 70 Percentage auf 84 Percentage, mit einem Höchstwert von 85,4 Percentage im Mai und Juni 2019. Die Auslastung sinkt im März 2020 auf 50,9 Percentage und fällt dann stark auf den Tiefstwert von 17,8 Percentage im April 2020.	**SBERT:** 0.85 **LLM as Judge:** *(n=1)* ▪ Clarity: 4 ▪ Completeness: 4 ▪ Conciseness: 2 ▪ PC: 5 ▪ Neutrality: 2 ▪ Correctness: 5
2. Alt text **Short description (metadata):** Liniendiagramm. Titel: Im Frühling sank die Auslastung ins Bodenlose. Untertitel: Auslastungsfaktor für US-Fluggesellschaften im In- und Auslandgeschäft in %. Waagrechte Achse: Zeitraum 2000 bis 2020. Senkrechte Achse: Auslastungsfaktor von 0 bis 90 %. Daten: Monatliche Werte. **Short description (overview):** Der Auslastungsfaktor weist von 2000 bis Anfang 2020 einen stetigen Anstieg mit Schwankungen auf und sinkt im Frühjahr 2020 drastisch. **Long description:** Der Auslastungsfaktor schwankt zwischen 64 % (September 2001) und 85.4 % (Mai/Juni 2019) und bewegte sich bis Anfang 2020 mehrheitlich zwischen 70 % und 85 %. Im Februar 2020 liegt der Wert bei 84.2 % und sinkt auf 50.9 % im März. Im April 2020 sinkt er weiter auf einen Tiefstwert von 17.8 %.	**SBERT:** 0.84 **LLM as Judge:** *(n=1)* ▪ Clarity: 5 ▪ Completeness: 5 ▪ Conciseness: 2 ▪ PC: 5 ▪ Neutrality: 2 ▪ Correctness: 5

3. Alt text **Short description (metadata):** Liniendiagramm. Titel: Im Frühling sank die Auslastung ins Bodenlose. Untertitel: Auslastungsfaktor für US-Fluggesellschaften im In- und Auslandgeschäft in %. Waagrechte Achse: Zeitraum 2000 bis 2020. Senkrechte Achse: (Ausschnitt) 0 bis 90 %. Daten: Monatlich Werte. **Short description (overview):** Von 2000 bis Anfang 2020 steigt der Auslastungsfaktor von US-Fluggesellschaften tendenziell mit Schwankungen, bevor er im Frühling 2020 stark sinkt. **Long description:** Der Auslastungsfaktor beveg sich von 2000 bis Anfang 2020 zwischen rund 64 und 85 Prozent. Im Mai 2019 steigt er auf den Höchstwert von 85.4 Prozent. Im Februar 2020 liegt er bei 84.2 Prozent, sinkt scharf auf 50.9 Prozent im März und auf den Tiefpunkt von 17.8 Prozent im April 2020.	**SBERT:** 0.8 **LLM as Judge:** *(n=1)* ▪ Clarity: 4 ▪ Completeness: 4 ▪ Conciseness: 2 ▪ PC: 5 ▪ Neutrality: 2 ▪ Correctness: 5
4. Alt text **Short description (metadata):** Liniendiagramm. Titel: Im Frühling sank die Auslastung ins Bodenlose. Untertitel: Auslastungsfaktor für US-Fluggesellschaften im In und Auslandgeschäft in %. Waagrechte Achse: Zeitraum 2000 bis 2020. Senkrechte Achse: Ausschnitt 0 bis 90 Prozent. Daten: Monatliche Werte. **Short description (overview):** Der Auslastungsfaktor steigt von 2000 bis 2019 stetig, erreicht einen Höhepunkt und sinkt dann im Frühjahr 2020 dramatisch. **Long description:** Der Auslastungsfaktor schwankt zwischen 64 Prozent (September 2001) und rund 75 Prozent bis 2004. Bis 2019 steigt er tendenziell auf das Maximum von 85,4 Prozent (Mai/Juni 2019, Januar/Februar 2020). Im März 2020 sinkt er auf 50,9 Prozent und im April 2020 auf den Tiefstwert von 17,8 Prozent.	**SBERT:** 0.79 **LLM as Judge:** *(n=1)* ▪ Clarity: 5 ▪ Completeness: 5 ▪ Conciseness: 2 ▪ PC: 5 ▪ Neutrality: 1 ▪ Correctness: 3
5. Alt text **Short description (metadata):** Liniendiagramm. Titel: Im Frühling sank die Auslastung ins Bodenlose. Untertitel: Auslastungsfaktor für US-Fluggesellschaften im In- und Auslandgeschäft in %. Waagrechte Achse: Zeitraum 2000 bis 2020. Senkrechte Achse: Auslastung von 0 bis 90 Prozent. Daten: Monatliche Werte. Markierungen: 85,4 % (Höchstwert Mai und Juni 2019) und 17,8 % (Tiefstwert April 2020). **Short description (overview):** Die Auslastung schwankt zwischen 2000 und 2019 auf einem Niveau von 65 bis 85 Prozent, steigt insgesamt leicht an und bricht im Frühjahr 2020 stark ein. **Long description:** Von 2000 bis Februar 2020 schwankt die Auslastung überwiegend zwischen 70 und 85 Prozent mit einem steigenden Trend. Der Höchstwert von 85,4 Prozent wird im Mai und Juni 2019 erreicht. Im März 2020 sinkt die Auslastung auf 50,9 Prozent und im April 2020 weiter stark auf den Tiefstwert von 17,8 Prozent.	**SBERT:** 0.78 **LLM as Judge:** *(n=1)* ▪ Clarity: 5 ▪ Completeness: 5 ▪ Conciseness: 2 ▪ PC: 5 ▪ Neutrality: 2 ▪ Correctness: 4

6. Alt text **Short description (metadata):** Liniendiagramm. Titel: Im Frühling sank die Auslastung ins Bodenlose. Untertitel: Auslastungsfaktor für US-Fluggesellschaften im In- und Auslandgeschäft in %. Waagrechte Achse: Zeitraum 2000 bis 2020. Senkrechte Achse: (Ausschnitt) 0 bis 90 Prozent. Daten: Monatliche Werte. **Short description (overview):** Der Auslastungsfaktor stieg von 2000 bis Anfang 2020 mit Schwankungen an und sank im Frühjahr 2020 stark ab. **Long description:** Von 2000 bis Anfang 2020 stieg die Auslastung von rund 70 Prozent auf einen Höchstwert von 85,4 Prozent im Mai/Juni 2019 an. Der Wert schwankte in dieser Zeit, wobei der Tiefstwert bei 64,3 Prozent im September 2001 lag. Anfang 2020 sank die Auslastung stark von den Höchstwerten (84,2 Prozent im Februar) auf 17,8 Prozent im April 2020.	**SBERT:** 0.77 **LLM as Judge:** *(n=1)* ▪ Clarity: 5 ▪ Completeness: 5 ▪ Conciseness: 1 ▪ PC: 5 ▪ Neutrality: 2 ▪ Correctness: 5
7. Alt text **Short description (metadata):** Liniendiagramm. Titel: Im Frühling sank die Auslastung ins Bodenlose. Untertitel: Auslastungsfaktor für US-Fluggesellschaften im In- und Auslandgeschäft in %. Waagrechte Achse: Zeitraum 2000 bis 2020. Senkrechte Achse: Auslastungsfaktor 0 bis 90 Prozent. Daten: Monatliche Werte. **Short description (overview):** Der Auslastungsfaktor zeigt von 2000 bis 2019 einen schwankenden, aber stetigen Anstieg, bevor er im Frühjahr 2020 stark sinkt. **Long description:** Ab 2000 (ca. 70 Prozent) steigt der Auslastungsfaktor mit leichten Schwankungen bis Mai/Juni 2019 auf den Höchststand von 85,4 Prozent. Die Werte bleiben bis Februar 2020 auf einem ähnlichen Niveau. Im März 2020 sinkt der Wert abrupt auf 50,9 Prozent und im April 2020 auf den Tiefstwert von 17,8 Prozent.	**SBERT:** 0.76 **LLM as Judge:** *(n=1)* ▪ Clarity: 5 ▪ Completeness: 5 ▪ Conciseness: 2 ▪ PC: 5 ▪ Neutrality: 2 ▪ Correctness: 5
8. Alt text **Short description (metadata):** Liniendiagramm. Titel: Im Frühling sank die Auslastung ins Bodenlose. Untertitel: Auslastungsfaktor für US-Fluggesellschaften im In- und Auslandgeschäft in %. Waagrechte Achse: Zeitraum 2000 bis 2020. Senkrechte Achse: Auslastungsfaktor von 0 bis 90 Prozent. Daten: Monatliche Werte. Markierungen: Der letzte Wert 17,8 und der Höchstwert 85,4 sind markiert und beschriftet. **Short description (overview):** Von 2000 bis Anfang 2020 steigt der Auslastungsfaktor der US-Fluggesellschaften tendenziell mit Schwankungen, bevor er im Frühjahr 2020 extrem stark sinkt. **Long description:** Der Auslastungsfaktor schwankt ab Jahr 2000 zwischen 65 Prozent (September 2001) und rund 75 Prozent bis 2004. Von 2005 bis Anfang 2020 steigt der Wert mit Schwankungen auf den Höchststand von 85,4 Prozent (Mai/Juni 2019). Nach einem leichten Sinken Anfang 2020 bricht der Wert im März (50,9 Prozent) und April 2020 stark ein auf 17,8 Prozent.	**SBERT:** 0.75 **LLM as Judge:** *(n=1)* ▪ Clarity: 5 ▪ Completeness: 5 ▪ Conciseness: 2 ▪ PC: 5 ▪ Neutrality: 2 ▪ Correctness: 5

9. Alt text **Short description (metadata):** Liniendiagramm. Titel: Im Frühling sank die Auslastung ins Bodenlose. Untertitel: Auslastungsfaktor für US-Fluggesellschaften im In- und Auslandgeschäft in %. Waagrechte Achse: Zeitraum 2000 bis 2020. Senkrechte Achse: Ausschnitt von 0 bis 90 Prozent. Daten: Monatliche Werte. **Short description (overview):** Der Auslastungsfaktor bewegt sich von 2000 bis Anfang 2020 mit leichten Schwankungen hauptsächlich zwischen 70 Prozent und 85 Prozent. Im Frühjahr 2020 sinkt der Faktor drastisch auf ein Minimum. **Long description:** Von 2000 bis einschliesslich Februar 2020 liegt der Auslastungsfaktor zwischen 64,3 Prozent (September 2001) und 85,4 Prozent (Mai/Juni 2019). Im März 2020 sinkt er zunächst auf 50,9 Prozent und im April 2020 auf den Tiefstwert von 17,8 Prozent.	**SBERT:** 0.73 **LLM as Judge:** *(n=1)* ▪ Clarity: 5 ▪ Completeness: 5 ▪ Conciseness: 2 ▪ PC: 5 ▪ Neutrality: 2 ▪ Correctness: 5
10. Alt text **Short description (metadata):** Liniendiagramm. Titel: Im Frühling sank die Auslastung ins Bodenlose. Untertitel: Auslastungsfaktor für US-Fluggesellschaften im In- und Auslandgeschäft in %. Waagrechte Achse: Zeitraum 2000 bis 2020. Senkrechte Achse: Auslastung von 0 bis 90 Prozent. Daten: Monatliche Werte. Markierungen: Der Höchstwert von 85.4 Prozent (Mai 2019 bis Juni 2019) und der Tiefstwert von 17.8 Prozent (April 2020) sind markiert. **Short description (overview):** Von 2000 bis 2019 steigt der Auslastungsfaktor der US-Fluggesellschaften mit Schwankungen. Im Frühjahr 2020 sinkt der Auslastungsfaktor sprunghaft. **Long description:** Von 2000 (rund 70 Prozent) steigt der Auslastungsfaktor mit Schwankungen bis zum Höchstwert von 85.4 Prozent im Mai/Juni 2019. Die Werte bleiben durchgehend zwischen 64.3 Prozent (September 2001) und 85.4 Prozent. Im Februar 2020 liegt der Wert bei 84.2 Prozent, sinkt im März auf 50.9 Prozent und erreicht im April 2020 den Tiefstwert von 17.8 Prozent.	**SBERT:** 0.72 **LLM as Judge:** *(n=1)* ▪ Clarity: 5 ▪ Completeness: 5 ▪ Conciseness: 1 ▪ PC: 5 ▪ Neutrality: 3 ▪ Correctness: 5

022a672b3f9fa2b1be4ea3c48a553889

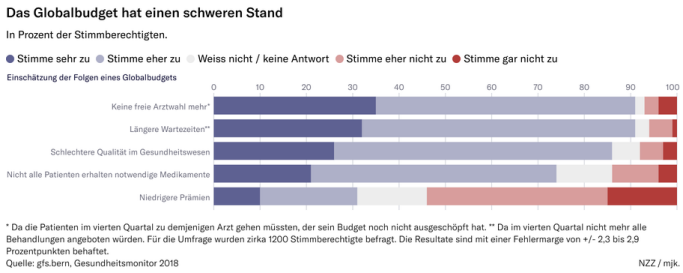

Golden standard

Short description (metadata): Waagrechtes Balkendiagramm. Titel: Das Globalbudget hat einen schweren Stand. Untertitel: in Prozent der Stimmberechtigten. Waagrechte Achse: 0 bis 100 Prozent. Senkrechte Achse: Keine freie Arztwahl mehr (Da die Patienten im vierten Quartal zu demjenigen Arzt gehen müssten, der sein Budget noch nicht ausgeschöpft hat.), Längere Wartezeiten (Da im vierten Quartal nicht mehr alle Behandlungen angeboten würden.), Schlechtere Qualität im Gesundheitswesen, Nicht alle Patienten erhalten notwendige Medikamente, Niedrigere Prämien. Pro Folge des Globaldbudgets ein Balken unterteilt in fünf Anteile: Stimme sehr zu, Stimme eher zu, Weiss nicht/keine Antwort, Stimme eher nicht zu, Stimme gar nicht zu.

Short description (overview): Klare Mehrheit erwartet negative Folgen (eingeschränkte Arztwahl, längere Wartezeiten, schlechtere Qualität, eingeschränkter Zugang zu Medikamenten), während niedrigere Prämien mehrheitlich verneint wird.

Long description: Die Grafik zeigt, wie rund 1.200 Stimmberechtigte die Folgen eines Globalbudgets einschätzen (Gesundheitsmonitor 2018; Fehlermarge ±2,3 bis 2,9 Prozentpunkte). Anteile, die einer Aussage sehr oder eher zustimmen: Keine freie Arztwahl mehr: 91 %. Längere Wartezeiten: 91 %. Schlechtere Qualität im Gesundheitswesen: 86 %. Nicht alle Patienten erhalten notwendige Medikamente: 74 %. Niedrigere Prämien: 31 %.

1. Alt text	**SBERT:** 0.85
Short description (metadata): Waagrecht gestapeltes Balkendiagramm. Titel: Das Globalbudget hat einen schweren Stand. Untertitel: In Prozent der Stimmberechtigten. Waagrechte Achse: Kategorien: Keine freie Arztwahl mehr*, Längere Wartezeiten**, Schlechtere Qualität im Gesundheitswesen, Nicht alle Patienten erhalten notwendige Medikamente, Niedrigere Prämien. Senkrechte Achse: null bis 100 Prozent. Segmente pro Balken: Stimme sehr zu (dunkelblau), Stimme eher zu (hellblau), Weiss nicht / keine Antwort (hellgrau), Stimme eher nicht zu (rosa), Stimme gar nicht zu (dunkelrot). **Short description (overview):** Die Zustimmung ('Stimme sehr zu' und 'Stimme eher zu') zu den negativen Folgen eines Globalbudgets ist bei den ersten vier Kategorien sehr hoch (zwischen 74 und 91 Prozent), während die Zustimmung zur positiven Folge ('Niedrigere Prämien') mit 31 Prozent deutlich am geringsten ist. **Long description:** Der höchste Zustimmungsanteil liegt bei "Keine freie Arztwahl mehr*" mit 91 Prozent, gefolgt von "Längere Wartezeiten**" (91 Prozent) und "Schlechtere Qualität im Gesundheitswesen" (86 Prozent). Bei "Nicht alle Patienten erhalten notwendige Medikamente" beträgt der Zustimmungsanteil 74 Prozent. "Niedrigere Prämien" zeigt das umgekehrte Bild: Die Ablehnung ('Stimme eher nicht zu' und 'Stimme gar nicht zu') liegt hier bei 54 Prozent, die Zustimmung bei 31 Prozent. Der Anteil der Unschlüssigen ist bei "Niedrigere Prämien" mit 15 Prozent am höchsten.	**LLM as Judge:** *(n=1)* ▪ Clarity: 3 ▪ Completeness: 3 ▪ Conciseness: 2 ▪ PC: 5 ▪ Neutrality: 3 ▪ Correctness: 4

2. Alt text **Short description (metadata):** Waagrecht gestapeltes Balkendiagramm. Titel: Das Globalbudget hat einen schweren Stand. Untertitel: In Prozent der Stimmberechtigten. Waagrechte Achse: Kategorien: Einschätzung der Folgen eines Globalbudgets (Keine freie Arztwahl mehr*, Längere Wartezeiten**, Schlechtere Qualität im Gesundheitswesen, Nicht alle Patienten erhalten notwendige Medikamente, Niedrigere Prämien). Senkrechte Achse: 0 bis 100 Prozent. Segmente pro Balken: Stimme sehr zu (dunkelblau), Stimme eher zu (hellblau), Weiss nicht / keine Antwort (beige), Stimme eher nicht zu (rosa), Stimme gar nicht zu (weinrot). **Short description (overview):** Bei den vier Risikofolgen des Globalbudgets stimmen über 80 Prozent zu, wobei bei "Keine freie Arztwahl mehr*" und "Längere Wartezeiten**" die Zustimmung am höchsten ist. "Niedrigere Prämien" wird von den Befragten am kritischsten gesehen. **Long description:** Die höchste Zustimmungsrate findet sich bei „Keine freie Arztwahl mehr*“ und „Längere Wartezeiten**“ mit 91 Prozent. Die Zustimmung für "Schlechtere Qualität im Gesundheitswesen" liegt bei 86 Prozent und für "Nicht alle Patienten erhalten notwendige Medikamente" bei 74 Prozent. "Niedrigere Prämien" wird von 31 Prozent befürwortet, während 54 Prozent ablehnen, mit einer höchsten Ablehnungsrate bei "Stimme eher nicht zu".	**SBERT:** 0.85 **LLM as Judge:** *(n=1)* ▪ Clarity: 4 ▪ Completeness: 2 ▪ Conciseness: 2 ▪ PC: 5 ▪ Neutrality: 3 ▪ Correctness: 3
3. Alt text **Short description (metadata):** Waagrecht gestapeltes Balkendiagramm. Titel: Das Globalbudget hat einen schweren Stand. Untertitel: In Prozent der Stimmberechtigten. Waagrechte Achse: Kategorien: Keine freie Arztwahl mehr*, Längere Wartezeiten**, Schlechtere Qualität im Gesundheitswesen, Nicht alle Patienten erhalten notwendige Medikamente, Niedrigere Prämien. Senkrechte Achse: Null bis Einhundert Prozent. Segmente pro Balken: Stimme sehr zu (dunkelblau), Stimme eher zu (hellblau), Weiss nicht / keine Antwort (grau), Stimme eher nicht zu (rosa), Stimme gar nicht zu (dunkelrot). **Short description (overview):** Die Zustimmung zu den negativen Folgen eines Globalbudgets ist bei den ersten vier Kategorien sehr hoch (über neunzig Prozent). Nur bei den niedrigeren Prämien überwiegt die Ablehnung (vierundfünfzig Prozent). **Long description:** Die Zustimmung (Stimme sehr zu und Stimme eher zu) ist bei den Kategorien keine freie Arztwahl mehr (einundneunzig Prozent), längere Wartezeiten (einundneunzig Prozent), und schlechtere Qualität im Gesundheitswesen (sechsundachtzig Prozent) am höchsten. Die Ablehnung (Stimme eher nicht zu und Stimme gar nicht zu) ist bei niedrigeren Prämien am höchsten (vierundfünfzig Prozent). Die Kategorie nicht alle Patienten erhalten notwendige Medikamente liegt mit vierundsiebzig Prozent für die Zustimmung und vierzehn Prozent für die Ablehnung in der Mitte.	**SBERT:** 0.85 **LLM as Judge:** *(n=1)* ▪ Clarity: 2 ▪ Completeness: 3 ▪ Conciseness: 1 ▪ PC: 2 ▪ Neutrality: 5 ▪ Correctness: 2

4. Alt text **Short description (metadata):** Waagrecht gestapeltes Balkendiagramm. Titel: Das Globalbudget hat einen schweren Stand. Untertitel: In Prozent der Stimmberechtigten. Waagrechte Achse: Kategorien: Keine freie Arztwahl mehr*, Längere Wartezeiten**, Schlechte Qualität im Gesundheitswesen, Nicht alle Patienten erhalten notwendige Medikamente, Niedrigere Prämien. Senkrechte Achse: null bis einhundert Prozent. Segmente pro Balken: Stimme sehr zu (dunkelblau), Stimme eher zu (hellblau), Weiss nicht/keine Antwort (weiss), Stimme eher nicht zu (hellrot), Stimme gar nicht zu (dunkelrot). **Short description (overview):** Die Zustimmung ("Stimme sehr zu" und "Stimme eher zu") ist bei den ersten vier genannten Auswirkungen des Globalbudgets sehr hoch und liegt zwischen 74 und 91 Prozent. Nur bei "Niedrigere Prämien" dominiert die Ablehnung ("Stimme eher nicht zu" und "Stimme gar nicht zu") mit 54 Prozent. **Long description:** Die höchste Zustimmung ("sehr zu" und "eher zu") wird mit 91 Prozent bei "Keine freie Arztwahl mehr*", gefolgt von 91 Prozent bei "Längere Wartezeiten**" und 86 Prozent bei "Schlechtere Qualität im Gesundheitswesen" sowie 74 Prozent bei "Nicht alle Patienten erhalten notwendige Medikamente" verzeichnet. Das stärkste Segment ist "Stimme eher zu" bei den ersten vier Kategorien (zwischen 53 und 60 Prozent). Für "Niedrigere Prämien" zeigen nur 31 Prozent Zustimmung, während 54 Prozent die Wahrscheinlichkeit für eher nicht zutreffend halten.	**SBERT:** 0.84 **LLM as Judge:** *(n=1)* ▪ Clarity: 4 ▪ Completeness: 3 ▪ Conciseness: 1 ▪ PC: 5 ▪ Neutrality: 5 ▪ Correctness: 5
5. Alt text **Short description (metadata):** Waagrecht gestapeltes Balkendiagramm. Titel: Das Globalbudget hat einen schweren Stand. Untertitel: In Prozent der Stimmberechtigten.. Waagrechte Achse: 0 bis 100 Prozent. Senkrechte Achse: Fünf Kategorien (Keine freie Arztwahl mehr*, Längere Wartezeiten**, Schlechtere Qualität im Gesundheitswesen, Nicht alle Patienten erhalten notwendige Medikamente, Niedrigere Prämien). Segmente pro Balken: Stimme sehr zu (dunkelblau), Stimme eher zu (hellblau), Weiss nicht / keine Antwort (beige), Stimme eher nicht zu (hellrot), Stimme gar nicht zu (dunkelrot). **Short description (overview):** Eine Mehrheit der Stimmberechtigten befürchtet negative Folgen eines Globalbudgets, wobei die grösste Zustimmung bei "Keine freie Arztwahl mehr" mit 91 Prozent liegt. Die positiven Erwartungen (Niedrigere Prämien) finden deutlich weniger Zuspruch. **Long description:** Die Zustimmung zu negativen Folgen ist hoch: "Keine freie Arztwahl mehr" (91 Prozent Zustimmung), "Längere Wartezeiten" (91 Prozent Zustimmung) und "Schlechtere Qualität im Gesundheitswesen" (86 Prozent Zustimmung) dominieren. 74 Prozent stimmen der Befürchtung zu, dass nicht alle Patienten notwendige Medikamente erhalten. Die Erwartung niedrigerer Prämien erhält nur 31 Prozent Zustimmung, während 54 Prozent dies ablehnen.	**SBERT:** 0.83 **LLM as Judge:** *(n=1)* ▪ Clarity: 5 ▪ Completeness: 2 ▪ Conciseness: 1 ▪ PC: 5 ▪ Neutrality: 3 ▪ Correctness: 5

6. Alt text **Short description (metadata):** Waagrecht gestapeltes Balkendiagramm. Titel: Das Globalbudget hat einen schweren Stand. Untertitel: In Prozent der Stimmberechtigten. Waagrechte Achse: Kategorien: Keine freie Arztwahl mehr*, Längere Wartezeiten**, Schlechtere Qualität im Gesundheitswesen, Nicht alle Patienten erhalten notwendige Medikamente, Niedrigere Prämien. Senkrechte Achse: 0 bis 100 Prozent. Segmente pro Balken: Stimme sehr zu (dunkellila), Stimme eher zu (helllila), Weiss nicht / keine Antwort (hellgrau), Stimme eher nicht zu (hellrot), Stimme gar nicht zu (dunkelrot). **Short description (overview):** Die Zustimmung ("Stimme sehr zu" und "Stimme eher zu") zu negativen Folgen eines Globalbudgets ("Keine freie Arztwahl mehr*", "Längere Wartezeiten**", "Schlechtere Qualität im Gesundheitswesen", "Nicht alle Patienten erhalten notwendige Medikamente") dominiert deutlich mit Werten zwischen siebzigvier und neunzigneun Prozent. Nur bei "Niedrigere Prämien" überwiegt die Ablehnung der Aussage. **Long description:** Die höchste Zustimmung ("Stimme sehr zu" und "Stimme eher zu") findet sich bei den Aussagen "Keine freie Arztwahl mehr*" mit neunzigneun Prozent und "Längere Wartezeiten**" mit einundneunzig Prozent. Die Aussage "Nicht alle Patienten erhalten notwendige Medikamente" weist mit vierzehn Prozent den grössten Anteil an "Weiss nicht / keine Antwort" auf. Die einzige Aussage, bei der die Ablehnung ("Stimme eher nicht zu" und "Stimme gar nicht zu") überwiegt, ist "Niedrigere Prämien" mit einem Gesamtwert von vierundfünfzig Prozent.	**SBERT:** 0.83 **LLM as Judge:** *(n=1)* ▪ Clarity: 4 ▪ Completeness: 2 ▪ Conciseness: 2 ▪ PC: 5 ▪ Neutrality: 5 ▪ Correctness: 1
7. Alt text **Short description (metadata):** Waagrechtes gestapeltes Balkendiagramm. Titel: Das Globalbudget hat einen schweren Stand. Untertitel: In Prozent der Stimmberechtigten. Waagrechte Achse: 0 bis 100 Prozent. Senkrechte Achse: Fünf Kategorien zur Einschätzung der Folgen eines Globalbudgets. Segmente pro Balken: Stimme sehr zu (dunkelblau), Stimme eher zu (hellblau), Weiss nicht / keine Antwort (beige), Stimme eher nicht zu (rosa), Stimme gar nicht zu (rot). **Short description (overview):** Die Zustimmung (sehr zu und eher zu) zu negativen Folgen eines Globalbudgets überwiegt bei den ersten vier Kategorien deutlich, mit Zustimmungsraten von 74 bis 91 Prozent. Nur bei „Niedrigere Prämien“ überwiegt die Ablehnung (eher nicht zu und gar nicht zu) mit 54 Prozent. **Long description:** „Keine freie Arztwahl mehr“ und „Längere Wartezeiten“ verzeichnen mit 91 Prozent bzw. 92 Prozent die höchsten Zustimmungsraten. „Schlechtere Qualität im Gesundheitswesen“ folgt mit 86 Prozent. „Nicht alle Patienten erhalten notwendige Medikamente“ stimmen 74 Prozent zu. Bei „Niedrigere Prämien“ lehnen 54 Prozent die erwartete Folge ab, während 31 Prozent zustimmen. Die höchsten Werte für „Stimme sehr zu“ sind bei den ersten beiden Kategorien mit 35 Prozent bzw. 32 Prozent zu finden.	**SBERT:** 0.75 **LLM as Judge:** *(n=1)* ▪ Clarity: 5 ▪ Completeness: 4 ▪ Conciseness: 2 ▪ PC: 5 ▪ Neutrality: 5 ▪ Correctness: 3

8. Alt text **Short description (metadata):** Waagrecht gestapeltes Balkendiagramm. Titel: Das Globalbudget hat einen schweren Stand. Untertitel: In Prozent der Stimmberechtigten. Waagrechte Achse: Kategorien: Einschätzung der Folgen eines Globalbudgets. Senkrechte Achse: Null bis einhundert Prozent. Segmente pro Balken: Stimme sehr zu (dunkel-blau), Stimme eher zu (hell-blau), Weiss nicht / keine Antwort (hell-grau), Stimme eher nicht zu (hell-rot), Stimme gar nicht zu (dunkel-rot). **Short description (overview):** Die Zustimmung ("Stimme sehr zu" und "Stimme eher zu") zu den negativen Folgen eines Globalbudgets ist bei den meisten Punkten sehr hoch und übersteigt neunzig Prozent bei "Keine freie Arztwahl mehr" und "Längere Wartezeiten". Nur beim möglichen positiven Effekt, den "Niedrigere Prämien", ist die Zustimmung mit einunddreissig Prozent deutlich geringer, wohingegen die Ablehnung (\{}"Stimme eher nicht zu\{}" und \{}"Stimme gar nicht zu\{}") mit vierundfünfzig Prozent dominiert. **Long description:** Die höchste Zustimmung (\{}"Stimme sehr zu\{}" und \{}"Stimme eher zu\{}") findet sich bei "Keine freie Arztwahl mehr" mit einundneunzig Prozent und "Längere Wartezeiten" mit einundneunzig Prozent. Es folgen "Schlechtere Qualität im Gesundheitswesen" mit sechsundachtzig Prozent und "Nicht alle Patienten erhalten notwendige Medikamente" mit vierundsiebzig Prozent. Die Kategorie mit der geringsten Zustimmung ist "Niedrigere Prämien" mit einunddreissig Prozent, während die Ablehnung (\{}"Stimme eher nicht zu\{}" und \{}"Stimme gar nicht zu\{}") hier mit vierundfünfzig Prozent am höchsten ist.	**SBERT:** 0.73 **LLM as Judge:** *(n=1)* ▪ Clarity: 4 ▪ Completeness: 2 ▪ Conciseness: 1 ▪ PC: 5 ▪ Neutrality: 5 ▪ Correctness: 3
9. Alt text **Short description (metadata):** Waagrecht gestapeltes Balkendiagramm. Titel: Das Globalbudget hat einen schweren Stand. Untertitel: In Prozent der Stimmberechtigten. Waagrechte Achse: Kategorien: Einschätzung der Folgen eines Globalbudgets (fünf Kategorien). Senkrechte Achse: null bis 100 Prozent. Segmente pro Balken: Stimme sehr zu (dunkelblau), Stimme eher zu (hellblau), Weiss nicht / keine Antwort (beige), Stimme eher nicht zu (hellrot), Stimme gar nicht zu (dunkelrot). **Short description (overview):** Die Zustimmung, dass ein Globalbudget negative Folgen haben wird, ist bei den ersten vier genannten Auswirkungen hoch: Über 74% stimmen dem zu. Bei der positiven Erwartung auf niedrigere Prämien (31%) ist die Ablehnung hoch (54%). **Long description:** „Keine freie Arztwahl mehr“ (91%), „Längere Wartezeiten“ (91%) und „Schlechtere Qualität im Gesundheitswesen“ (86%) weisen die höchste Zustimmung auf, wobei die Kategorie „Stimme eher zu“ (56 bis 60%) dominiert. „Nicht alle Patienten erhalten notwendige Medikamente“ hat 74% Zustimmung. Die erste positive Folge „Niedrigere Prämien“ hat die geringste Zustimmung (31%), wobei hier „Stimme eher nicht zu“ mit 39% das grösste Segment darstellt. Die Verteilung der Ablehnung (3% bis 14%) und „Weiss nicht / keine Antwort“ (2% bis 15%) ist uneinheitlich.	**SBERT:** 0.72 **LLM as Judge:** *(n=1)* ▪ Clarity: 3 ▪ Completeness: 2 ▪ Conciseness: 1 ▪ PC: 5 ▪ Neutrality: 5 ▪ Correctness: 2

10. Alt text	SBERT: 0.68
Short description (metadata): Waagrecht gestapeltes Balkendiagramm. Titel: Das Globalbudget hat einen schweren Stand. Untertitel: In Prozent der Stimmberechtigten. Die waagrechte Achse zeigt die Skala von null bis 100 Prozent. Die senkrechte Achse listet fünf Kategorien (Einschätzung der Folgen eines Globalbudgets). Segmente pro Balken: Stimme sehr zu (dunkelblau), Stimme eher zu (hellblau), Weiss nicht / keine Antwort (beige), Stimme eher nicht zu (hellrot), Stimme gar nicht zu (dunkelrot). **Short description (overview):** Die Zustimmung (Stimme sehr zu und Stimme eher zu) zur Einschätzung negativer Folgen eines Globalbudgets ist bei den ersten vier Punkten sehr hoch (bis zu 91 Prozent). Nur beim Punkt "Niedrigere Prämien" dominiert die Ablehnung (Stimme eher nicht zu und Stimme gar nicht zu) mit 54 Prozent. **Long description:** Die höchste Zustimmung zur Einschätzung negativer Folgen erzielt "Keine freie Arztwahl mehr" mit 91 Prozent (35 Prozent Stimme sehr zu, 56 Prozent Stimme eher zu), gefolgt von "Längere Wartezeiten" mit 91 Prozent (32 Prozent Stimme sehr zu, 59 Prozent Stimme eher zu) und "Schlechtere Qualität im Gesundheitswesen" mit 86 Prozent (26 Prozent Stimme sehr zu, 60 Prozent Stimme eher zu). "Nicht alle Patienten erhalten notwendige Medikamente" weist eine Zustimmung von 74 Prozent auf. Die Ablehnung ist am höchsten bei "Niedrigere Prämien" mit 54 Prozent.	**LLM as Judge:** *(n=1)* ▪ Clarity: 5 ▪ Completeness: 2 ▪ Conciseness: 2 ▪ PC: 5 ▪ Neutrality: 4 ▪ Correctness: 5

016934e7c13b1b546fdea80efd7b5963

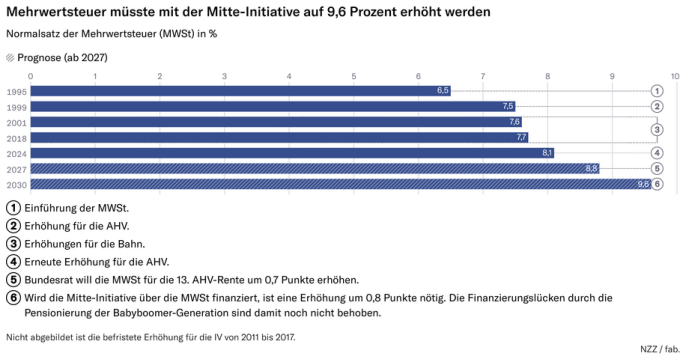

Golden standard

Short description (metadata): Waagrechtes Balkendiagramm. Titel: Mehrwertsteuer müsste mit der Mitte-Initiative auf 9,6 Prozent erhöht werden. Untertitel: Normalsatz der Mehrwertsteuer (MWSt) in %. Waagrechte Achse: 0 bis 10 Prozent. Senkrechte Achse: 1995, 1999, 2001, 2018, 2024, 2027 und 2030. Prognosen ab 2027. Pro Balken ist ein Ereignis erwähnt. Nicht abgebildet ist die befristete Erhöhung für die IV von 2011 bis 2017.

Short description (overview): Seit der Einführung der Mehrwertsteuer im Jahr 1995 ist sie kontinuierlich gestiegen. Auch die Prognosen sind steigend.

Long description: 1995 wird die Mehrwertsteuer mit einem Satz von 6.5 Prozent eingeführt. Mit der Erhöhung der AHV wird sie 1999 auf 7.5 Prozent erhöht. Mit der Erhöhung der Bahn- und AHV-Beiträge steigt sie bis 2024 auf 8.1 Prozent. Für die 13. AHV-Rente will der Bundesrat die Mehrwertsteuer bis 2027 um 0.7 Prozent erhöhen (auf 8.8). Wird die Mitte-Initiative über die Mehrwertsteuer finanziert, ist eine Erhöhung auf 9.6% nötig. Die Finanzierungslücken durch die Pensionierung der Babyboomer-Generation sind damit noch nicht behoben.

1. Alt text **Short description (metadata):** Waagerechtes Balkendiagramm. Titel: Mehrwertsteuer müsste mit der Mitte-Initiative auf 9,6 Prozent erhöht werden. Untertitel: Normalsatz der Mehrwertsteuer (MWSt) in %. Waagerechte Achse: (Ausschnitt) 0 bis 10 Prozent. Senkrechte Achse: 1995, 1999, 2001, 2018, 2024, 2027, 2030. **Short description (overview):** Der Normalsatz der Mehrwertsteuer steigt stetig von 6,5 Prozent im Jahr 1995 auf prognostizierte 9,6 Prozent im Jahr 2030. **Long description:** Der Normalsatz der Mehrwertsteuer steigt kontinuierlich von 6,5 Prozent (1995) auf 7,5 (1999), 7,6 (2001) und 7,7 Prozent (2018). Eine weitere Erhöhung auf 8,1 Prozent ist für 2024 geplant, 8,8 Prozent für 2027 und 9,6 Prozent bis 2030.	**SBERT:** 0.84 **LLM as Judge:** *(n=1)* ▪ Clarity: 5 ▪ Completeness: 3 ▪ Conciseness: 2 ▪ PC: 5 ▪ Neutrality: 5 ▪ Correctness: 5
2. Alt text **Short description (metadata):** Waagerechtes Balkendiagramm. Titel: Mehrwertsteuer müsste mit der Mitte-Initiative auf 9,6 Prozent erhöht werden. Untertitel: Normalsatz der Mehrwertsteuer (MWSt) in %. Waagrechte Achse: (Ausschnitt) 0 bis 10 Prozent. Senkrechte Achse: 1995, 1999, 2001, 2018, 2024, 2027, 2030. **Short description (overview):** Der Normalsatz der Mehrwertsteuer steigt stetig von 6,5% in 1995 auf prognostizierte 9,6% in 2030. Die Erhöhungen sind an spezifische Ereignisse gekoppelt. **Long description:** Der Normalsatz steigt von 6,5 Prozent in 1995, über 7,5 Prozent in 1999 auf 7,7 Prozent in 2018. Er steigt weiter auf 8,1 Prozent in 2024, 8,8 Prozent in 2027 und erreicht 9,6 Prozent in 2030, wobei die letzten beiden Jahre Prognosen darstellen.	**SBERT:** 0.83 **LLM as Judge:** *(n=1)* ▪ Clarity: 4 ▪ Completeness: 2 ▪ Conciseness: 2 ▪ PC: 5 ▪ Neutrality: 5 ▪ Correctness: 3
3. Alt text **Short description (metadata):** Waagerechtes Balkendiagramm. Titel: Mehrwertsteuer müsste mit der Mitte-Initiative auf 9,6 Prozent erhöht werden. Untertitel: Normalsatz der Mehrwertsteuer (MWSt) in %. Waagrechte Achse: (Ausschnitt) 0 bis 10 Prozent. Senkrechte Achse: 1995, 1999, 2001, 2018, 2024, 2027, 2030. **Short description (overview):** Der Normalsatz der Mehrwertsteuer steigt kontinuierlich von 6,5 Prozent im Jahr 1995 auf prognostizierte 9,6 Prozent im Jahr 2030. Die grössten Sprünge sind um 1999 und von 2027 bis 2030 zu verzeichnen. **Long description:** Der Normalsatz der Mehrwertsteuer beginnt 1995 bei 6,5 Prozent. Er steigt auf 7,5 Prozent 1999, 7,6 Prozent 2001, 7,7 Prozent 2018 und 8,1 Prozent 2024. Die Prognose zeigt eine weitere Steigerung auf 8,8 Prozent bis 2027 und schliesslich 9,6 Prozent im Jahr 2030.	**SBERT:** 0.83 **LLM as Judge:** *(n=1)* ▪ Clarity: 5 ▪ Completeness: 4 ▪ Conciseness: 2 ▪ PC: 5 ▪ Neutrality: 5 ▪ Correctness: 4

4. Alt text **Short description (metadata):** Waagerechtes Balkendiagramm. Titel: Mehrwertsteuer müsste mit der Mitte-Initiative auf 9,6 Prozent erhöht werden. Untertitel: Normalsatz der Mehrwertsteuer (MWSt) in %. Waagrechte Achse: (Ausschnitt) 0 bis 10 Prozent. Senkrechte Achse: 1995, 1999, 2001, 2018, 2024, 2027, 2030. **Short description (overview):** Der Normalsatz der Mehrwertsteuer in der Schweiz steigt kontinuierlich von 6,5 Prozent im Jahr 1995 auf prognostizierte 9,6 Prozent im Jahr 2030 an. **Long description:** Der Normalsatz der MWSt steigt von 6,5 Prozent im Jahr 1995 auf 7,5 Prozent im Jahr 1999 und weiter auf 7,7 Prozent im Jahr 2018. Bis 2024 steigt er auf 8,1 Prozent, bis 2027 (Prognose) auf 8,8 Prozent, und erreicht 2030 (Prognose) 9,6 Prozent.	**SBERT:** 0.83 **LLM as Judge:** *(n=1)* ▪ Clarity: 5 ▪ Completeness: 3 ▪ Conciseness: 2 ▪ PC: 4 ▪ Neutrality: 5 ▪ Correctness: 4
5. Alt text **Short description (metadata):** Waagerechtes Balkendiagramm. Titel: Mehrwertsteuer müsste mit der Mitte-Initiative auf 9,6 Prozent erhöht werden. Untertitel: Normalsatz der Mehrwertsteuer (MWSt) in %. Waagrechte Achse: Normalsatz der Mehrwertsteuer in %. Senkrechte Achse: Zeitraum 1995, 1999, 2001, 2018, 2024, 2027, 2030. **Short description (overview):** Der Normalsatz der Mehrwertsteuer steigt kontinuierlich von 6,5 % im Jahr 1995 auf prognostizierte 9,6 % im Jahr 2030, wobei die größten Anstiege 1999, 2027 und 2030 verzeichnet werden. **Long description:** Der Normalsatz der Mehrwertsteuer beginnt 1995 bei 6,5 %, steigt bis 1999 auf 7,5 % und beträgt 2018 7,7 %. 2024 erreicht er 8,1 % und steigt 2027 auf 8,8 %. Im Jahr 2030 wird prognostiziert die MWSt durch die Mitte-Initiative auf 9,6 % steigen.	**SBERT:** 0.83 **LLM as Judge:** *(n=1)* ▪ Clarity: 4 ▪ Completeness: 2 ▪ Conciseness: 2 ▪ PC: 5 ▪ Neutrality: 5 ▪ Correctness: 4
6. Alt text **Short description (metadata):** Waagerechtes Balkendiagramm. Titel: Mehrwertsteuer müsste mit der Mitte-Initiative auf 9,6 Prozent erhöht werden. Untertitel: Normalsatz der Mehrwertsteuer (MWSt) in %. Waagrechte Achse: (Ausschnitt) 0 bis 10 Prozent. Senkrechte Achse: 1995, 1999, 2001, 2018, 2024, 2027, 2030. **Short description (overview):** Der Normalsatz der Mehrwertsteuer in der Schweiz steigt seit 1995 kontinuierlich an und soll bis 2030 auf 9,6 Prozent ansteigen, hauptsächlich bedingt durch Finanzierungsbedarfe für die Altersvorsorge und andere Initiativen. **Long description:** Der Normalsatz steigt von 6,5 Prozent im Jahr 1995 auf 7,7 Prozent im Jahr 2018. Bis 2024 steigt er auf 8,1 Prozent und erreicht 2027 prognostizierte 8,8 Prozent. Die Prognose für 2030 liegt bei 9,6 Prozent.	**SBERT:** 0.82 **LLM as Judge:** *(n=1)* ▪ Clarity: 4 ▪ Completeness: 2 ▪ Conciseness: 2 ▪ PC: 5 ▪ Neutrality: 5 ▪ Correctness: 3

7. Alt text **Short description (metadata):** Waagerechtes Balkendiagramm. Titel: Mehrwertsteuer müsste mit der Mitte-Initiative auf 9,6 Prozent erhöht werden. Untertitel: Normalsatz der Mehrwertsteuer (MWSt) in %. Waagrechte Achse: (Ausschnitt) 0 bis 10 Prozent. Senkrechte Achse: 1995, 1999, 2001, 2018, 2024, 2027, 2030. **Short description (overview):** Der Normalsatz der Mehrwertsteuer stieg von 1995 bis 2030 kontinuierlich an. Die grösste projektierte Steigerung auf 9,6 Prozent ist auf die Finanzierung der Mitte-Initiative zurückzuführen. **Long description:** Die Mehrwertsteuer stieg von 6,5 Prozent im Jahr 1995 auf 7,7 Prozent im Jahr 2018. Bis 2024 ist ein Anstieg auf 8,1 Prozent und bis 2027 auf 8,8 Prozent prognostiziert. Der Höchstwert liegt 2030 bei 9,6 Prozent.	**SBERT:** 0.82 **LLM as Judge:** *(n=1)* ▪ Clarity: 4 ▪ Completeness: 2 ▪ Conciseness: 1 ▪ PC: 5 ▪ Neutrality: 5 ▪ Correctness: 2
8. Alt text **Short description (metadata):** Waagerechtes Balkendiagramm. Titel: Mehrwertsteuer müsste mit der Mitte-Initiative auf 9,6 Prozent erhöht werden. Untertitel: Normalsatz der Mehrwertsteuer (MWSt) in %. Waagerechte Achse: (Ausschnitt) 0 bis 10 Prozent. Senkrechte Achse: 1995, 1999, 2001, 2018, 2024, 2027, 2030. **Short description (overview):** Der Normalsatz der Mehrwertsteuer steigt kontinuierlich von 6,5 Prozent im Jahr 1995 auf prognostizierte 9,6 Prozent im Jahr 2030, wobei die größten Sprünge bei der AHV und der Mitte-Initiative liegen. **Long description:** Der Normalsatz der MWSt beginnt 1995 bei 6,5 Prozent. Durch Erhöhungen für die AHV und die Bahn steigt er bis 2018 auf 7,7 Prozent. Eine erneute Erhöhung für die AHV führt bis 2024 zu 8,1 Prozent. Mit der MWSt für die 13. AHV-Rente steigt der Satz bis 2027 (Prognose) auf 8,8 Prozent. Bei Finanzierung der Mitte-Initiative wird für 2030 (Prognose) eine Erhöhung auf 9,6 Prozent erwartet.	**SBERT:** 0.8 **LLM as Judge:** *(n=1)* ▪ Clarity: 4 ▪ Completeness: 3 ▪ Conciseness: 1 ▪ PC: 5 ▪ Neutrality: 5 ▪ Correctness: 3
9. Alt text **Short description (metadata):** Waagerechtes Balkendiagramm. Titel: Mehrwertsteuer müsste mit der Mitte-Initiative auf 9,6 Prozent erhöht werden. Untertitel: Normalsatz der Mehrwertsteuer (MWSt) in %. Waagrechte Achse: 0 bis 10 Prozent. Senkrechte Achse: Zeitraum 1995 bis 2030 in unregelmässigen Abständen. **Short description (overview):** Der Normalsatz der Mehrwertsteuer ist von 1995 bis 2030 kontinuierlich gestiegen; eine weitere Steigerung bis 9,6 Prozent ist zur Finanzierung der Mitte-Initiative notwendig. **Long description:** Die Mehrwertsteuer beginnt 1995 bei 6,5 Prozent und steigt bis 2024 auf 8,1 Prozent. Für 2027 wird ein Anstieg auf 8,8 Prozent prognostiziert, während 2030 ein Wert von 9,6 Prozent erwartet wird.	**SBERT:** 0.79 **LLM as Judge:** *(n=1)* ▪ Clarity: 5 ▪ Completeness: 2 ▪ Conciseness: 1 ▪ PC: 5 ▪ Neutrality: 3 ▪ Correctness: 5

10. Alt text	SBERT: 0.78
Short description (metadata): Waagerechtes Balkendiagramm. Titel: Mehrwertsteuer müsste mit der Mitte-Initiative auf 9,6 Prozent erhöht werden. Untertitel: Normalsatz der Mehrwertsteuer (MWSt) in %. Waagrechte Achse: Normalsatz [0] bis [10] [%]. Senkrechte Achse: 1995, 1999, 2001, 2018, 2024, 2027 (Prognose), 2030 (Prognose). **Short description (overview):** Der Normalsatz der Mehrwertsteuer steigt stetig von 6,5 % im Jahr 1995 auf prognostizierte 9,6 % im Jahr 2030, insbesondere durch Massnahmen zur Finanzierung der AHV. **Long description:** Der Normalsatz beginnt 1995 bei 6,5 %. Bis 2001 steigt er langsam auf 7,6 %, dann bis 2018 geringfügig auf 7,7 %. Ein stärkerer Anstieg erfolgt zwischen 2018 und 2024 auf 8,1 % und bis 2027 auf 8,8 %. Für 2030 wird eine weitere Steigerung auf 9,6 % prognostiziert, falls die Mitte-Initiative über die MWSt finanziert wird.	**LLM as Judge:** *(n=1)* ▪ Clarity: 5 ▪ Completeness: 4 ▪ Conciseness: 1 ▪ PC: 5 ▪ Neutrality: 5 ▪ Correctness: 3

014e6bf3927ddaf505c8053e37c8b688

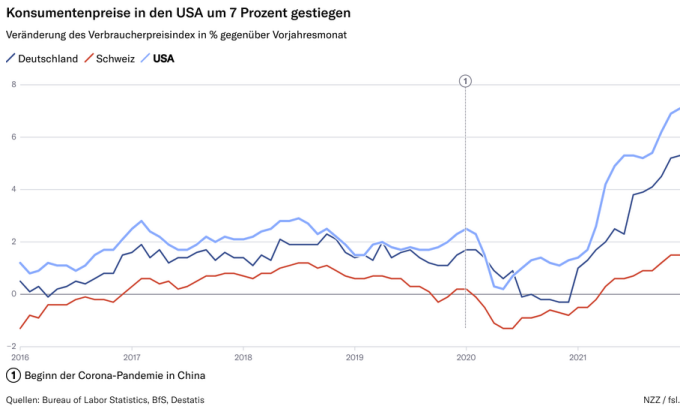

Golden standard

Short description (metadata): Liniendiagramm. Titel: Konsumentenpreise in den USA um 7 Prozent gestiegen. Untertitel: Veränderung des Verbraucherpreisindex in % gegenüber Vorjahresmonat. Waagrechte Achse: Zeitraum 2016 bis 2021. Senkrechte Achse: Minus 2 bis 8 %. Daten: Monatliche Werte. Drei Linien: Deutschland (dunkelblau), Schweiz (rot), USA (hellblau). Senkrechte Linie als Markierung: Beginn der Corona-Pandemie in China.

Short description (overview): Die Konsumentenpreise steigen zwischen 2016 und 2018 leicht an und sinken danach wieder bis 2021. Ab 2021 steigen die Konsumpreise stark an.

Long description: Von 2016 bis Mitte 2018 steigen die Konsumentenpreise: Deutschland von 0.5 % auf rund 2 %, Schweiz von −1.5 % auf etwa 1 %, USA von 1 % auf knapp 3 %. Mitte 2018 bis 2020 gehen die Preise in allen drei Ländern leicht zurück. Nach dem Beginn der Corona-Pandemie fallen sie zunächst, am stärksten in den USA. Danach steigen sie wieder an: USA und Deutschland auf 7 und 5 % und in der Schweiz auf 1.5 %.

1. Alt text **Short description (metadata):** Liniendiagramm. Titel: Konsumentenpreise in den USA um 7 Prozent gestiegen. Untertitel: Veränderung des Verbraucherpreisindex in % gegenüber Vorjahresmonat. Waagerechte Achse: Zeitraum 2016 bis 2021 jährlich. Senkrechte Achse: Ausschnitt minus zwei bis acht Prozent. Daten: Monatliche Werte. Drei Linien: Deutschland (dunkelblau), Schweiz (rot), USA (hellblau). **Short description (overview):** Die Verbraucherpreise in allen drei Ländern weisen von 2016 bis Anfang 2020 einen moderaten Anstieg auf. Ab dem Beginn der Corona-Pandemie im Jahr 2020 fallen die Preise zunächst, steigen dann aber gegen Ende des Jahres 2020 in den USA und Deutschland stark an. Die Schweiz verzeichnet durchgehend die geringste Veränderung. **Long description:** Von 2016 bis Anfang 2020 liegen die USA stets am höchsten, gefolgt von Deutschland und der Schweiz, die teilweise negative Raten aufweist. In der ersten Hälfte 2020 sinken die Raten in allen Ländern. Ab Mitte 2020 dreht der Trend: Die Raten in den USA und Deutschland steigen stark, die USA am stärksten. Ende 2021 erreichen die USA gut sieben Prozent, Deutschland über fünf Prozent und die Schweiz knapp zwei Prozent.	**SBERT:** 0.82 **LLM as Judge:** *(n=1)* ▪ Clarity: 5 ▪ Completeness: 3 ▪ Conciseness: 2 ▪ PC: 5 ▪ Neutrality: 3 ▪ Correctness: 2
2. Alt text **Short description (metadata):** Liniendiagramm. Titel: Konsumentenpreise in den USA um 7 Prozent gestiegen. Untertitel: Veränderung des Verbraucherpreisindex in % gegenüber Vorjahresmonat. Waagerechte Achse: Zeitraum 2016 bis 2021. Senkrechte Achse: Ausschnitt minus zwei bis acht Prozent. Daten: Monatliche Werte. Drei Linien: Deutschland (dunkelblau), Schweiz (rot), USA (hellblau). (Markierungen: Vertikale gestrichelte Linie bei Anfang 2020 markiert den Beginn der Corona-Pandemie in China). **Short description (overview):** Von 2016 bis Anfang 2020 verläuft die Inflationsrate in den USA am höchsten, gefolgt von Deutschland und der Schweiz mit den niedrigsten Werten. Nach dem Einbruch Anfang 2020 steigen die Raten aller drei Länder, wobei die USA und Deutschland gegen Ende 2021 am stärksten zulegen, während die Schweiz deutlich moderater steigt. **Long description:** Vor der Pandemie liegt die US-Inflationsrate zwischen etwa ein und drei Prozent. Deutschland bewegt sich zwischen null und zwei Prozent, die Schweiz zwischen minus eins und plus eins Prozent. Nach dem pandemiebedingten Einbruch und Tiefpunkt im Jahr 2020, der in der Schweiz am stärksten ausgeprägt ist (bis zu minus eins Komma drei Prozent), steigen alle drei Raten an. Ende 2021 erreicht die US-Rate den höchsten Wert von etwa sieben Prozent, gefolgt von Deutschland mit über fünf Prozent und der Schweiz mit anderthalb Prozent.	**SBERT:** 0.81 **LLM as Judge:** *(n=1)* ▪ Clarity: 5 ▪ Completeness: 5 ▪ Conciseness: 1 ▪ PC: 5 ▪ Neutrality: 4 ▪ Correctness: 5

3. Alt text **Short description (metadata):** Liniendiagramm. Titel: Konsumentenpreise in den USA um 7 Prozent gestiegen. Untertitel: Veränderung des Verbraucherpreisindex in % gegenüber Vorjahresmonat. Waagerechte Achse: Zeitraum 2016 bis 2021. Senkrechte Achse: Ausschnitt minus zwei bis acht Prozent. Daten: Monatliche Werte. Drei Linien: Deutschland (dunkelblau), Schweiz (rot), USA (hellblau). Markierungen: Vertikale Linie bei März 2020 (Beginn der Corona-Pandemie in China). **Short description (overview):** Über den gesamten Zeitraum weist die USA die höchste Veränderung des Verbraucherpreisindex auf, gefolgt von Deutschland und der Schweiz. Alle drei Länder zeigen ab der Mitte des Jahres 2020 einen starken Anstieg der Inflation, wobei die USA jedoch deutlich stärker steigt als Deutschland und die Schweiz. **Long description:** Bis Anfang 2020 bewegen sich die Werte für Deutschland und die USA meist zwischen einem und drei Prozent, während die Schweiz im unteren Bereich, oft unter null, verbleibt. Nach einem Einbruch aller Werte um März 2020, steigen die Raten für Deutschland und USA wieder. Ab Mitte 2020 steigen alle Linien stark an. Ende 2021 liegt die USA bei etwa sieben Prozent, Deutschland bei etwa fünf Prozent und die Schweiz bei eineinhalb Prozent.	**SBERT:** 0.79 **LLM as Judge:** *(n=1)* ▪ Clarity: 4 ▪ Completeness: 4 ▪ Conciseness: 1 ▪ PC: 5 ▪ Neutrality: 3 ▪ Correctness: 3
4. Alt text **Short description (metadata):** Liniendiagramm. Titel: Konsumentenpreise in den USA um 7 Prozent gestiegen. Untertitel: Veränderung des Verbraucherpreisindex in % gegenüber Vorjahresmonat. Waagerechte Achse: Zeitraum 2016 bis 2021 jährlich. Senkrechte Achse: Ausschnitt minus zwei bis acht Prozent. Daten: Monatliche Werte. Drei Linien: Deutschland (dunkelblau), Schweiz (rot), USA (hellblau). **Short description (overview):** Die Verbraucherpreisindizes aller drei Länder zeigen eine anfängliche Stabilisierung gefolgt von einem deutlichen Anstieg, insbesondere ab 2020. Die USA weisen durchgehend das höchste Niveau auf, gefolgt von Deutschland und der Schweiz, die die geringsten Veränderungsraten zeigt. **Long description:** Von 2016 bis Anfang 2020 stagnierten die Raten für Deutschland und die USA zwischen einem und drei Prozent, während die Schweiz zwischen minus einem und plus einem Prozent schwankte. Ab März 2020 fallen die Raten kurzfristig ab. Danach steigen sie bis Ende 2021 stark an: Die Rate für Deutschland steigt auf 5,3 Prozent, die der Schweiz auf 1,5 Prozent und die der USA auf 7,1 Prozent.	**SBERT:** 0.76 **LLM as Judge:** *(n=1)* ▪ Clarity: 4 ▪ Completeness: 4 ▪ Conciseness: 2 ▪ PC: 5 ▪ Neutrality: 3 ▪ Correctness: 3

5. Alt text **Short description (metadata):** Liniendiagramm. Titel: Konsumentenpreise in den USA um 7 Prozent gestiegen. Untertitel: Veränderung des Verbraucherpreisindex in % gegenüber Vorjahresmonat. Waagerechte Achse: Zeitraum 2016 bis 2021. Senkrechte Achse: Ausschnitt minus zwei bis acht Prozent. Daten: Monatliche Werte. Drei Linien: Deutschland (dunkelblau), Schweiz (rot), USA (hellblau). **Short description (overview):** Im gesamten Zeitraum weisen die USA die höchsten Konsumentenpreisanstiege auf, während die Schweiz die niedrigsten Raten zeigt und die USA in den Jahren 2021 signifikant stärker steigen als die anderen Länder. Die Entwicklungen in Deutschland liegen überwiegend zwischen denen der USA und der Schweiz. **Long description:** Von 2016 bis 2020 befinden sich die Verbraucherpreisanstiege in den USA auf dem höchsten Niveau, gefolgt von Deutschland und der Schweiz. Ab 2020 fallen die Raten in allen Ländern kurzzeitig. Von 2020 bis zum Ende 2021 steigen die Konsumentenpreise in allen Ländern erneut deutlich, wobei die USA eine massive Zunahme von rund einem Prozent auf über sieben Prozent zeigen. Deutschland steigt von etwa minus 0.3 Prozent auf über fünf Prozent, und die Schweiz von minus 0.8 Prozent auf 1.5 Prozent.	**SBERT:** 0.76 **LLM as Judge:** *(n=1)* ▪ Clarity: 4 ▪ Completeness: 4 ▪ Conciseness: 2 ▪ PC: 5 ▪ Neutrality: 3 ▪ Correctness: 4
6. Alt text **Short description (metadata):** Liniendiagramm. Titel: Konsumentenpreise in den USA um 7 Prozent gestiegen. Untertitel: Veränderung des Verbraucherpreisindex in % gegenüber Vorjahresmonat. Waagerechte Achse: Zeitraum 2016 bis 2021 jährlich. Senkrechte Achse: Ausschnitt minus zwei bis acht Prozent. Daten: Monatliche Werte. Drei Linien: Deutschland (dunkelblau), Schweiz (rot), USA (hellblau). **Short description (overview):** Die Verbraucherpreisindizes aller drei Länder zeigen im Zeitraum 2016 bis 2019 eine moderate Inflation, wobei die USA durchgehend die höchsten Werte aufweisen. Ab Mitte 2020 steigen die USA-Werte signifikant stärker an als Deutschland und die Schweiz. **Long description:** Von 2016 bis Anfang 2020 rangiert die Schweiz am niedrigsten und verzeichnet einige Phasen negativer Veränderung (Deflation). Deutschland liegt im Mittelfeld, und die USA zeigen die höchsten Inflationsraten. Um 2020 fallen die Werte in allen Ländern kurzzeitig. Ab Mitte 2020 steigen die USA-Werte stark, von unter einem Prozent auf über sieben Prozent Ende 2021. Deutschland und die Schweiz steigen ebenfalls, aber moderater, wobei Deutschland bei etwa fünf Prozent und die Schweiz bei eineinhalb Prozent endet.	**SBERT:** 0.75 **LLM as Judge:** *(n=1)* ▪ Clarity: 5 ▪ Completeness: 4 ▪ Conciseness: 1 ▪ PC: 5 ▪ Neutrality: 3 ▪ Correctness: 5

7. Alt text **Short description (metadata):** Liniendiagramm. Titel: Konsumentenpreise in den USA um 7 Prozent gestiegen. Untertitel: Veränderung des Verbraucherpreisindex in % gegenüber Vorjahresmonat. Waagerechte Achse: Zeitraum 2016 bis 2021 jährlich. Senkrechte Achse: Ausschnitt minus zwei bis acht Prozent. Daten: Monatliche Werte. Drei Linien: Deutschland (dunkelblau), Schweiz (rot), USA (hellblau). **Short description (overview):** Die Verbraucherpreise in den USA liegen über den gesamten Zeitraum auf dem höchsten Niveau, während die Schweiz die niedrigsten Werte aufweist und über weite Strecken sogar negative Raten verzeichnet. Die Inflationsraten aller Länder steigen ab 2020 stark an, besonders ausgeprägt in den USA und Deutschland. **Long description:** Von 2016 bis Anfang 2020 bewegen sich die Raten in den USA zwischen circa eins und drei Prozent, in Deutschland zwischen null und zwei Prozent und in der Schweiz zwischen minus eins und plus eins Prozent. Nach einem pandemiebedingten Rückgang im Frühjahr 2020 steigen die Raten bis Ende 2021 stark: Die USA erreicht sieben Prozent, Deutschland circa fünf Prozent und die Schweiz knapp zwei Prozent.	**SBERT:** 0.74 **LLM as Judge:** *(n=1)* ▪ Clarity: 5 ▪ Completeness: 2 ▪ Conciseness: 2 ▪ PC: 5 ▪ Neutrality: 5 ▪ Correctness: 3
8. Alt text **Short description (metadata):** Liniendiagramm. Titel: Konsumentenpreise in den USA um 7 Prozent gestiegen. Untertitel: Veränderung des Verbraucherpreisindex in % gegenüber Vorjahresmonat. Waagerechte Achse: Zeitraum 2016 bis 2021. Senkrechte Achse: Ausschnitt minus zwei bis acht Prozent. Daten: Monatliche Werte. Drei Linien: Deutschland (dunkelblau), Schweiz (rot), USA (hellblau). Markierung: Beginn der Corona-Pandemie in China. **Short description (overview):** Während des gesamten Zeitraums weist die USA die höchsten Verbraucherpreisveränderungen auf, gefolgt von Deutschland und konstant niedrig von der Schweiz. Alle drei Länder zeigen ab 2020 einen deutlichen Anstieg, wobei die USA am stärksten zulegt. **Long description:** Vor dem Jahr 2020 liegen die Veränderungsraten in allen Ländern zwischen minus zwei und drei Prozent. Die USA beginnen 2020 bei zweieinhalb Prozent und steigen bis Ende 2021 auf über sieben Prozent. Deutschland beginnt 2020 bei rund 1,7 Prozent, sinkt kurzzeitig unter Null und steigt bis Ende 2021 auf 5,3 Prozent. Die Schweiz beginnt 2020 bei 0,2 Prozent, sinkt auf minus 1,3 Prozent und steigt bis Ende 2021 auf 1,5 Prozent.	**SBERT:** 0.73 **LLM as Judge:** *(n=1)* ▪ Clarity: 5 ▪ Completeness: 5 ▪ Conciseness: 1 ▪ PC: 5 ▪ Neutrality: 5 ▪ Correctness: 5

9. Alt text **Short description (metadata):** Liniendiagramm. Titel: Konsumentenpreise in den USA um 7 Prozent gestiegen. Untertitel: Veränderung des Verbraucherpreisindex in % gegenüber Vorjahresmonat. Waagerechte Achse: Zeitraum 2016 bis 2021. Senkrechte Achse: Ausschnitt minus zwei bis acht Prozent. Daten: Monatliche Werte. Drei Linien: Deutschland (dunkelblau), Schweiz (rot), USA (hellblau). (Markierung: Beginn der Corona-Pandemie in China). **Short description (overview):** Über den gesamten Zeitraum liegt die Inflationsrate der Schweiz deutlich unter der von Deutschland, während die USA die höchste Inflationsrate aufweisen. Deutschland und die USA zeigen ähnliche Trendwenden vor und nach der globalen Pandemie, wobei die Entwicklung in den USA deutlich stärker ausgeprägt ist. **Long description:** Alle drei Länder weisen stabile, positive Raten vor der Pandemie (markiert bei 2020) auf, wobei die Schweiz um den Nullpunkt und teilweise in den negativen Bereich tendiert. Nach der Pandemie steigen die Raten in den USA und Deutschland stark an. Die USA übersteigen die sechs Prozent Marke, Deutschland die vier Prozent Marke. Die Schweiz verzeichnet einen moderaten Anstieg von etwa minus eins auf etwa plus eins Prozent am Ende des Zeitraums.	**SBERT:** 0.72 **LLM as Judge:** *(n=1)* ▪ Clarity: 4 ▪ Completeness: 4 ▪ Conciseness: 2 ▪ PC: 4 ▪ Neutrality: 5 ▪ Correctness: 3
10. Alt text **Short description (metadata):** Liniendiagramm. Titel: Konsumentenpreise in den USA um 7 Prozent gestiegen. Untertitel: Veränderung des Verbraucherpreisindex in % gegenüber Vorjahresmonat. Waagerechte Achse: Zeitraum 2016 bis 2021 jährlich. Senkrechte Achse: Ausschnitt minus zwei bis acht Prozent. Daten: Monatliche Werte. Drei Linien: Deutschland (dunkelblau), Schweiz (rot), USA (hellblau). **Short description (overview):** Über den gesamten Zeitraum liegt die Inflation in den USA am höchsten, gefolgt von Deutschland. Die Schweiz weist die geringste Inflationsrate auf, die zudem bis 2020 oft negativ ist. Ab 2020 steigen die Inflationsraten in allen drei Ländern deutlich, wobei die USA den stärksten Anstieg verzeichnen und Ende 2021 die höchste Rate aufweisen. **Long description:** Von 2016 bis Anfang 2021 bewegt sich die Inflation in den USA zwischen circa einem und drei Prozent, während Deutschland zwischen null und zwei Prozent liegt. Die Schweiz bleibt in dieser Phase meist unter null Prozent. Ab Anfang 2021 steigen die Raten drastisch: USA von etwa einem auf sieben Prozent, Deutschland von einem auf über fünf Prozent und die Schweiz von unter null auf etwa anderthalb Prozent am Ende des Zeitraums.	**SBERT:** 0.68 **LLM as Judge:** *(n=1)* ▪ Clarity: 4 ▪ Completeness: 4 ▪ Conciseness: 2 ▪ PC: 5 ▪ Neutrality: 3 ▪ Correctness: 2

0154a0854ad542755c62796906582f56

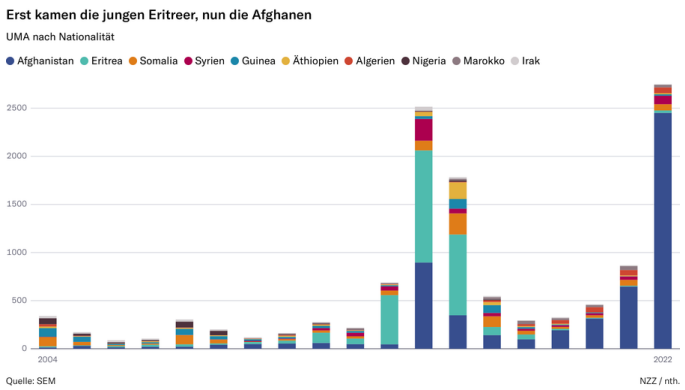

Golden standard

Short description (metadata): Senkrechtes Balkendiagramm. Titel: Erst kamen die jungen Eritreer, nun die Afghanen. Untertitel: UMA nach Nationalität. Waagrechte Achse: 2004 bis 2022. Senkrechte Achse: 0 bis 2'500 UMA. Pro Jahr einen Balken unterteilt in zehn Anteile: Afghanistan, Eritrea, Somalia, Syrien, Guinea, Äthiopien, Algerien, Nigeria, Marokko und Irak.

Short description (overview): Pro Jahr sind es insgesamt zwischen 100 und knapp 900 UMA, mit zwei Spitzen von jeweils über 1800 (2015, 2016 und 2022). Eritrea und Afghanistan machen zum Ende des Beobachtungszeitraums einzeln oder zusammen den grössten Anteil aus.

Long description: Von 2004 bis 2013 liegt die Zahl der UMA zwischen 100 und 300, gleichmässig verteilt auf mehrere Nationalitäten. In den Jahren 2015 und 2016 kommt es zu einem deutlichen Anstieg auf über 2'500 UMA beziehungsweise 1'700. In dieser Phase stammte die Mehrheit aus Eritrea mit Anteilen zwischen 50 und 70 Prozent. Ab 2017 sinken die Zahlen auf 300 bis 500. 2021 und 2022 steigen sie erneut auf 900 und über 2'700. Während der Anteil aus Eritrea ab 2017 sinkt, steigt der Anteil der Afghanen ab 2015 stetig an und beträgt 2022 über 90 Prozent.

1. Alt text

Short description (metadata): Senkrecht gestapeltes Balkendiagramm. Titel: Erst kamen die jungen Eritreer, nun die Afghanen. Untertitel: UMA nach Nationalität. Waagrechte Achse: Zeitreihe: 2004 bis 2022. Senkrechte Achse: Ausschnitt 0 bis 2500. Segmente pro Balken: Afghanistan, Eritrea, Somalia, Syrien, Guinea, Äthiopien, Algerien, Nigeria, Marokko, Irak.

Short description (overview): Die Gesamtzahl der UMA (Unbegleitete Minderjährige Asylsuchende) steigt von 2004 bis 2015 stark an (Peak 2015 bei ca. 2500), fällt danach bis 2020 stark ab und steigt 2022 erneut auf das höchste Niveau von ca. 2700. Die Zusammensetzung der Nationalitäten verschiebt sich mehrfach, wobei Afghanistan 2022 das dominierende Segment mit über 90 Prozent ist.

Long description: Die Gesamtzahl der UMA steigt von etwa 300 im Jahr 2004 auf den ersten Höhepunkt 2015 mit über 2500. Hauptanteil 2015 stellen Eritrea und Afghanistan. Die Zahlen sinken bis 2020 auf unter 500, um 2022 auf über 2700 zu steigen. 2022 dominiert Afghanistan mit über 2400 UMA. Von 2004 bis 2014 schwanken die Zahlen zwischen 100 und 400 mit wechselnden führenden Nationalitäten (Somalia, Afghanistan, Guinea, Eritrea).

SBERT: 0.8

LLM as Judge: *(n=1)*

- Clarity: 5
- Completeness: 4
- Conciseness: 1
- PC: 5
- Neutrality: 5
- Correctness: 3

2. Alt text **Short description (metadata):** Senkrecht gestapeltes Balkendiagramm. Titel: Erst kamen die jungen Eritreer, nun die Afghanen. Untertitel: UMA nach Nationalität. Waagrechte Achse: Zeitreihe: 2004 bis 2022. Senkrechte Achse: 0 bis 2500. Segmente pro Balken: Afghanistan, Eritrea, Somalia, Syrien, Guinea, Äthiopien, Algerien, Nigeria, Marokko, Irak. **Short description (overview):** Die Gesamtzahl der UMA nach Nationalität ist von einem relativ stabilen Niveau zwischen 2004 und 2014 im Jahr 2015 stark angestiegen und sinkt danach, nur um im Jahr 2022 sehr stark zu steigen und den Höchststand zu erreichen. Die Zusammensetzung hat sich stark verändert, dominierten 2015 Eritrea und Afghanistan, sind es 2022 fast ausschliesslich Afghanen. **Long description:** Die Gesamtzahl schwankt von 2004 bis 2014 zwischen etwa 200 und 400. Im Jahr 2015 steigt sie stark auf etwa 2600. Danach sinkt sie wieder auf rund 800 im Jahr 2017 und liegt bis 2020 zwischen etwa 150 und 450. Ab 2021 steigt die Zahl erneut, um 2022 den Höchststand von knapp 2800 zu erreichen. Bis 2014 sind die Beiträge von Eritrea, Somalia, Guinea und Irak stark vertreten. 2015 dominieren Eritrea mit 1165 und Afghanistan mit 896. Ab 2021 dominiert Afghanistan die Zusammensetzung mit einem Anteil von über 80 Prozent.	**SBERT:** 0.78 **LLM as Judge:** *(n=1)* ▪ Clarity: 4 ▪ Completeness: 4 ▪ Conciseness: 2 ▪ PC: 4 ▪ Neutrality: 4 ▪ Correctness: 2
3. Alt text **Short description (metadata):** Senkrechtes gestapeltes Balkendiagramm. Titel: Erst kamen die jungen Eritreer, nun die Afghanen. Untertitel: UMA nach Nationalität. Waagrechte Achse: Zeitreihe von 2004 bis 2022 (jährlich). Senkrechte Achse: null bis 2500 UMA. Segmente pro Balken: Afghanistan (dunkelblau), Eritrea (türkis), Somalia (orange), Syrien (dunkelrot), Guinea (hellblau), Äthiopien (gelb), Algerien (rot), Nigeria (dunkel), Marokko (grau), Irak (hellgrau). **Short description (overview):** Die Gesamtzahl der UMA schwankt zwischen 2004 und 2014 im niedrigen Bereich, steigt 2015 stark an und ist 2022 am höchsten. Die Zusammensetzung der UMA nach Nationalität hat sich ab 2015 und erneut ab 2022 deutlich verschoben. **Long description:** Die Gesamtzahl der UMA liegt zwischen 2004 und 2014 unter 500, mit einem Peak um 300 im Jahr 2008. Im Jahr 2015 steigt die Zahl auf rund 2500, angeführt von Afghanistan und Eritrea. Danach folgt ein Rückgang auf unter 500 bis 2020. 2022 steigt die Zahl auf fast 2700, dominiert von Afghanistan mit rund 2450. Vor 2015 waren Somalia und Guinea meist die prominentesten Herkunftsländer. 2015 dominieren Eritrea und Afghanistan, 2022 dominiert Afghanistan stark.	**SBERT:** 0.76 **LLM as Judge:** *(n=1)* ▪ Clarity: 5 ▪ Completeness: 3 ▪ Conciseness: 1 ▪ PC: 3 ▪ Neutrality: 4 ▪ Correctness: 1

4. Alt text **Short description (metadata):** Senkrecht gestapeltes Balkendiagramm. Titel: Erst kamen die jungen Eritreer, nun die Afghanen. Untertitel: UMA nach Nationalität. Waagrechte Achse: Zeitreihe: 2004 bis 2022. Senkrechte Achse: Null bis 2500 UMA. Segmente pro Balken: Afghanistan (Dunkelblau), Eritrea (Türkis), Somalia (Orange), Syrien (Rot), Guinea (Hellblau), Äthiopien (Gelb), Algerien (Dunkelrot), Nigeria (Dunkelgrau), Marokko (Grau), Irak (Hellgrau). **Short description (overview):** Die Gesamtzahl der UMA variiert stark. Nach einem anfänglich tiefen Niveau bis 2013 steigen die Zahlen sprunghaft an und erreichen 2015 einen Höchststand von über 2500, dominiert von Afghanistan und Eritrea. Bis 2020 sinken die Zahlen wieder stark, um im Jahr 2022 erneut auf über 2800 zu steigen, diesmal fast vollständig dominiert von Afghanistan. **Long description:** Die Gesamtzahl der UMA nach Nationalität liegt von 2004 bis 2013 unter 400. Im Jahr 2014 steigen die Zahlen stark auf über 600, dominiert von Eritrea. Im Jahr 2015 erreichen sie mit über 2500 einen Höchststand, wobei Afghanistan (fast 900) und Eritrea (über 1100) die Hauptakteure sind. Anschließend sinken die Zahlen bis 2020 stark auf ungefähr 450. Danach steigen sie wieder, wobei Afghanistan mit 646 (2021) und 2451 (2022) dominiert und die Gesamtzahl 2022 auf über 2800 erreicht.	**SBERT:** 0.75 **LLM as Judge:** *(n=1)* ▪ Clarity: 5 ▪ Completeness: 5 ▪ Conciseness: 1 ▪ PC: 5 ▪ Neutrality: 3 ▪ Correctness: 4
5. Alt text **Short description (metadata):** Senkrechtes gestapeltes Balkendiagramm. Titel: Erst kamen die jungen Eritreer, nun die Afghanen. Untertitel: UMA nach Nationalität. Waagrechte Achse: Zeitreihe von 2004 bis 2022 (jährlich). Senkrechte Achse: null bis 2500. Segmente pro Balken: Afghanistan (dunkelblau), Eritrea (türkis), Somalia (orange), Syrien (rot), Guinea (blau), Äthiopien (gelb), Algerien (dunkelrot), Nigeria (dunkelgrau), Marokko (hellgrau), Irak (weissgrau). **Short description (overview):** Die Gesamtzahl der UMA schwankt zwischen 2004 und 2014 im niedrigen Bereich und steigt 2015 stark an (Peak bei über 2500), sinkt dann zwischen 2017 und 2020 wieder ab (Tiefstwert 2020 bei circa 500) und steigt 2022 stark an auf über 2500 UMA. Die Dominanz verschiebt sich vor 2015 zwischen Nigeria, Guinea und Somalia, ist 2015 und 2016 klar bei Eritrea und ab 2021 klar bei Afghanistan. **Long description:** Die Gesamtzahl der UMA liegt bis 2014 bei unter 400. 2015 steigt sie stark an, dominiert von Eritrea (1165) und Afghanistan (896). 2016 sinkt die Zahl, bleibt aber von Eritrea dominiert. Bis 2020 sinkt die Zahl weiter, erreicht circa 500 UMA. 2021 und 2022 steigen die Zahlen stark an, mit deutlicher Verschiebung nach Afghanistan (2451 in 2022), während Eritrea-Zahlen stark sinken (25 in 2022). Syrien, Irak, Somerville und Algerien tragen in den letzten Jahren konstante, aber kleinere Anteile bei.	**SBERT:** 0.75 **LLM as Judge:** *(n=1)* ▪ Clarity: 4 ▪ Completeness: 3 ▪ Conciseness: 1 ▪ PC: 4 ▪ Neutrality: 5 ▪ Correctness: 2

6. Alt text **Short description (metadata):** Senkrechtes gestapeltes Balkendiagramm. Titel: Erst kamen die jungen Eritreer, nun die Afghanen. Untertitel: UMA nach Nationalität. Waagrechte Achse: Zeitreihe von 2004 bis 2022 (jährlich). Senkrechte Achse: null bis zweitausendfünfhundert. Segmente pro Balken: Afghanistan, Eritrea, Somalia, Syrien, Guinea, Äthiopien, Algerien, Nigeria, Marokko, Irak. **Short description (overview):** Die Gesamtzahl der UMA (Unbegleitete minderjährige Asylsuchende) schwankt stark, mit einem deutlichen Höhepunkt im Jahr 2015 bei über 2500 und einem zweiten Peak im Jahr 2022 mit fast 2700. Die Zusammensetzung der UMA hat sich im Zeitverlauf verändert: Bis 2014 dominierten verschiedene afrikanische Nationalitäten (Guinea als grösste Gruppe von 2004 bis 2013), 2014 bis 2016 lag der Fokus auf Eritrea, und ab 2021 dominiert Afghanistan. **Long description:** Die Gesamtzahl der UMA liegt von 2004 bis 2013 unter 400, steigt 2014 auf rund 650 und erreicht 2015 den ersten Peak bei über 2500, bevor sie bis 2018 auf unter 300 sinkt. Ab 2019 steigt diese Zahl wieder an und erreicht 2022 einen neuen Peak bei etwa 2700. Von 2004 bis 2013 stellt Guinea meist die grösste Gruppe (maximal 90 im Jahr 2004). 2014 dominiert Eritrea mit über 500, 2015 liegt Guinea mit 1'165 knapp vor Afghanistan mit 896. Ab 2021 liegt Afghanistan konstant vorn und steigt von 646 auf 2'451 im Jahr 2022.	**SBERT:** 0.73 **LLM as Judge:** *(n=1)* ▪ Clarity: 5 ▪ Completeness: 2 ▪ Conciseness: 2 ▪ PC: 4 ▪ Neutrality: 3 ▪ Correctness: 2
7. Alt text **Short description (metadata):** Senkrecht gestapeltes Balkendiagramm. Titel: Erst kamen die jungen Eritreer, nun die Afghanen. Untertitel: UMA nach Nationalität. Waagrechte Achse: Zeitreihe: 2004 bis 2022. Senkrechte Achse: 0 bis 2500. Segmente pro Balken: Afghanistan (Dunkelblau), Eritrea (Türkis), Somalia (Orange), Syrien (Rot), Guinea (Hellblau), Äthiopien (Gelb), Algerien (Dunkelrot), Nigeria (Dunkelgrau), Marokko (Grau), Irak (Hellgrau). **Short description (overview):** Die Gesamtzahl an UMA (Unbegleitete Minderjährige Asylsuchende) schwankt stark. Nach einem Tiefststand um 2007 (unter 200) steigt sie stark an, erreicht 2015 ein erstes Maximum (über 2500, dominiert von Eritrea und Afghanistan) und sinkt bis 2020 wieder deutlich ab. Bis 2022 steigt die Zahl massiv auf über 2800, wobei Afghanistan nun das dominierende Herkunftsland ist. **Long description:** Die Gesamtzahl der UMA steigt von 2004 bis 2015 stark an, von etwa 300 auf über 2500. Dabei dominieren bis 2014 Eritrea und Afghanistan, 2015 sind diese etwa gleich stark vertreten. Nach 2015 sinkt die Zahl bis 2020 auf unter 500, steigt jedoch bis 2022 auf über 2800. 2022 stammt ein Grossteil der UMA aus Afghanistan (über 2450), gefolgt von Syrien (über 80), Somalia (über 60) und Algerien (über 60).	**SBERT:** 0.73 **LLM as Judge:** *(n=1)* ▪ Clarity: 5 ▪ Completeness: 5 ▪ Conciseness: 1 ▪ PC: 5 ▪ Neutrality: 3 ▪ Correctness: 2

8. Alt text **Short description (metadata):** Senkrechtes Balkendiagramm. Titel: Erst kamen die jungen Eritreer, nun die Afghanen. Untertitel: UMA nach Nationalität. Waagrechte Achse: Zeitreihe: 2004 bis 2022. Senkrechte Achse: 0 bis 2500. Segmente pro Balken: Afghanistan (Dunkelblau), Eritrea (Türkis), Somalia (Orange), Syrien (Rot), Guinea (Hellblau), Äthiopien (Gelb), Algerien (Rotorange), Nigeria (Dunkel Violett), Marokko (Grau), Irak (Hellgrau). **Short description (overview):** Die Gesamtzahl der UMA (Unbegleitete Minderjährige Asylsuchende) nach Nationalität zeigt über den Zeitraum 2004 bis 2022 eine stark schwankende Entwicklung und erreicht 2015 und 2022 Höchststände. Anfangs dominiert Somalia, gefolgt von Guinea, aber ab 2014 werden Eritrea (2014–2016) und ab 2021 Afghanistan die vorherrschenden Nationalitäten. **Long description:** Die Gesamtzahl liegt bis 2014 meist unter 500, mit einem ersten Peak von rund 2300 im Jahr 2015, angeführt von Eritrea. Danach sinkt die Zahl bis 2018 auf unter 300, gefolgt von einem starken Anstieg 2022 auf über 2600, wobei Afghanistan dominiert. Somalia und Guinea sind bis 2013 häufig die grössten Segmente, danach lösen Eritrea (2014–2016) und Syrien (2015) sie als Hauptgruppen ab. Ab 2021 dominiert Afghanistan und macht 2022 den Grossteil aus.	**SBERT:** 0.72 **LLM as Judge:** *(n=1)* ▪ Clarity: 5 ▪ Completeness: 5 ▪ Conciseness: 1 ▪ PC: 4 ▪ Neutrality: 3 ▪ Correctness: 2
9. Alt text **Short description (metadata):** Senkrechtes Balkendiagramm. Titel: Erst kamen die jungen Eritreer, nun die Afghanen. Untertitel: UMA nach Nationalität. Waagrechte Achse: Zeitreihe: 2004 bis 2022. Senkrechte Achse: Null bis 2500. Pro Jahr ein Balken unterteilt in zehn Anteile: Afghanistan (dunkelblau), Eritrea (türkis), Somalia (orange), Syrien (dunkelrot), Guinea (hellblau), Äthiopien (gelb), Algerien (rot), Nigeria (dunkelbraun), Marokko (grau), Irak (hellgrau). **Short description (overview):** Die Gesamtzahl der UMA (unbegleitete minderjährige Asylsuchende) schwankt stark, mit einem ersten Höchststand um 2015 und einem zweiten, weitaus grösseren Peak im Jahr 2022. Die Segmentdominanz verschiebt sich deutlich von Eritrea im Jahr 2015 zu Afghanistan im Jahr 2022. **Long description:** Die Gesamtzahl der UMA liegt von 2004 bis 2014 im niedrigen Bereich unter 500. Zwischen 2014 und 2015 steigt der Wert stark an auf über 2500 und sinkt bis 2020 wieder unter 500. Von 2020 bis 2022 steigt die Zahl drastisch an und erreicht 2022 ein Maximum von über 2800. Im Jahr 2015 dominiert Eritrea mit über 1100 UMA, gefolgt von Afghanistan mit knapp 900. Im Jahr 2022 dominiert Afghanistan mit über 2400.	**SBERT:** 0.68 **LLM as Judge:** *(n=1)* ▪ Clarity: 4 ▪ Completeness: 3 ▪ Conciseness: 1 ▪ PC: 5 ▪ Neutrality: 2 ▪ Correctness: 2

10. Alt text	SBERT: 0.62
Short description (metadata): Senkrechtes gestapeltes Balkendiagramm. Titel: Erst kamen die jungen Eritreer, nun die Afghanen. Untertitel: UMA nach Nationalität. Waagrechte Achse: Zeitreihe von 2004 bis 2022 (jährlich). Senkrechte Achse (Ausschnitt): null bis 2500. Segmente pro Balken: Afghanistan (Dunkelblau), Eritrea (Türkis), Somalia (Orange), Syrien (Rot), Guinea (Hellblau), Äthiopien (Gelb), Algerien (Dunkelrot), Nigeria (Dunkelgrau), Marokko (Hellgrau), Irak (Weissgrau). **Short description (overview):** Die Gesamthöhe der UMA (Unbegleitete Minderjährige Asylsuchende) schwankt stark, mit Spitzenjahren in 2015 (rund 2400) und 2022 (rund 2700). Die Segmentdominanz wechselt: Bis 2014 dominieren verschiedene afrikanische Länder (v.a. Somalia, Guinea), 2015 ist die Dominanz geteilt zwischen Eritrea und Afghanistan, und 2022 dominiert Afghanistan stark. **Long description:** Die Gesamtzahl der UMA liegt 2004 bei rund 300 und sinkt bis 2010 auf unter 100. Danach steigt sie kontinuierlich mit einem starken Peak 2015 auf rund 2400, sinkt bis 2018 auf unter 300 und steigt bis 2022 auf den Höchstwert von rund 2700 an. Bis 2014 führen meist Somalia und Guinea das Feld an. Im Jahr 2015 bilden Eritrea (rund 1165) und Afghanistan (rund 896) die grössten Anteile. Von 2016 bis 2021 ist kein Segment klar dominant. Im Jahr 2022 macht Afghanistan mit 2451 UMA den Grossteil aus.	**LLM as Judge:** *(n=1)* ▪ Clarity: 4 ▪ Completeness: 5 ▪ Conciseness: 1 ▪ PC: 2 ▪ Neutrality: 5 ▪ Correctness: 2

016934e7c13b1b546fdea80efd074e02

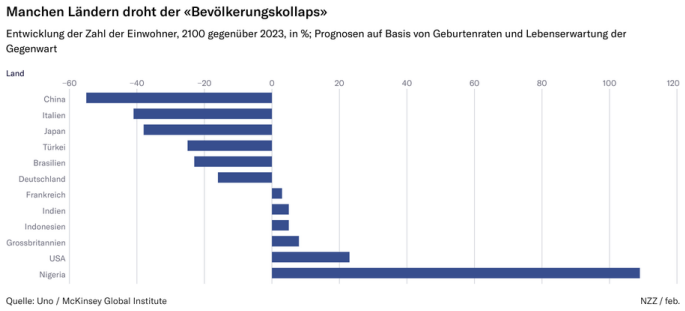

Golden standard

Short description (metadata): Waagrechtes Balkendiagramm. Titel: Manchen Ländern droht der Bevölkerungskollaps. Untertitel: Entwicklung der Zahl der Einwohner, 2100 gegenüber 2023, in %; Prognosen auf Basis von Geburtenraten und Lebenserwartungen der Gegenwart. Waagrechte Achse: Ausschnitt minus 60 bis 120 %. Senkrechte Achse: 12 Länder.

Short description (overview): Sechs Länder zeigen ein negatives, sechs Länder ein positives prognostiziertes Bevölkerungswachstum.

Long description: China: Prognose Minus 55 %. Italien, Japan: Je etwa minus 40 %. Türkei, Brasilien, Deutschland: Je etwa minus 20 %. Frankreich, Indien, Indonesien, Grossbritannien: 3 % bis 8 %. USA: 23 %. Nigeria: 109 %.

1. Alt text **Short description (metadata):** Waagrechtes Balkendiagramm. Titel: Manchen Ländern droht der «Bevölkerungskollaps». Untertitel: Entwicklung der Zahl der Einwohner, 2100 gegenüber 2023, in %; Prognosen auf Basis von Geburtenraten und Lebenserwartung der Gegenwart. Senkrechte Achse: 12 Länder. Waagrechte Achse: Ausschnitt minus 60 bis 120 Prozent. **Short description (overview):** China und Italien verzeichnen zwischen 2023 und 2100 den stärksten prognostizierten Bevölkerungsrückgang. Nigeria erfährt den mit Abstand höchsten Zuwachs. **Long description:** China prognostiziert einen Rückgang der Einwohnerzahl von minus 55 Prozent und Italien von minus 41 Prozent. Dahinter folgen Japan mit minus 38 Prozent, die Türkei mit minus 25 Prozent und Brasilien mit minus 23 Prozent. Bei Deutschland sind es minus 16 Prozent. Frankreich und Indien verzeichnen einen leichten Zuwachs von je 3 und 5 Prozent. Der höchste Zuwachs wird Nigeria mit 109 Prozent prognostiziert, gefolgt von den USA mit 23 Prozent.	**SBERT:** 0.79 **LLM as Judge:** *(n=1)* ▪ Clarity: 5 ▪ Completeness: 3 ▪ Conciseness: 2 ▪ PC: 5 ▪ Neutrality: 5 ▪ Correctness: 5
2. Alt text **Short description (metadata):** Waagrechtes Balkendiagramm. Titel: Manchen Ländern droht der «Bevölkerungskollaps». Untertitel: Entwicklung der Zahl der Einwohner, 2100 gegenüber 2023, in %; Prognosen auf Basis von Geburtenraten und Lebenserwartung der Gegenwart. Waagrechte Achse: (Ausschnitt) minus 60 bis 120 Prozent. Senkrechte Achse: 12 Länder. **Short description (overview):** China und Italien weisen den stärksten prognostizierten Bevölkerungsrückgang bis 2100 auf, während Nigeria einen massiven Zuwachs sehen soll. **Long description:** China soll einen Rückgang um 55 Prozent verzeichnen, gefolgt von Italien mit minus 41 Prozent und Japan mit minus 38 Prozent. Türkei und Brasilien liegen bei minus 25 beziehungsweise minus 23 Prozent. Deutschland sinkt um 16 Prozent. Frankreich, Indien und Indonesien steigen jeweils um 3 bis 5 Prozent. Grossbritannien (8 Prozent) und die USA (23 Prozent) weisen moderaten Zuwachs auf. Nigeria steigt um 109 Prozent.	**SBERT:** 0.75 **LLM as Judge:** *(n=1)* ▪ Clarity: 4 ▪ Completeness: 4 ▪ Conciseness: 1 ▪ PC: 5 ▪ Neutrality: 3 ▪ Correctness: 5
3. Alt text **Short description (metadata):** Waagrechtes Balkendiagramm. Titel: Manchen Ländern droht der «Bevölkerungskollaps». Untertitel: Entwicklung der Zahl der Einwohner, 2100 gegenüber 2023, in %; Prognosen auf Basis von Geburtenraten und Lebenserwartung der Gegenwart. Waagrechte Achse: minus 60 bis 120 Prozent. Senkrechte Achse: 12 Länder. **Short description (overview):** Während für Nigeria ein starker Bevölkerungszuwachs bis 2100 prognostiziert wird, wird in China, Italien und Japan mit einem massiven Bevölkerungsrückgang gerechnet. Die meisten anderen Länder zeigen leichtere Veränderungen. **Long description:** Der größte Bevölkerungszuwachs wird für Nigeria mit 109 Prozent erwartet. Die USA sollen um 23 Prozent wachsen. Die übrigen Länder zeigen bis auf Deutschland, Brasilien, Türkei, Japan, Italien und China einen leichten Anstieg oder leichten Rückgang der Bevölkerung zwischen minus 16 und plus 8 Prozent. China verzeichnet den größten Rückgang von minus 55 Prozent, gefolgt von Italien mit minus 41 und Japan mit minus 38 Prozent.	**SBERT:** 0.75 **LLM as Judge:** *(n=1)* ▪ Clarity: 4 ▪ Completeness: 3 ▪ Conciseness: 2 ▪ PC: 4 ▪ Neutrality: 3 ▪ Correctness: 5

4. Alt text **Short description (metadata):** Waagrechtes Balkendiagramm. Titel: Manchen Ländern droht der «Bevölkerungskollaps». Untertitel: Entwicklung der Zahl der Einwohner, 2100 gegenüber 2023, in %; Prognosen auf Basis von Geburtenraten und Lebenserwartung der Gegenwart. Senkrechte Achse: 12 Länder. Waagrechte Achse: Ausschnitt minus 60 bis 120 Prozent. **Short description (overview):** Eine Mehrheit der aufgeführten Länder wird bis 2100 einen Bevölkerungsrückgang verzeichnen, angeführt von China. Nigeria sticht mit einem extrem hohen Bevölkerungszuwachs heraus. **Long description:** China verzeichnet den grössten Rückgang der Bevölkerung mit minus 55 Prozent, gefolgt von Italien mit minus 41 Prozent und Japan mit minus 38 Prozent. Deutschland liegt bei minus 16 Prozent. Im Gegensatz dazu verzeichnen Frankreich, Indien und Indonesien einen geringen Zuwachs von drei bis fünf Prozent. Nigeria weist mit 109 Prozent den höchsten Bevölkerungszuwachs bis 2100 auf.	**SBERT:** 0.72 **LLM as Judge:** *(n=1)* ▪ Clarity: 4 ▪ Completeness: 3 ▪ Conciseness: 2 ▪ PC: 3 ▪ Neutrality: 3 ▪ Correctness: 4
5. Alt text **Short description (metadata):** Waagrechtes Balkendiagramm. Titel: Manchen Ländern droht der «Bevölkerungskollaps». Untertitel: Entwicklung der Zahl der Einwohner, 2100 gegenüber 2023, in %; Prognosen auf Basis von Geburtenraten und Lebenserwartung der Gegenwart. Waagrechte Achse: minus 60 bis 120 Prozent. Senkrechte Achse: 12 Länder. **Short description (overview):** China erlebt den stärksten prognostizierten Rückgang der Bevölkerung bis 2100 mit minus 55 Prozent, gefolgt von Italien und Japan. Nigeria hingegen verzeichnet den weitaus grössten Zuwachs von 109 Prozent. **Long description:** China verzeichnet einen Rückgang der Einwohnerzahl von minus 55 Prozent. Italien, Japan, Türkei, Brasilien und Deutschland folgen mit Werten zwischen minus 41 und minus 16 Prozent. Frankreich, Indien und Indonesien zeigen geringe Zuwächse von 3 bis 5 Prozent. Grossbritannien (8 Prozent) und die USA (23 Prozent) steigern ihre Bevölkerungszahl, während Nigeria mit 109 Prozent den grössten Zuwachs hat.	**SBERT:** 0.72 **LLM as Judge:** *(n=1)* ▪ Clarity: 5 ▪ Completeness: 5 ▪ Conciseness: 1 ▪ PC: 5 ▪ Neutrality: 5 ▪ Correctness: 5
6. Alt text **Short description (metadata):** Waagrechtes Balkendiagramm. Titel: Manchen Ländern droht der «Bevölkerungskollaps». Untertitel: Entwicklung der Zahl der Einwohner, 2100 gegenüber 2023, in %; Prognosen auf Basis von Geburtenraten und Lebenserwartung der Gegenwart. Waagrechte Achse: (Ausschnitt) minus 60 bis 120 Prozent. Senkrechte Achse: 12 Länder. **Short description (overview):** Eine Mehrheit der aufgeführten Länder (7 von 12) wird bis 2100 einen Bevölkerungsrückgang verzeichnen, wobei China den stärksten Rückgang erlebt. Nur Frankreich, Indien, Indonesien, Grossbritannien, die USA und Nigeria erwarten einen Bevölkerungszuwachs, wobei Nigeria den höchsten Anstieg hat. **Long description:** China verzeichnet mit minus 55 Prozent den stärksten Bevölkerungsrückgang, gefolgt von Italien mit minus 41 Prozent und Japan mit minus 38 Prozent. Deutschland sinkt um minus 16 Prozent. Frankreich und Indien steigen um 3 bzw. 5 Prozent. Nigeria erlebt mit 109 Prozent den stärksten Anstieg.	**SBERT:** 0.72 **LLM as Judge:** *(n=1)* ▪ Clarity: 2 ▪ Completeness: 3 ▪ Conciseness: 2 ▪ PC: 2 ▪ Neutrality: 5 ▪ Correctness: 4

7. Alt text **Short description (metadata):** Waagrechtes Balkendiagramm. Titel: Manchen Ländern droht der «Bevölkerungskollaps». Untertitel: Entwicklung der Zahl der Einwohner, 2100 gegenüber 2023, in %; Prognosen auf Basis von Geburtenraten und Lebenserwartung der Gegenwart. Senkrechte Achse: 12 Länder. Waagrechte Achse: Ausschnitt minus 60 bis 120 Prozent. **Short description (overview):** China und Italien verzeichnen den stärksten Rückgang der Bevölkerungszahl, während Nigeria den höchsten Bevölkerungszuwachs aufweist. Die meisten europäischen und einige asiatische Länder erleben einen Rückgang, während Nigeria und die USA den stärksten Zuwachs erwarten. **Long description:** China hat den grössten Rückgang von minus 55 Prozent, gefolgt von Italien mit minus 41 Prozent und Japan mit minus 38 Prozent. Deutschland erwartet einen Rückgang von minus 16 Prozent, während Frankreich einen Zuwachs von 3 Prozent verzeichnet. Der USA-Wert liegt bei 23 Prozent Zuwachs, und Nigeria ragt mit 109 Prozent Zuwachs deutlich heraus.	**SBERT:** 0.71 **LLM as Judge:** *(n=1)* ▪ Clarity: 4 ▪ Completeness: 3 ▪ Conciseness: 1 ▪ PC: 4 ▪ Neutrality: 4 ▪ Correctness: 5
8. Alt text **Short description (metadata):** Waagrechtes Balkendiagramm. Titel: Manchen Ländern droht der «Bevölkerungskollaps». Untertitel: Entwicklung der Zahl der Einwohner, 2100 gegenüber 2023, in %; Prognosen auf Basis von Geburtenraten und Lebenserwartung der Gegenwart. Waagrechte Achse: (Ausschnitt) minus 60 bis 120 Prozent. Senkrechte Achse: 12 Länder. **Short description (overview):** China erlebt mit einem Rückgang von 55 Prozent den grössten Bevölkerungsverlust bis 2100 unter den gelisteten Ländern, während Nigeria mit einem Zuwachs von 109 Prozent den stärksten Anstieg verzeichnet. Italien, Japan, Türkei, Brasilien und Deutschland werden ebenfalls einen deutlichen Bevölkerungsrückgang erfahren. **Long description:** China weist den grössten Rückgang von minus 55 Prozent auf, gefolgt von Italien mit minus 41 Prozent und Japan mit minus 38 Prozent. Türkei sinkt um minus 25 Prozent, Brasilien um minus 23 Prozent und Deutschland um minus 16 Prozent. Frankreich, Indien und Indonesien zeigen geringe Zuwächse oder Rückgänge zwischen minus 3 und 5 Prozent. Grossbritannien steigt um 8 Prozent, die USA um 23 Prozent und Nigeria um 109 Prozent.	**SBERT:** 0.71 **LLM as Judge:** *(n=1)* ▪ Clarity: 4 ▪ Completeness: 4 ▪ Conciseness: 1 ▪ PC: 5 ▪ Neutrality: 5 ▪ Correctness: 3
9. Alt text **Short description (metadata):** : Waagrechtes Balkendiagramm. Titel: Manchen Ländern droht der «Bevölkerungskollaps». Untertitel: Entwicklung der Zahl der Einwohner, 2100 gegenüber 2023, in %; Prognosen auf Basis von Geburtenraten und Lebenserwartung der Gegenwart. Senkrechte Achse: 12 Länder. Waagrechte Achse: Ausschnitt minus 60 bis 120 Prozent. **Short description (overview):** : China verzeichnet den stärksten Rückgang der Bevölkerungszahl bis 2100 mit minus 55 Prozent, während Nigeria den höchsten Zuwachs mit 109 Prozent aufweist. **Long description:** : Die Bevölkerung sinkt am stärksten in China mit minus 55 Prozent, gefolgt von Italien minus 41 Prozent und Japan minus 38 Prozent. Deutschland sinkt um minus 16 Prozent. Frankreich und Indien verzeichnen einen geringen Bevölkerungszuwachs von drei beziehungsweise fünf Prozent. Die USA weisen einen Zuwachs von 23 Prozent und Nigeria von 109 Prozent auf.	**SBERT:** 0.69 **LLM as Judge:** *(n=1)* ▪ Clarity: 4 ▪ Completeness: 2 ▪ Conciseness: 1 ▪ PC: 4 ▪ Neutrality: 5 ▪ Correctness: 5

10. Alt text	SBERT: 0.64
Short description (metadata): Waagrechtes Balkendiagramm. Titel: Manchen Ländern droht der «Bevölkerungskollaps». Untertitel: Entwicklung der Zahl der Einwohner, 2100 gegenüber 2023, in %; Prognosen auf Basis von Geburtenraten und Lebenserwartung der Gegenwart. Waagrechte Achse: (Ausschnitt) minus 60 bis 120 Prozent. Senkrechte Achse: 12 Länder. **Short description (overview):** Eine deutliche Bevölkerungsabnahme bis zum Jahr 2100 wird für China, Italien und Japan erwartet, während Nigeria einen sehr starken Zuwachs verzeichnen dürfte. **Long description:** Die Bevölkerung sinkt in China um 55 Prozent, in Italien um 41 Prozent und in Japan um 38 Prozent. Deutschland verzeichnet einen Rückgang von 16 Prozent. Frankreich und Indien weisen ein leichtes Wachstum von respektive 3 und 5 Prozent auf. Die USA wächst um 23 Prozent und Nigeria mit 109 Prozent am stärksten.	**LLM as Judge:** *(n=1)* ▪ Clarity: 4 ▪ Completeness: 2 ▪ Conciseness: 1 ▪ PC: 4 ▪ Neutrality: 3 ▪ Correctness: 5

010aa6a0bdfe0194f6ac81b94f4a7cc6

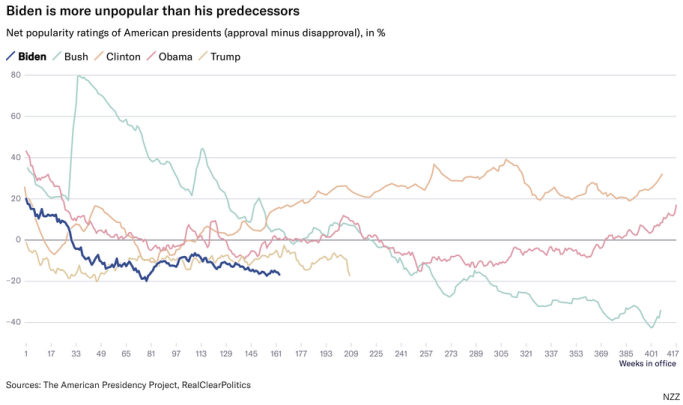

Golden standard

Short description (metadata): Liniendiagramm. Titel: Biden ist unbeliebter als seine Vorgänger. Untertitel: Nettobeliebtheitswerte amerikanischer Präsidenten (Zustimmung minus Ablehnung), in %. Waagrechte Achse: 1 bis 417 Wochen im Amt. Senkrechte Achse: Ausschnitt von minus 40 % bis 80 %. Fünf Linien: Biden, Bush, Clinton, Obama und Trump. Daten: Wöchentliche Werte.

Short description (overview): Die Nettobeliebtheitswerte der Präsidenten beginnen unterschiedlich positiv und sinken mehrheitlich direkt zu Beginn ihrer Amtszeit. Biden und Trump sind beide etwa 200 Wochen im Amt, Bush, Clinton und Obama rund 400 Wochen.

Long description: Bush's Nettobeliebtheitswerte beginnen bei knapp 40 % sinken bis Woche 20 auf 20 % und steigen dann sprunghaft auf den Höchstwert von rund 80 %. Sinken dann aber kontinuierlich und betragen beim Ende seiner Amtszeit rund minus 40 %, dem tiefsten Wert zum Ende einer Amtszeit. Clinton's Werte betragen gut 20 % und steigen nach zwei Tiefs zu Beginn, kontinuierlich mit einigen Schwankungen auf gut 30 %, den höchsten Wert zum Ende einer Amtszeit. Ähnlich verlaufen die Werte von Obama der mit über 40 % den höchsten Anfangswert hat und dann mit einigen Auf- und Ab auf 20 % sinkt. Trump's Wert ist zu Beginn 0, am tiefsten von allen, und sinkt mit einigen Schwankungen auf knapp minus 20 %. Biden's Anfangswert beträgt fast 20 %, ähnlich wie Clinton und seine Werte sinken auf knapp minus 20 %, was dem Niveau von Trump entspricht.

1. Alt text **Short description (metadata):** Liniendiagramm. Titel: Biden is more unpopular than his predecessors. Untertitel: Net popularity ratings of American presidents (approval minus disapproval), in %. Waagerechte Achse: Zeitraum 1 bis 417 Wochen im Amt. Senkrechte Achse: Ausschnitt minus 40 bis 80 Prozent. Daten: Wöchentliche Werte. Fünf Linien: Biden (dunkelblau), Bush (hellgrün), Clinton (orange), Obama (rosa), Trump (gelb). **Short description (overview):** Während Bush und Clinton überwiegend positive Nettobewertungen aufweisen, verbringen Obama, Trump und Biden einen Großteil ihrer Amtszeit im negativen Bereich. Biden hat durchgehend die niedrigsten Bewertungen während der frühen Amtsjahre im Vergleich zu seinen Vorgängern, die im Diagramm gezeigt werden. **Long description:** **Bush** startet am höchsten und steigt nach etwa 30 Wochen auf fast 80 Prozent, fällt dann fast kontinuierlich bis zum Ende der Messung auf unter minus 40 Prozent. **Clinton** beginnt im positiven Bereich, fällt schnell unter Null und steigt danach allmählich und pendelt um die 20 Prozent. **Obama** und **Trump** starten beide um Null, mit **Obama** anfangs höher. Beide fallen in den negativen Bereich, wobei **Obama** größtenteils leicht über **Trump** liegt, bevor beide zum Ende der Messung wieder ansteigen. **Biden** startet positiv, fällt als schnellster unter Null und verläuft durchgehend im negativen Bereich zwischen minus 10 und minus 20 Prozent.	**SBERT:** 0.78 **LLM as Judge:** *(n=1)* ▪ Clarity: 5 ▪ Completeness: 3 ▪ Conciseness: 2 ▪ PC: 4 ▪ Neutrality: 5 ▪ Correctness: 2
2. Alt text **Short description (metadata):** Liniendiagramm. Titel: Biden is more unpopular than his predecessors. Untertitel: Net popularity ratings of American presidents (approval minus disapproval), in %. Waagerechte Achse: Wochen im Amt von 1 bis 417. Senkrechte Achse: Netto-Zustimmung von minus 40 bis 80 Prozent. Daten: Wöchentliche Werte. Fünf Linien: Biden (dunkelblau), Bush (türkis), Clinton (orange), Obama (pink), Trump (gelb). **Short description (overview):** Die Netto-Zustimmung von Bush startet am höchsten, gefolgt von Obama und Biden, während Clinton und Trump im negativen Bereich beginnen. Während Bushs Wert schnell fällt und alle Präsidenten im Zeitverlauf sinkende Trends zeigen, bleibt Bidens Netto-Zustimmung die gesamte dargestellte Zeit im negativen Bereich und ist seit der 80. Woche am geringsten. **Long description:** Biden beginnt bei rund 20 Prozent und sinkt schnell unter null bis zur 30. Woche und bleibt bis zum Ende bei etwa minus 15 Prozent. Bush startet bei etwa 35 Prozent, steigt extrem an auf fast 80 Prozent in der 35. Woche, fällt danach kontinuierlich bis auf rund minus 40 Prozent. Clinton beginnt bei etwa 25 Prozent, sinkt um null herum und steigt dann langsam auf fast 40 Prozent. Obama startet bei über 40 Prozent, sinkt stetig und pendelt zwischen plus 20 und minus 20 Prozent. Trump beginnt bei etwa minus 5 Prozent und pendelt zwischen minus 5 Prozent und minus 20 Prozent. Alle Kurven konvergieren über die Zeit grob um null oder darunter.	**SBERT:** 0.78 **LLM as Judge:** *(n=1)* ▪ Clarity: 3 ▪ Completeness: 2 ▪ Conciseness: 1 ▪ PC: 2 ▪ Neutrality: 4 ▪ Correctness: 1

3. Alt text **Short description (metadata):** Liniendiagramm. Titel: Biden is more unpopular than his predecessors. Untertitel: Net popularity ratings of American presidents (approval minus disapproval), in %. Waagrechte Achse: Wochen im Amt von 1 bis 417. Senkrechte Achse: Ausschnitt von minus 40 bis 80 %. Daten: Wöchentliche Werte. Fünf Linien: Biden (dunkelblau), Bush (türkis), Clinton (orange), Obama (rosa), Trump (gelb). **Short description (overview):** Alle Präsidenten starten mit positiven Nettobewertungen (Approval minus Disapproval), wobei Bush anfangs die höchste und Trump die niedrigste Bewertung aufweist. Biden, Clinton und Trump weisen einen negativen Durchschnittswert über weite Strecken auf, während Bush und Obama grösstenteils positive Bewertungen behalten. Biden hat in seiner bisherigen Amtszeit die durchweg negativsten Bewertungen gezeigt. **Long description:** Bush beginnt bei über 30 Prozent und erreicht nach etwa 35 Wochen mit fast 80 Prozent seinen Höhepunkt, fällt danach kontinuierlich und wechselt nach etwa 180 Wochen in den negativen Bereich. Clinton und Obama starten mit über 20 Prozent, fallen bis etwa Woche 40, zeigen danach eine mittlere Erholung und bleiben weitgehend im positiven oder leicht negativen Bereich. Trump startet nahe Null und bewegt sich über seine gesamte Amtszeit im negativen Bereich, grösstenteils zwischen minus 10 und minus 20 Prozent. Biden beginnt bei 20 Prozent, sinkt schnell und verharrt ab Woche 30 unter der Nulllinie, meist zwischen minus 10 und minus 20 Prozent (Stand Woche 161).	**SBERT:** 0.76 **LLM as Judge:** *(n=1)* ▪ Clarity: 5 ▪ Completeness: 3 ▪ Conciseness: 1 ▪ PC: 5 ▪ Neutrality: 5 ▪ Correctness: 2
4. Alt text **Short description (metadata):** Liniendiagramm. Titel: Biden is more unpopular than his predecessors. Untertitel: Net popularity ratings of American presidents (approval minus disapproval), in %. Waagerechte Achse: Zeitraum 1 bis 417 Wochen im Amt. Senkrechte Achse: Ausschnitt minus 40 bis 80 Prozent. Daten: Wöchentliche Werte. Fünf Linien: Biden (dunkelblau), Bush (türkis), Clinton (beige), Obama (rosa), Trump (hellgelb). **Short description (overview):** Die Netto-Popularitätsbewertungen der Präsidenten begannen alle positiv, außer Trump. Bush und Clinton erreichten früh die höchsten positiven Werte. Im späteren Verlauf fielen Bush und Obama in den negativen Bereich. Biden verzeichnete die schlechtesten Werte unter allen verglichenen Präsidenten. **Long description:** Biden startete bei plus zwanzig Prozent und sank konstant, um die dreißigste Woche herum in den negativen Bereich und erreichte um die achtzigste Woche herum einen Tiefstwert von etwa minus zwanzig Prozent. Bush erreichte nach vierunddreissig Wochen einen Höchstwert von fast achtzig Prozent und sank danach stark ab, um etwa die 170. Woche herum in den negativen Bereich zu gelangen. Clinton begann bei plus fünfundzwanzig Prozent, sank in negativen Bereich, verharrte dort bis etwa der zwanzigsten Woche und pendelte danach zwischen plus dreißig und minus zwanzig. Obama startete bei etwas über vierzig Prozent, sank stark, kreuzte ab etwa der 75. Woche die Nulllinie nach unten, pendelte und stieg am Ende wieder in den positiven Bereich. Trump startete leicht negativ und bewegte sich nahezu konstant zwischen minus fünfzehn und minus fünf Prozent.	**SBERT:** 0.75 **LLM as Judge:** *(n=1)* ▪ Clarity: 4 ▪ Completeness: 2 ▪ Conciseness: 1 ▪ PC: 5 ▪ Neutrality: 4 ▪ Correctness: 2

5. Alt text **Short description (metadata):** Liniendiagramm. Titel: Biden is more unpopular than his predecessors. Untertitel: Net popularity ratings of American presidents (approval minus disapproval), in %. Waagrechte Achse: Wochen im Amt von 1 bis 417. Senkrechte Achse: Ausschnitt Index von minus 40 bis 80 Prozentpunkten. Daten: Wöchentliche Werte. Fünf Linien: Biden (dunkelblau), Bush (hellgrün), Clinton (orange), Obama (rosa), Trump (hellbraun). **Short description (overview):** Die Popularitätsbewertungen aller Präsidenten beginnen positiv oder nahe Null, mit Ausnahme von Trump. Im Laufe der Zeit sinken die Werte für alle Präsidenten, wobei Bush zunächst einen sehr starken Anstieg und später einen starken Abfall verzeichnet. Biden liegt durchgehend im negativen Bereich und am niedrigsten unter den Präsidenten in seiner Amtszeit. **Long description:** Bush beginnt positiv bei etwa 35 Prozentpunkten und steigt bis Woche 38 auf über 79 Prozentpunkte, bevor er kontinuierlich sinkt und bei 417 Wochen im Amt bei etwa minus 40 Prozentpunkten endet. Clinton beginnt positiv bei unter 30 Prozentpunkten, sinkt kurzzeitig in den negativen Bereich und bewegt sich dann zwischen 10 und 35 Prozentpunkten. Obama startet bei knapp über 40 Prozentpunkten und sinkt stetig, wobei er die Nulllinie mehrfach kreuzt und bei 417 Wochen im Amt bei etwa 17 Prozentpunkten endet. Trump startet als einziger Präsident negativ, pendelt zwischen minus 5 und minus 20 Prozentpunkten und endet in Woche 209 bei etwa minus 17 Prozentpunkten. Biden beginnt positiv bei etwas über 20 Prozentpunkten und unterschreitet die Nulllinie um Woche 30. Er verbleibt in der Folge im negativen Bereich zwischen minus 7 und minus 20 Prozentpunkten bis zum Ende der Aufzeichnung in Woche 161.	**SBERT:** 0.74 **LLM as Judge:** *(n=1)* ▪ Clarity: 5 ▪ Completeness: 5 ▪ Conciseness: 1 ▪ PC: 3 ▪ Neutrality: 3 ▪ Correctness: 2
6. Alt text **Short description (metadata):** Liniendiagramm. Titel: Biden is more unpopular than his predecessors. Untertitel: Net popularity ratings of American presidents (approval minus disapproval), in %. Waagrechte Achse: Zeitraum 1 bis 417 Wochen im Amt. Senkrechte Achse: Ausschnitt minus 40 bis 80 Prozent. Daten: Wöchentliche Werte. Fünf Linien: Biden (dunkelblau), Bush (Hellgrün), Clinton (Orange), Obama (Rosa), Trump (Hellbraun). **Short description (overview):** Die Popularitätswerte aller Präsidenten beginnen positiv, mit Ausnahme von Trump. Bush erreicht das höchste Popularitätsniveau. Biden und Trump liegen durchgehend im negativen Bereich, während Bush, Clinton und Obama zwischen Plus 80 und Minus 40 schwanken. Biden befindet sich unter den Vorgängern grösstenteils auf dem tiefsten Niveau. **Long description:** Biden beginnt bei etwa plus 20 Prozent und sinkt bis zur Woche 161 auf etwa minus 15 Prozent. Bush startet bei etwa plus 35 Prozent und steigt bis Woche 38 auf fast plus 80 Prozent, bevor er bis auf minus 35 Prozent in Woche 372 fällt. Clinton beginnt bei etwa plus 25 Prozent, sinkt bis Woche 16 auf minus 5 Prozent und steigt danach kontinuierlich auf bis zu plus 30 Prozent in Woche 407. Obama startet bei plus 43 Prozent und sinkt bis auf minus 12 Prozent in Woche 319, gefolgt von einem Anstieg auf plus 17 Prozent bis zum Ende. Trump beginnt leicht negativ und bewegt sich im ersten Jahr zwischen minus vier und minus 17 Prozent.	**SBERT:** 0.72 **LLM as Judge:** *(n=1)* ▪ Clarity: 2 ▪ Completeness: 2 ▪ Conciseness: 1 ▪ PC: 2 ▪ Neutrality: 5 ▪ Correctness: 2

7. Alt text **Short description (metadata):** Liniendiagramm. Titel: Biden is more unpopular than his predecessors. Untertitel: Net popularity ratings of American presidents (approval minus disapproval), in %. Waagrechte Achse: Zeitraum 1 bis 417 Wochen im Amt. Senkrechte Achse: Ausschnitt minus vierzig bis achtzig Prozent. Daten: Wöchentliche Werte. Fünf Linien: Biden (dunkelblau), Bush (Türkis), Clinton (Orange), Obama (Rosa), Trump (Gelb). **Short description (overview):** Die Zustimmung für Präsident Bush begann hoch und blieb lange positiv, während Obama und Clinton mit positiven, aber sinkenden Werten starteten und Trump und Biden (am niedrigsten im Vergleich) mit gemischter oder negativer Zustimmung begannen. Biden bleibt als einziger Präsident konstant und deutlich im negativen Bereich; die anderen Präsidenten hatten positive Phasen. Die Zustimmung für Bush war bei Weitem am höchsten. **Long description:** Bush begann mit etwa fünfunddreissig Prozent Zustimmung, stieg kurzzeitig auf achtzig Prozent und sank dann stetig auf etwa minus vierzig Prozent. Obama begann bei über vierzig Prozent, sank bis Wochenmitte unter Null, stieg dann leicht an und endete bei etwa siebzehn Prozent. Clinton begann bei rund fünfundzwanzig Prozent, sank leicht unter die Null-Linie und stieg dann kontinuierlich bis auf über dreissig Prozent. Trump startete leicht negativ, erreichte ein Maximum von etwa minus sieben Prozent und ein Minimum von minus zwanzig Prozent. Biden startete bei zwanzig Prozent und sank konstant auf etwa minus sechzehn Prozent, den niedrigsten Endwert im Vergleich.	**SBERT:** 0.72 **LLM as Judge:** *(n=1)* ▪ Clarity: 4 ▪ Completeness: 4 ▪ Conciseness: 1 ▪ PC: 5 ▪ Neutrality: 5 ▪ Correctness: 3
8. Alt text **Short description (metadata):** Liniendiagramm. Titel: Biden is more unpopular than his predecessors. Untertitel: Net popularity ratings of American presidents (approval minus disapproval), in %. Waagerechte Achse: Wochen im Amt von 1 bis 417. Senkrechte Achse: Netto-Popularitätswerte (Zustimmung minus Ablehnung) von minus 40 bis 80 Prozent. Daten: Wöchentliche Werte. Fünf Linien: Biden (dunkelblau), Bush (türkis), Clinton (orange), Obama (rosa), Trump (gelb). **Short description (overview):** Während Bush und Clinton überwiegend positive Popularitätswerte aufweisen und Obama sich zu Beginn im positiven Bereich hält, zeigen Biden und Trump durchgängig negative bis neutrale Werte, wobei Biden durchwegs im negativen Bereich liegt. Bush demonstriert die höchsten Popularitätswerte der fünf Präsidenten in den ersten vier Jahren seiner Amtszeit. **Long description:** Biden startet bei etwa 20 Prozent und sinkt stetig, wobei er ab Woche 29 ins Negative fällt und zwischen minus 10 und minus 20 Prozent verbleibt. Bush beginnt bei 35 Prozent, steigt extrem bis auf 80 Prozent (um Woche 34) und sinkt danach kontinuierlich bis auf rund minus 40 Prozent. Clinton beginnt bei 25 Prozent, fällt kurz ins Negative, steigt dann stetig an und verbleibt oberhalb der Nulllinie, nahe 30 Prozent zum Ende der Daten. Obama startet hoch bei 43 Prozent, fällt rasch unter 20 Prozent und pendelt im späteren Verlauf zwischen 15 Prozent und minus 15 Prozent. Trump startet bei minus einem Prozent und verbleibt überwiegend zwischen minus 5 und minus 20 Prozent.	**SBERT:** 0.69 **LLM as Judge:** *(n=1)* ▪ Clarity: 5 ▪ Completeness: 4 ▪ Conciseness: 1 ▪ PC: 4 ▪ Neutrality: 4 ▪ Correctness: 3

9. Alt text **Short description (metadata):** Liniendiagramm. Titel: Biden is more unpopular than his predecessors. Untertitel: Net popularity ratings of American presidents (approval minus disapproval), in %. Waagerechte Achse: Wochen im Amt von null bis 417. Senkrechte Achse: Netto-Popularitätsbewertungen von minus 40 bis 80 Prozent. Daten: Wöchentliche Werte. Fünf Linien: Biden (dunkelblau), Bush (hellgrün), Clinton (orange), Obama (rosa), Trump (hellbraun). **Short description (overview):** Präsident Bush startete mit der höchsten Popularitätsbewertung der Gruppe und behielt diese über einen längeren Zeitraum. Biden weist durchgehend die niedrigsten Popularitätswerte auf. Alle Präsidenten sahen im Laufe ihrer Amtszeit einen generellen Rückgang ihrer Popularitätsbewertung. **Long description:** Präsident Bush begann mit über 80 Prozent und sank graduell, blieb aber lange positiv, bevor er nach 300 Wochen stark sank und bei etwa minus 35 Prozent endete. Obama startete fast bei 45 Prozent, sank unter null, erholte sich im Verlauf und schloss über 15 Prozent. Clinton und Trump starteten um null oder leicht darunter, mit Clinton häufiger im positiven Bereich. Biden begann bei etwa 20 Prozent und sank schnell, blieb fast durchgehend unter null und endete bei rund minus 15 Prozent.	**SBERT:** 0.65 **LLM as Judge:** *(n=1)* ▪ Clarity: 5 ▪ Completeness: 4 ▪ Conciseness: 2 ▪ PC: 3 ▪ Neutrality: 5 ▪ Correctness: 1
10. Alt text **Short description (metadata):** Liniendiagramm. Titel: Biden is more unpopular than his predecessors. Untertitel: Net popularity ratings of American presidents (approval minus disapproval), in %. Waagerechte Achse: Wochen im Amt von 1 bis 417. Senkrechte Achse: Netto-Popularitätswerte von minus 40 bis 80. Daten: Wöchentliche Werte. Fünf Linien: Biden (dunkelblau), Bush (hellgrün), Clinton (orange), Obama (rosa), Trump (hellbraun/gelb). **Short description (overview):** Während George W. Bush und Clinton anfänglich hohe Popularitätswerte aufweisen und deutlich über der Null-Linie liegen, starten Obama und Biden hoch, fallen aber schnell auf neutrale oder negative Werte. Biden bleibt während seiner gemessenen Amtszeit konsequent im negativen Bereich, was ihn im Schnitt unpopulärer macht als seine Vorgänger. Bushs Popularität sank nach einem anfänglichen Hoch am stärksten. **Long description:** Bushs Popularität startet bei rund 35 und steigt auf über 80 in Woche 34, bevor sie danach stark und relativ stetig sinkt und ab Woche 170 im negativen Bereich um minus 20 bis minus 40 verbleibt. Clinton beginnt bei rund 26, sinkt erst auf minus 7 und steigt bis zum Ende des gemessenen Zeitraums auf über 30. Obama startet bei über 43, sinkt bis Woche 80 auf rund minus 5, steigt bis Woche 104 wieder auf über 7 und verbleibt danach grösstenteils im negativen Bereich, nähert sich aber gegen Ende der Amtszeit wieder der Null-Linie. Trump beginnt bei rund minus 1 und schwankt meist zwischen minus 5 und minus 20 bis zu Woche 209. Biden beginnt bei rund 20 und fällt rasch ab Woche 40 in den negativen Bereich zwischen minus 10 und minus 16, wo er während der gesamten gemessenen Zeitspanne verbleibt.	**SBERT:** 0.64 **LLM as Judge:** *(n=1)* ▪ Clarity: 4 ▪ Completeness: 5 ▪ Conciseness: 1 ▪ PC: 5 ▪ Neutrality: 5 ▪ Correctness: 2

0819c8effbf081938ef522a36909fa85

Golden standard

Short description (metadata): Liniendiagramm. Titel: KI-Ingenieure verdienen in den USA immer mehr. Untertitel: Medianjahreslohn in den USA, in Tausend Dollar. Waagrechte Achse: Zeitraum August 2022 bis Januar 2024. Senkrechte Achse: 0 bis 300'000 Dollar. Daten: Monatliche Werte. Zwei Linien: KI-Ingenieure (blau), Nicht-KI-Ingenieure (türkis).

Short description (overview): Das Medianjahresgehalt von Nicht-KI-Ingenieuren bleibt auf einem ähnlichen Niveau, während das von KI-Ingenieuren mit leichten Schwankungen steigt und stets über dem der Nicht-KI-Ingenieure liegt.

Long description: KI-Ingenieure: Medianjahreslohn steigt von 230'000 im August 2022 auf 270'000 Dollar im Januar 2024. Nicht-KI-Ingenieure: Der Lohn liegen meist zwischen 165'000 und 180'000, mit einem Tief von etwa 155'000 im Dezember 2022 und einem Hoch von 180'000 im Dezember 2023. Die Gehaltslücke variiert zwischen knapp 70'000 (November 2022) und knapp 100'000 (März 2023).

1. Alt text

Short description (metadata): Liniendiagramm. Titel: Copy of AI engineers are earning more and more in the US. (Untertitel: Median annual salary in the USA, figures in dollars (in thousands)). Waagerechte Achse: Zeitraum September 2022 bis Januar 2024. Senkrechte Achse: Ausschnitt null bis 300 tausend. Daten: Monatliche Werte. Zwei Linien: AI engineers (dunkelblau), Nicht-KI Ingenieure (türkis).

Short description (overview): Über den gesamten Zeitraum liegt das Medianjahresgehalt von AI-Ingenieuren deutlich über dem von Nicht-KI-Ingenieuren. Die Gehälter von AI-Ingenieuren zeigen stärkere Schwankungen, weisen aber insgesamt einen steigenden Trend auf, während die Gehälter von Nicht-KI-Ingenieuren stabiler sind und ebenfalls leicht steigende Tendenz zeigen.

Long description: AI-Ingenieure starten bei rund 231 Tausend und steigen mit starken Schwankungen, darunter ein höchster Wert von rund 270 Tausend im März und April 2023, auf rund 270 Tausend im Januar 2024. Nicht-KI-Ingenieure starten bei rund 174 Tausend und zeigen einen stabileren Anstieg. Sie verzeichnen ein Minimum von rund 156 Tausend im Dezember 2022 und steigen bis Januar 2024 auf rund 177,5 Tausend, wobei sie bis November 2023 das höchste Niveau erreichen.

SBERT: 0.74

LLM as Judge: *(n=1)*

- Clarity: 5
- Completeness: 4
- Conciseness: 1
- PC: 5
- Neutrality: 5
- Correctness: 3

2. Alt text **Short description (metadata):** Liniendiagramm. Titel: Copy of AI engineers are earning more and more in the US. Untertitel: Median annual salary in the USA, figures in dollars (in thousands). Waagrechte Achse: Zeitraum September 2022 bis Januar 2024. Senkrechte Achse: Ausschnitt von 0 bis 300 (in Tausend Dollar). Daten: Monatliche Werte. Zwei Linien: AI engineers (dunkelblau), Nicht-KI Ingenieure (türkis). **Short description (overview):** Über den gesamten Zeitraum zeigt das mittlere jährliche Gehalt der AI-Ingenieure ein deutlich höheres Niveau und eine stärkere Schwankung im Vergleich zu den Nicht-KI-Ingenieuren. Die Gehälter beider Gruppen weisen insgesamt einen steigenden Trend auf, wobei die Differenz konstant hoch bleibt. **Long description:** AI-Ingenieure beginnen bei etwa 231 und steigen bis Januar 2024 auf 270 (in Tausend Dollar), mit einem markanten Hoch im März und April 2023. Nicht-KI-Ingenieure starten bei 174 und steigen bis Januar 2024 auf 177.5, nach einem Zwischentief im Dezember 2022 und einem Hoch im vierten Quartal 2023.	**SBERT:** 0.71 **LLM as Judge:** *(n=1)* ▪ Clarity: 5 ▪ Completeness: 4 ▪ Conciseness: 2 ▪ PC: 5 ▪ Neutrality: 5 ▪ Correctness: 5
3. Alt text **Short description (metadata):** Liniendiagramm. Titel: Copy of AI engineers are earning more and more in the US. Untertitel: Median annual salary in the USA, figures in dollars (in thousands). Waagerechte Achse: Zeitraum September 2022 bis Januar 2024. Senkrechte Achse: Ausschnitt 0 bis 300 tausend Dollar. Daten: Monatliche Werte. Zwei Linien: AI engineers (Dunkelblau), Nicht-KI Ingenieure (Türkis). **Short description (overview):** Die durchschnittlichen Jahresgehälter von AI-Ingenieuren liegen während des gesamten Zeitraums deutlich über denen der Nicht-KI-Ingenieure. Die Gehälter beider Gruppen weisen eine insgesamt steigende Tendenz auf, jedoch mit stärkeren Schwankungen bei den AI-Ingenieuren. **Long description:** Die Gehälter der AI-Ingenieure schwanken zwischen 231 und 270 Tausend Dollar, mit einem deutlichen Anstieg zum Ende hin. Die Gehälter der Nicht-KI-Ingenieure liegen konstant niedriger, sie beginnen bei 174 Tausend Dollar und steigen leicht und stabil auf 177,5 Tausend Dollar, mit einer geringen Phase des Sinkens zu Beginn. Die Spanne zwischen den Gehaltsgruppen bleibt durchgehend beträchtlich.	**SBERT:** 0.7 **LLM as Judge:** *(n=1)* ▪ Clarity: 5 ▪ Completeness: 3 ▪ Conciseness: 2 ▪ PC: 5 ▪ Neutrality: 5 ▪ Correctness: 5
4. Alt text **Short description (metadata):** Liniendiagramm. Titel: Copy of AI engineers are earning more and more in the US. Untertitel: Median annual salary in the USA, figures in dollars (in thousands). Waagerechte Achse: Zeitraum September 2022 bis Januar 2024. Senkrechte Achse: Ausschnitt 0 bis 300 tausend Dollar. Daten: Monatliche Werte. Zwei Linien: AI engineers (dunkelblau), Nicht-KI Ingenieure (türkis). **Short description (overview):** Die Gehälter von AI Engineers liegen durchgehend deutlich über denen von Nicht-KI Ingenieuren. Beide Gehälter zeigen über den gesamten Zeitraum eine steigende Tendenz, wobei die Gehälter der AI Engineers jedoch eine höhere Volatilität aufweisen. **Long description:** Die Gehälter der AI Engineers beginnen im September 2022 bei etwa 253 tausend und steigen mit starken Schwankungen auf 270 tausend im Januar 2024. Die Gehälter der Nicht-KI Ingenieure beginnen bei 170 tausend und zeigen einen moderateren Aufwärtstrend, mit einem Tiefststand um 156 tausend im Dezember 2022, bevor sie auf 177 tausend im Januar 2024 steigen.	**SBERT:** 0.7 **LLM as Judge:** *(n=1)* ▪ Clarity: 5 ▪ Completeness: 4 ▪ Conciseness: 1 ▪ PC: 5 ▪ Neutrality: 5 ▪ Correctness: 5

5. Alt text **Short description (metadata):** Liniendiagramm. Titel: Copy of AI engineers are earning more and more in the US. Untertitel: Median annual salary in the USA, figures in dollars (in thousands). Waagerechte Achse: Zeitraum September 2022 bis Januar 2024. Senkrechte Achse: Ausschnitt 0 bis 300. Daten: Monatliche Werte. Zwei Linien: AI engineers (dunkelblau), Nicht-KI Ingenieure (türkis). **Short description (overview):** Die Gehälter von AI Engineers liegen durchweg deutlich über denen von Nicht-KI Ingenieuren und entwickeln sich volatiler. Beide Gehaltsgruppen zeigen über den gesamten Zeitraum einen leichten Aufwärtstrend. **Long description:** Die Gehälter der Nicht-KI Ingenieure beginnen bei etwa 170.000, sinken bis Dezember 2022 auf rund 156.000 und steigen danach relativ stetig bis Januar 2024 auf rund 177.500. Die Gehälter der AI Engineers beginnen bei etwa 231.000, zeigen stärkere Schwankungen, mit Höhepunkten um März/April 2023 bei rund 270.000 und einem Tiefpunkt im Mai 2023 bei rund 243.000, und steigen bis Januar 2024 erneut auf rund 270.000.	**SBERT:** 0.69 **LLM as Judge:** *(n=1)* ▪ Clarity: 5 ▪ Completeness: 5 ▪ Conciseness: 2 ▪ PC: 5 ▪ Neutrality: 5 ▪ Correctness: 4
6. Alt text **Short description (metadata):** Liniendiagramm. Titel: Copy of AI engineers are earning more and more in the US. Untertitel: Median annual salary in the USA, figures in dollars (in thousands). Waagrechte Achse: Zeitraum September 2022 bis Januar 2024. Senkrechte Achse: Ausschnitt 0 bis 300 tausend. Daten: Monatliche Werte. Zwei Linien: AI engineers (dunkelblau), Nicht-KI Ingenieure (türkis). **Short description (overview):** Die Gehälter von AI engineers liegen durchgängig deutlich über denen von Nicht-KI Ingenieuren. Beide Gehaltsgruppen zeigen über den gesamten Zeitraum eine leicht steigende Tendenz, wobei die Gehälter der AI engineers stärker schwanken. **Long description:** Die Gehälter der AI engineers beginnen im September 2022 bei etwa 253 Tausend und steigen mit starken Schwankungen bis Januar 2024 auf 270 Tausend. Die Gehälter der Nicht-KI Ingenieure beginnen bei 170 Tausend und steigen deutlich gleichmässiger bis auf 177,5 Tausend im Januar 2024.	**SBERT:** 0.66 **LLM as Judge:** *(n=1)* ▪ Clarity: 5 ▪ Completeness: 3 ▪ Conciseness: 2 ▪ PC: 5 ▪ Neutrality: 3 ▪ Correctness: 4
7. Alt text **Short description (metadata):** Liniendiagramm. Titel: Copy of AI engineers are earning more and more in the US. Untertitel: Median annual salary in the USA, figures in dollars (in thousands). Waagerechte Achse: Zeitraum September 2022 bis Januar 2024. Senkrechte Achse: Ausschnitt 0 bis 300 tausend Dollar. Daten: Monatliche Werte. Zwei Linien: AI engineers (blau), Nicht-KI Ingenieure (türkis). **Short description (overview):** Die Gehälter von AI engineers liegen durchweg deutlich höher als die von Nicht-KI Ingenieuren, wobei beide Gruppen im betrachteten Zeitraum tendenziell steigende Mediansaläre verzeichnen. Die Gehälter der AI engineers zeigen jedoch deutlich stärkere Schwankungen als die konstanten Gehälter der Nicht-KI Ingenieure. **Long description:** Die Gehälter der AI engineers beginnen im September 2022 bei rund 253.000 Dollar und steigen bis März 2023 auf 270.000 Dollar, fallen anschliessend stark ab, erholen sich aber wieder und erreichen im Januar 2024 mit 270.000 Dollar den höchsten Stand. Die Gehälter der Nicht-KI Ingenieure beginnen bei 170.000 Dollar und zeigen eine konstante Steigung mit minimalen Schwankungen, wobei sie 2024 bei 177.500 Dollar enden.	**SBERT:** 0.65 **LLM as Judge:** *(n=1)* ▪ Clarity: 4 ▪ Completeness: 3 ▪ Conciseness: 1 ▪ PC: 5 ▪ Neutrality: 5 ▪ Correctness: 3

8. Alt text **Short description (metadata):** Liniendiagramm. Titel: Copy of AI engineers are earning more and more in the US. Untertitel: Median annual salary in the USA, figures in dollars (in thousands). Waagerechte Achse: Zeitraum September 2022 bis Januar 2024. Senkrechte Achse: Ausschnitt 0 bis 300 tausend Dollar. Daten: Monatliche Werte. Zwei Linien: AI engineers (dunkelblau), Nicht-KI Ingenieure (türkis). **Short description (overview):** Die Gehälter von AI engineers liegen durchweg deutlich über denen der Nicht-KI Ingenieure. Während die Gehälter für AI engineers über den gesamten Zeitraum stark schwanken und einen generellen Aufwärtstrend zeigen, verlaufen die Gehälter für Nicht-KI Ingenieure wesentlich stabiler und steigen moderat. **Long description:** AI engineers starten bei rund 231.000 Dollar und steigen nach erheblichen Schwankungen (Höhepunkt März/April 2023 bei 270.000 Dollar, Tiefpunkt Mai 2023 bei 243.000 Dollar) auf 270.000 Dollar im Januar 2024. Nicht-KI Ingenieure bewegen sich zwischen 156.250 und 179.000 Dollar, beginnend bei 174.000 Dollar und endend bei 177.500 Dollar mit einem stetigen, aber geringen Anstieg über den gesamten Zeitraum.	**SBERT:** 0.64 **LLM as Judge:** *(n=1)* ▪ Clarity: 5 ▪ Completeness: 5 ▪ Conciseness: 2 ▪ PC: 5 ▪ Neutrality: 2 ▪ Correctness: 3
9. Alt text **Short description (metadata):** Liniendiagramm. Titel: Copy of AI engineers are earning more and more in the US. Untertitel: Median annual salary in the USA, figures in dollars (in thousands). Waagerechte Achse: Zeitraum September 2022 bis Januar 2024. Senkrechte Achse: Ausschnitt 0 bis 300 tausend Dollar. Daten: Monatliche Werte. Zwei Linien: AI engineers (dunkelblau), Nicht-KI Ingenieure (türkis). **Short description (overview):** Die Gehälter von AI Engineers liegen durchgehend deutlich über denen von Nicht-KI Ingenieuren. Beide Gehälter zeigen über den gesamten Zeitraum von September 2022 bis Januar 2024 einen steigenden Trend mit Schwankungen, wobei die Gehälter der AI Engineers stärkere Fluktuationen aufweisen. **Long description:** Die Gehälter der AI Engineers beginnen im September 2022 bei etwa 253.167 und steigen bis März 2023 auf 270.000, sinken kurz darauf im Mai 2023 auf 243.000 und steigen bis Januar 2024 erneut auf 270.000 tausend Dollar. Die Gehälter der Nicht-KI Ingenieure beginnen im September 2022 bei 170.000, sinken kurzfristig auf 156.250 im Dezember 2022 und steigen danach relativ kontinuierlich bis November 2023 auf 179.000, bevor sie im Januar 2024 auf 177.500 sinken.	**SBERT:** 0.62 **LLM as Judge:** *(n=1)* ▪ Clarity: 5 ▪ Completeness: 5 ▪ Conciseness: 1 ▪ PC: 5 ▪ Neutrality: 5 ▪ Correctness: 5

10. Alt text **Short description (metadata):** Liniendiagramm. Titel: Copy of AI engineers are earning more and more in the US. Untertitel: Median annual salary in the USA, figures in dollars (in thousands). Waagerechte Achse: Zeitraum September 2022 bis Januar 2024. Senkrechte Achse: Ausschnitt 0 bis 300 tausend Dollar. Daten: Monatliche Werte. Zwei Linien: AI engineers (dunkelblau), Nicht-KI Ingenieure (türkis). **Short description (overview):** Die Gehälter von AI engineers liegen durchgängig höher als die von Nicht-KI Ingenieuren. Beide Gruppen zeigen über den betrachteten Zeitraum einen steigenden Gehaltstrend, wobei die Gehälter der AI engineers stärker schwanken, aber insgesamt ein höheres Niveau erreichen. **Long description:** $AI engineers$ beginnen bei rund 253 Tausend Dollar im September 2022, steigen kurz auf 270 Tausend Dollar im März 2023, sinken dann aber auf etwa 243 Tausend Dollar im Mai 2023, um bis Januar 2024 kontinuierlich auf 270 Tausend Dollar zu steigen. Die Gehälter der $Nicht-KI Ingenieure$ weisen geringere Schwankungen auf, beginnen bei rund 170 Tausend Dollar im September 2022 und steigen fast kontinuierlich auf etwa 178 Tausend Dollar im Januar 2024.	**SBERT:** 0.59 **LLM as Judge:** *(n=1)* ▪ Clarity: 4 ▪ Completeness: 5 ▪ Conciseness: 2 ▪ PC: 5 ▪ Neutrality: 5 ▪ Correctness: 3